改定（令和７年 12 月）		現行（令和６年３月）
付属資料１　管理ファイルの DTD		**付属資料１　管理ファイルの DTD**
（1）　測量情報管理ファイルの DTD		（1）　測量情報管理ファイルの DTD
付 1-1 測量情報管理ファイル（SURVEY.XML）の DTD（SURVEY05.DTD）は次による。 <!--SURVEY05.DTD / 2025/10--> <!ELEMENT SURVEY (基礎情報, 場所情報+, 測量情報+, 検定情報?, その他?, ソフトメーカ用TAG*)> <!ATTLIST SURVEY DTD_version CDATA #FIXED "05"> <!-- ********** --> <!-- 基礎情報 --> <!-- ********** --> <!ELEMENT 基礎情報 (適用要領基準, 助言番号, 作業規程名, 製品仕様書+, 第三者機関成果検定の有無, 基準点測量成果格納用フォルダ名?, 水準測量成果格納用フォルダ名?, 地形測量及び写真測量成果格納用フォルダ名?, 三次元点群測量成果格納用フォルダ名?, 路線測量成果格納用フォルダ名?, 河川測量成果格納用フォルダ名?, 用地測量成果格納用フォルダ名? , その他の応用測量成果格納用フォルダ名?, ドキュメント格納用フォルダ名?)> <!ELEMENT 適用要領基準 (#PCDATA)> <!ELEMENT 助言番号 (#PCDATA)> <!ELEMENT 作業規程名 (#PCDATA)> <!ELEMENT 製品仕様書 (製品仕様書名, 製品仕様書ファイル名+)> <!ELEMENT 製品仕様書名 (#PCDATA)> <!ELEMENT 製品仕様書ファイル名 (#PCDATA)> <!ELEMENT 第三者機関成果検定の有無 (#PCDATA)> <!ELEMENT 基準点測量成果格納用フォルダ名 (#PCDATA)> <!ELEMENT 水準測量成果格納用フォルダ名 (#PCDATA)> <!ELEMENT 地形測量及び写真測量成果格納用フォルダ名 (#PCDATA)> <!ELEMENT 三次元点群測量成果格納用フォルダ名 (#PCDATA)> <!ELEMENT 路線測量成果格納用フォルダ名 (#PCDATA)> <!ELEMENT 河川測量成果格納用フォルダ名 (#PCDATA)> <!ELEMENT 用地測量成果格納用フォルダ名 (#PCDATA)> <!ELEMENT その他の応用測量成果格納用フォルダ名 (#PCDATA)> <!ELEMENT ドキュメント格納用フォルダ名 (#PCDATA)> <!--**********-->	変更 変更 変更	付 1-1 測量情報管理ファイル（SURVEY.XML）の DTD（SURVEY04.DTD）は次による。 <!--SURVEY04.DTD / 2021/03--> <!ELEMENT SURVEY (基礎情報, 場所情報+, 測量情報+, 検定情報?, その他?, ソフトメーカ用TAG*)> <!ATTLIST SURVEY DTD_version CDATA #FIXED "04"> <!-- ********** --> <!-- 基礎情報 --> <!-- ********** --> <!ELEMENT 基礎情報 (適用要領基準, 助言番号, 作業規程名, 製品仕様書+, 第三者機関成果検定の有無, 基準点測量成果格納用フォルダ名?, 水準測量成果格納用フォルダ名?, 地形測量及び写真測量成果格納用フォルダ名?, 三次元点群測量成果格納用フォルダ名?, 路線測量成果格納用フォルダ名?, 河川測量成果格納用フォルダ名?, 用地測量成果格納用フォルダ名? , その他の応用測量成果格納用フォルダ名?, ドキュメント格納用フォルダ名?)> <!ELEMENT 適用要領基準 (#PCDATA)> <!ELEMENT 助言番号 (#PCDATA)> <!ELEMENT 作業規程名 (#PCDATA)> <!ELEMENT 製品仕様書 (製品仕様書名, 製品仕様書ファイル名+)> <!ELEMENT 製品仕様書名 (#PCDATA)> <!ELEMENT 製品仕様書ファイル名 (#PCDATA)> <!ELEMENT 第三者機関成果検定の有無 (#PCDATA)> <!ELEMENT 基準点測量成果格納用フォルダ名 (#PCDATA)> <!ELEMENT 水準測量成果格納用フォルダ名 (#PCDATA)> <!ELEMENT 地形測量及び写真測量成果格納用フォルダ名 (#PCDATA)> <!ELEMENT 三次元点群測量成果格納用フォルダ名 (#PCDATA)> <!ELEMENT 路線測量成果格納用フォルダ名 (#PCDATA)> <!ELEMENT 河川測量成果格納用フォルダ名 (#PCDATA)> <!ELEMENT 用地測量成果格納用フォルダ名 (#PCDATA)> <!ELEMENT その他の応用測量成果格納用フォルダ名 (#PCDATA)> <!ELEMENT ドキュメント格納用フォルダ名 (#PCDATA)> <!--**********-->

改定（令和７年 12 月）		現行（令和６年３月）
<!-- 場所情報 --> <!--**********--> <!ELEMENT 場所情報 (測量区域番号, 測量区域名?, 区域情報)> <!ELEMENT 測量区域番号 (#PCDATA)> <!ELEMENT 測量区域名 (#PCDATA)> <!--**********--> <!-- 区域情報 --> <!--**********--> <!ELEMENT 区域情報 (西側境界座標経度?, 東側境界座標経度?, 北側境界座標緯度?, 南側境界座標緯度?, 平面直角座標系?, 西側境界平面直角座標?, 東側境界平面直角座標?, 北側境界平面直角座標?, 南側境界平面直角座標?)> <!ELEMENT 西側境界座標経度 (#PCDATA)> <!ELEMENT 東側境界座標経度 (#PCDATA)> <!ELEMENT 北側境界座標緯度 (#PCDATA)> <!ELEMENT 南側境界座標緯度 (#PCDATA)> <!ELEMENT 平面直角座標系 (#PCDATA)> <!ELEMENT 西側境界平面直角座標 (#PCDATA)> 付 1-2 <!ELEMENT 東側境界平面直角座標 (#PCDATA)> <!ELEMENT 北側境界平面直角座標 (#PCDATA)> <!ELEMENT 南側境界平面直角座標 (#PCDATA)> <!-- ********** --> <!-- 測量情報 --> <!-- ********** --> <!ELEMENT 測量情報 (測量区分, 測量細区分, 測量記録フォルダパス名?, 測量成果フォルダパス名?, その他データフォルダパス名?, 測量区域 No, 等級精度, 画像種別?, 解像度?, 新規修正区分?, 面積?, 距離?, 点数?, モデル数? , 点密度?)> <!ELEMENT 測量区分 (#PCDATA)> <!ELEMENT 測量細区分 (#PCDATA)> <!ELEMENT 測量記録フォルダパス名 (#PCDATA)> <!ELEMENT 測量成果フォルダパス名 (#PCDATA)> <!ELEMENT その他データフォルダパス名 (#PCDATA)> <!ELEMENT 測量区域 No (#PCDATA)> <!-- ********** --> <!-- 等級精度 --> <!-- ********** --> <!ELEMENT 等級精度 (等級?, 地図情報レベル?)>	追加	<!-- 場所情報 --> <!--**********--> <!ELEMENT 場所情報 (測量区域番号, 測量区域名?, 区域情報)> <!ELEMENT 測量区域番号 (#PCDATA)> <!ELEMENT 測量区域名 (#PCDATA)> <!--**********--> <!-- 区域情報 --> <!--**********--> <!ELEMENT 区域情報 (西側境界座標経度?, 東側境界座標経度?, 北側境界座標緯度?, 南側境界座標緯度?, 平面直角座標系?, 西側境界平面直角座標?, 東側境界平面直角座標?, 北側境界平面直角座標?, 南側境界平面直角座標?)> <!ELEMENT 西側境界座標経度 (#PCDATA)> <!ELEMENT 東側境界座標経度 (#PCDATA)> <!ELEMENT 北側境界座標緯度 (#PCDATA)> <!ELEMENT 南側境界座標緯度 (#PCDATA)> <!ELEMENT 平面直角座標系 (#PCDATA)> <!ELEMENT 西側境界平面直角座標 (#PCDATA)> 付 1-2 <!ELEMENT 東側境界平面直角座標 (#PCDATA)> <!ELEMENT 北側境界平面直角座標 (#PCDATA)> <!ELEMENT 南側境界平面直角座標 (#PCDATA)> <!-- ********** --> <!-- 測量情報 --> <!-- ********** --> <!ELEMENT 測量情報 (測量区分, 測量細区分, 測量記録フォルダパス名?, 測量成果フォルダパス名?, その他データフォルダパス名?, 測量区域 No, 等級精度, 画像種別?, 解像度?, 新規修正区分?, 面積?, 距離?, 点数?, モデル数?)> <!ELEMENT 測量区分 (#PCDATA)> <!ELEMENT 測量細区分 (#PCDATA)> <!ELEMENT 測量記録フォルダパス名 (#PCDATA)> <!ELEMENT 測量成果フォルダパス名 (#PCDATA)> <!ELEMENT その他データフォルダパス名 (#PCDATA)> <!ELEMENT 測量区域 No (#PCDATA)> <!-- ********** --> <!-- 等級精度 --> <!-- ********** --> <!ELEMENT 等級精度 (等級?, 地図情報レベル?)>

改定（令和７年 12 月）		現行（令和６年３月）
<!ELEMENT 等級 (#PCDATA)> <!ELEMENT 地図情報レベル (#PCDATA)> <!ELEMENT 画像種別 (#PCDATA)> <!ELEMENT 解像度 (#PCDATA)> <!ELEMENT 新規修正区分 (#PCDATA)> <!ELEMENT 面積 (#PCDATA)> <!ELEMENT 距離 (#PCDATA)> <!ELEMENT 点数 (#PCDATA)> <!ELEMENT モデル数 (#PCDATA)> <!ELEMENT 点密度 (#PCDATA)> <!-- ********** --> <!-- 検定情報 --> <!-- ********** --> <!ELEMENT 検定情報 (測量成果検定証明書等のファイル名*)> <!ELEMENT 測量成果検定証明書等のファイル名 (#PCDATA)> <!-- ********** --> <!-- その他 --> <!-- ********** --> <!ELEMENT その他 (受注者説明文?, 予備*)> <!ELEMENT 受注者説明文 (#PCDATA)> <!ELEMENT 予備 (#PCDATA)> <!ELEMENT ソフトメーカ用 TAG (#PCDATA)>	追加	<!ELEMENT 等級 (#PCDATA)> <!ELEMENT 地図情報レベル (#PCDATA)> <!ELEMENT 画像種別 (#PCDATA)> <!ELEMENT 解像度 (#PCDATA)> <!ELEMENT 新規修正区分 (#PCDATA)> <!ELEMENT 面積 (#PCDATA)> <!ELEMENT 距離 (#PCDATA)> <!ELEMENT 点数 (#PCDATA)> <!ELEMENT モデル数 (#PCDATA)> <!-- ********** --> <!-- 検定情報 --> <!-- ********** --> <!ELEMENT 検定情報 (測量成果検定証明書等のファイル名*)> <!ELEMENT 測量成果検定証明書等のファイル名 (#PCDATA)> <!-- ********** --> <!-- その他 --> <!-- ********** --> <!ELEMENT その他 (受注者説明文?, 予備*)> <!ELEMENT 受注者説明文 (#PCDATA)> <!ELEMENT 予備 (#PCDATA)> <!ELEMENT ソフトメーカ用 TAG (#PCDATA)>

測量成果電子納品要領_付属資料【測量編】改定案対照表

改定（令和７年 12 月）		現行（令和６年３月）
付 1-3	変更	付 1-3

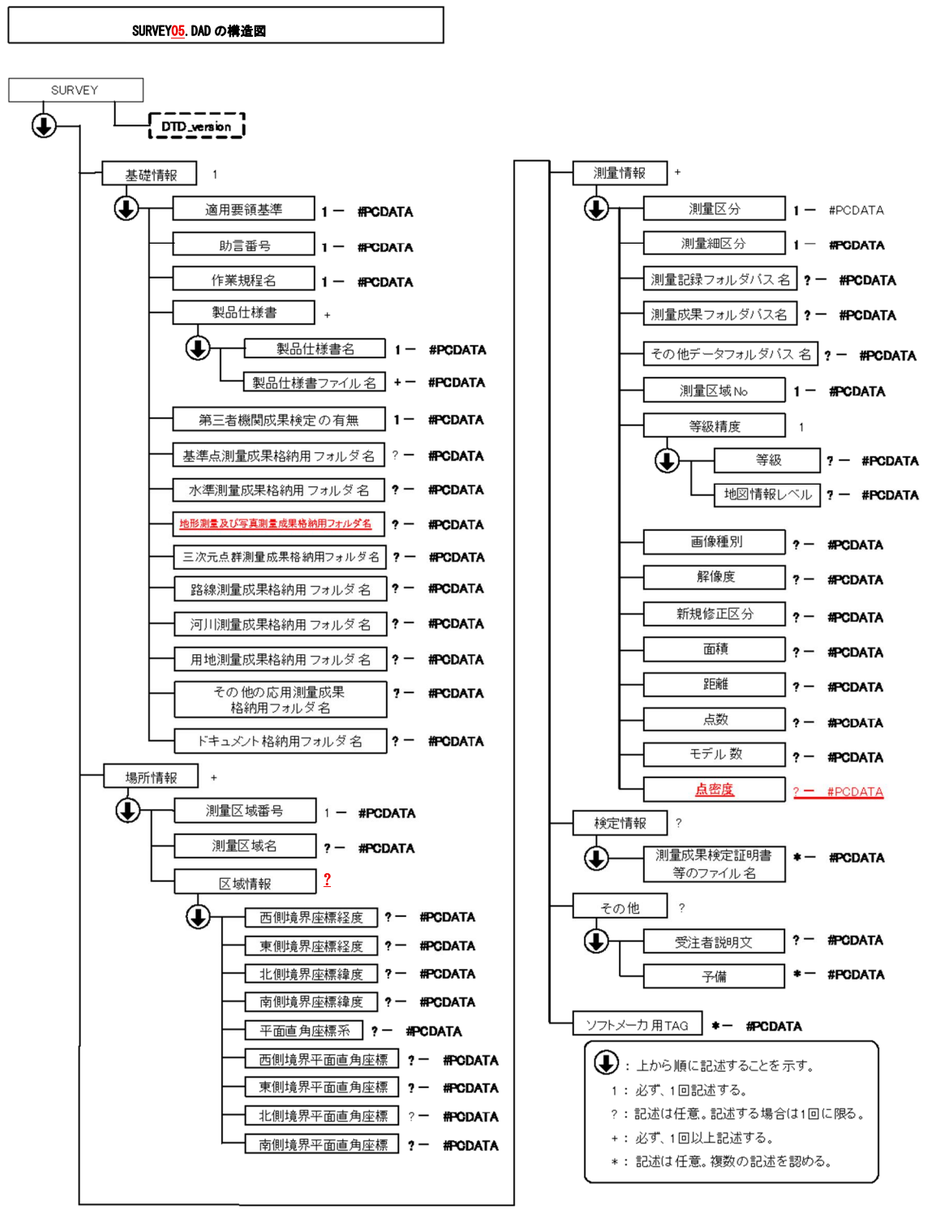

変更

追加

変更

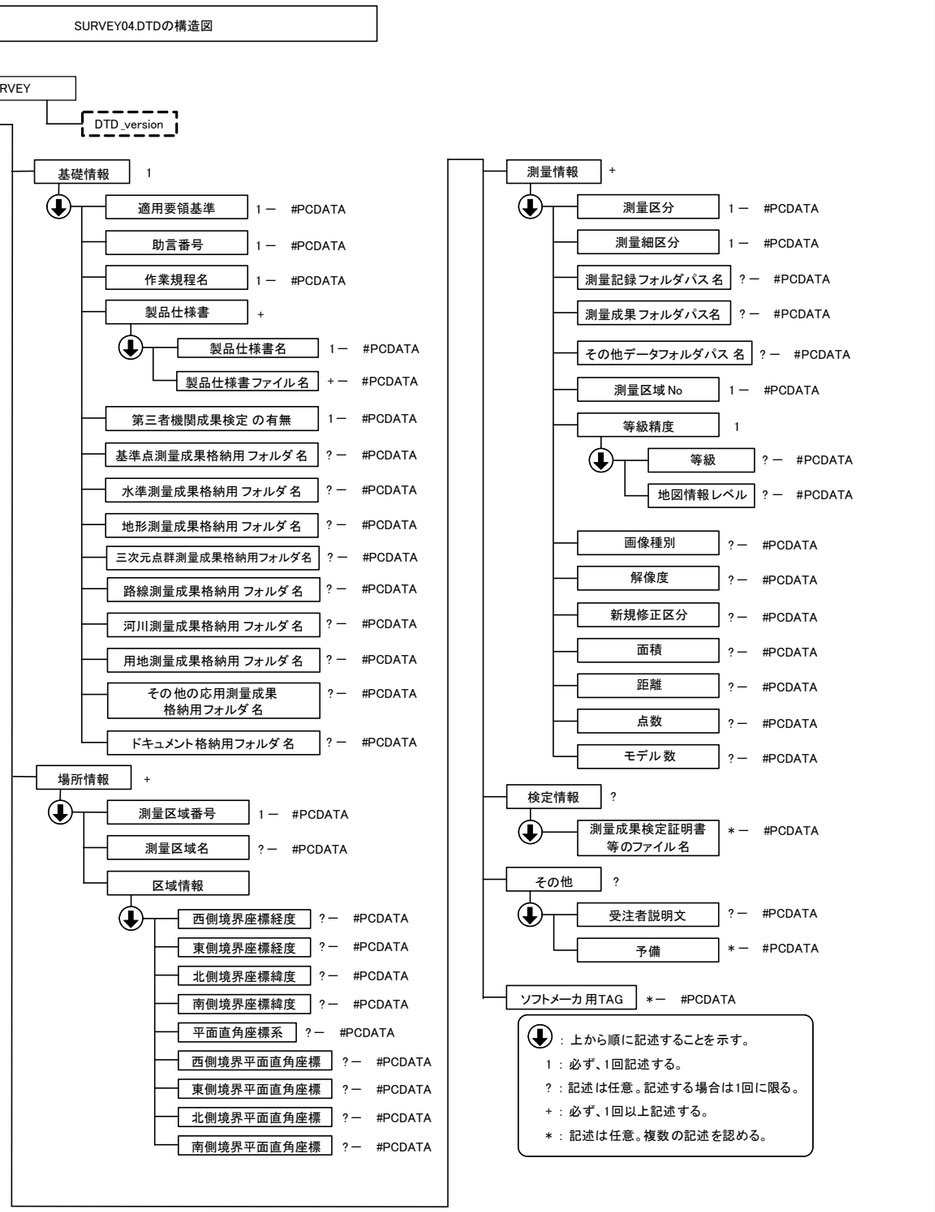

改定（令和７年 12 月）		現行（令和６年３月）
(2)　測量成果管理ファイルの DTD		(2)　測量成果管理ファイルの DTD
付 1-4 測量成果管理ファイル（基準点測量：SURV_KTN.XML、水準測量：SURV_SJN.XML、地形測量及び写真測量：SURV_CHI.XML、三次元点群測量：SURV_ SGT.XML、路線測量：SURV_RSN.XML、河川測量：SURV_KSN.XML、用地測量：SURV_YCH.XML、その他の応用測量：SURV_OYO.XML）の DTD（SURV_D03.DTD）は次による。 <!-- SURV_D03.DTD / 2008/12--> <!ELEMENT SURV_DATA (測量成果情報+, その他?, ソフトメーカ用 TAG*)> <!ATTLIST SURV_DATA DTD_version CDATA #FIXED "03"> <!-- ********** --> <!-- 測量成果情報 --> <!-- ********** --> <!ELEMENT 測量成果情報 (測量区分フォルダ名, 測量成果区分フォルダ名, 測量細区分フォルダ名?, 測量成果名称, 測量成果ファイル形式, 測量成果レコードフォーマット?, 測量成果作成ソフトウェア名?, 成果ファイル情報+)> <!ELEMENT 測量区分フォルダ名 (#PCDATA)> <!ELEMENT 測量成果区分フォルダ名 (#PCDATA)> <!ELEMENT 測量細区分フォルダ名 (#PCDATA)> <!ELEMENT 測量成果名称 (#PCDATA)> <!ELEMENT 測量成果ファイル形式 (#PCDATA)> <!ELEMENT 測量成果レコードフォーマット (#PCDATA)> <!ELEMENT 測量成果作成ソフトウェア名 (#PCDATA)> <!-- ********** --> <!-- 成果ファイル情報 --> <!-- ********** --> <!ELEMENT 成果ファイル情報 (測量成果ファイル名, 測量成果ファイル名副題?, XML スキーマファイル名*, コードリストファイル名*, メタデータファイル名?)> <!ELEMENT 測量成果ファイル名 (#PCDATA)> <!ELEMENT 測量成果ファイル名副題 (#PCDATA)> <!ELEMENT XML スキーマファイル名 (#PCDATA)> <!ELEMENT コードリストファイル名 (#PCDATA)> <!ELEMENT メタデータファイル名 (#PCDATA)> <!-- ********** --> <!-- その他 --> <!-- ********** --> <!ELEMENT その他 (受注者説明文?, 予備*)>		付 1-4 測量成果管理ファイル（基準点測量：SURV_KTN.XML、水準測量：SURV_SJN.XML、地形測量及び写真測量：SURV_CHI.XML、三次元点群測量：SURV_ SGT.XML、路線測量：SURV_RSN.XML、河川測量：SURV_KSN.XML、用地測量：SURV_YCH.XML、その他の応用測量：SURV_OYO.XML）の DTD（SURV_D03.DTD）は次による。 <!-- SURV_D03.DTD / 2008/12--> <!ELEMENT SURV_DATA (測量成果情報+, その他?, ソフトメーカ用 TAG*)> <!ATTLIST SURV_DATA DTD_version CDATA #FIXED "03"> <!-- ********** --> <!-- 測量成果情報 --> <!-- ********** --> <!ELEMENT 測量成果情報 (測量区分フォルダ名, 測量成果区分フォルダ名, 測量細区分フォルダ名?, 測量成果名称, 測量成果ファイル形式, 測量成果レコードフォーマット?, 測量成果作成ソフトウェア名?, 成果ファイル情報+)> <!ELEMENT 測量区分フォルダ名 (#PCDATA)> <!ELEMENT 測量成果区分フォルダ名 (#PCDATA)> <!ELEMENT 測量細区分フォルダ名 (#PCDATA)> <!ELEMENT 測量成果名称 (#PCDATA)> <!ELEMENT 測量成果ファイル形式 (#PCDATA)> <!ELEMENT 測量成果レコードフォーマット (#PCDATA)> <!ELEMENT 測量成果作成ソフトウェア名 (#PCDATA)> <!-- ********** --> <!-- 成果ファイル情報 --> <!-- ********** --> <!ELEMENT 成果ファイル情報 (測量成果ファイル名, 測量成果ファイル名副題?, XML スキーマファイル名*, コードリストファイル名*, メタデータファイル名?)> <!ELEMENT 測量成果ファイル名 (#PCDATA)> <!ELEMENT 測量成果ファイル名副題 (#PCDATA)> <!ELEMENT XML スキーマファイル名 (#PCDATA)> <!ELEMENT コードリストファイル名 (#PCDATA)> <!ELEMENT メタデータファイル名 (#PCDATA)> <!-- ********** --> <!-- その他 --> <!-- ********** --> <!ELEMENT その他 (受注者説明文?, 予備*)>

改定（令和７年 12 月）		現行（令和６年３月）
<!ELEMENT 受注者説明文 (#PCDATA)> <!ELEMENT 予備 (#PCDATA)> <!ELEMENT ソフトメーカ用 TAG (#PCDATA)>		<!ELEMENT 受注者説明文 (#PCDATA)> <!ELEMENT 予備 (#PCDATA)> <!ELEMENT ソフトメーカ用 TAG (#PCDATA)>

改定（令和７年 12 月）

付 1-5

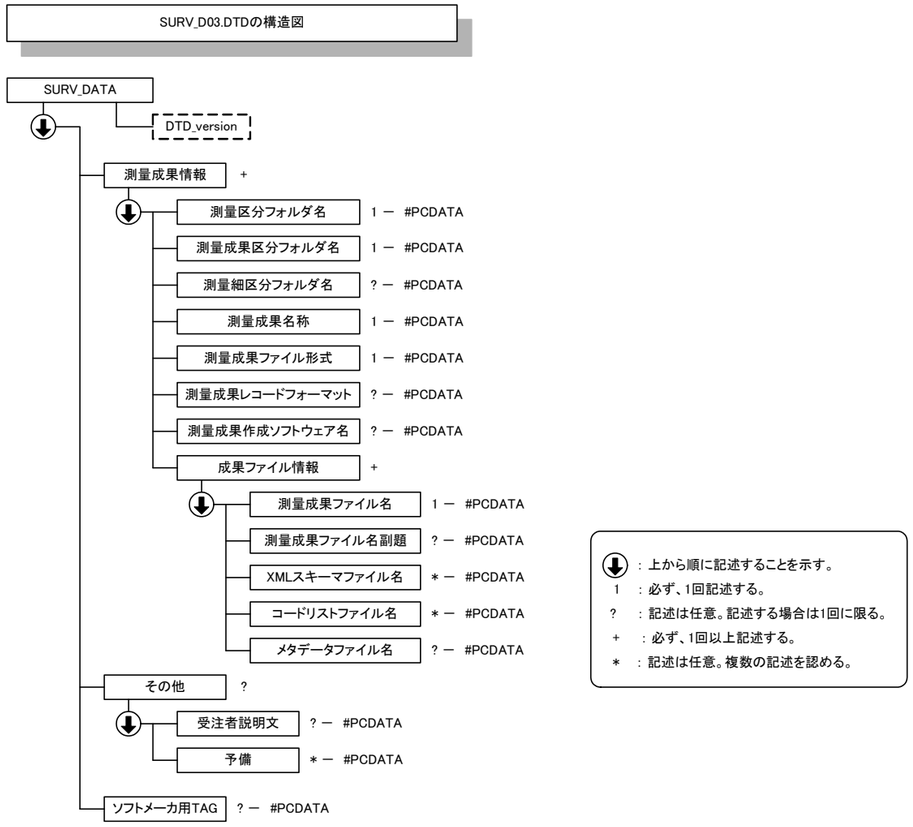

現行（令和６年３月）

付 1-5

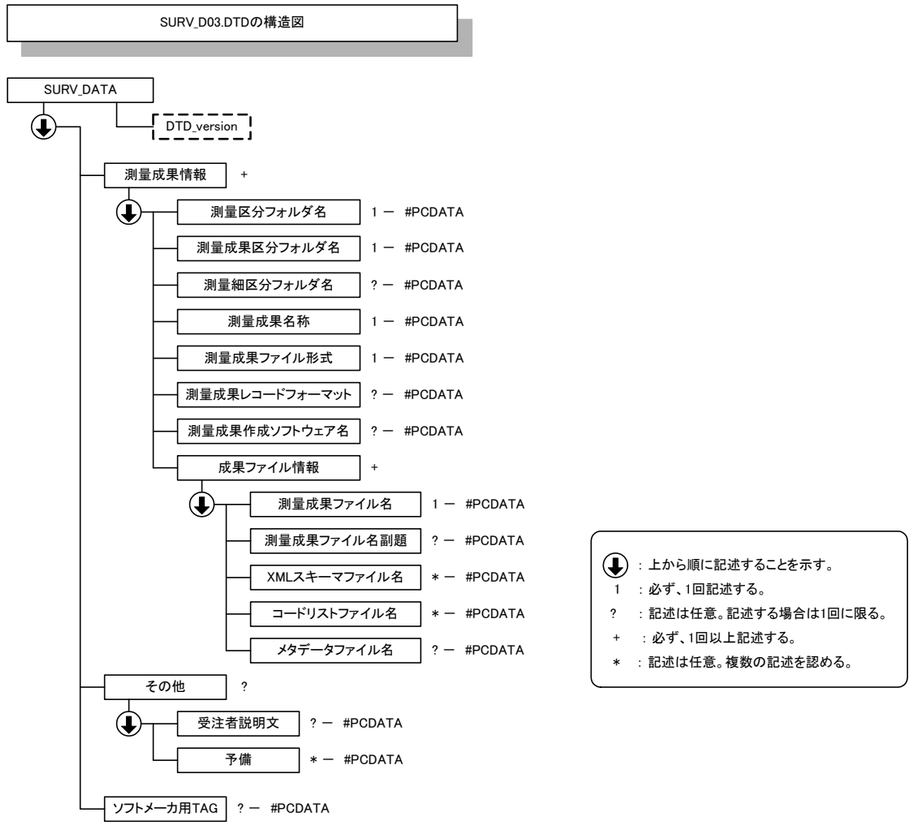

改定（令和７年 12 月）		現行（令和６年３月）
(3)　　ドキュメント管理ファイルの DTD		(3)　　ドキュメント管理ファイルの DTD
付 1-6 ドキュメント管理ファイル（SURV_DOC.XML）の DTD（SDOC_D01.DTD）は次による。 <!-- SDOC_D01.DTD / 2008/12--> <!ELEMENT SURV_DOC（ドキュメント情報+, その他?, ソフトメーカ用 TAG*)> <!ATTLIST SURV_DOC DTD_version CDATA #FIXED "01"> <!-- ********** --> <!-- ドキュメント情報 --> <!-- ********** --> <!ELEMENT ドキュメント情報（ドキュメント名称, ドキュメントファイル形式,ドキュメントファイル名,ドキュメントファイル名副題?,ドキュメント作成ソフトウェア名?)> <!ELEMENT ドキュメント名称（#PCDATA)> <!ELEMENT ドキュメントファイル形式（#PCDATA)> <!ELEMENT ドキュメントファイル名（#PCDATA)> <!ELEMENT ドキュメントファイル名副題（#PCDATA)> <!ELEMENT ドキュメント作成ソフトウェア名（#PCDATA)> <!-- ********** --> <!-- その他 --> <!-- ********** --> <!ELEMENT その他（受注者説明文?, 予備*)> <!ELEMENT 受注者説明文（#PCDATA)> <!ELEMENT 予備（#PCDATA)> <!ELEMENT ソフトメーカ用 TAG（#PCDATA)>	修正	付 1-6 ドキュメント管理ファイル（SURV_DOC.XML）の DTD（SDOC_D01.DTD）は次による。 <!-- SDOC_D01.DTD / 2008/12--> <!ELEMENT SURV_DOC（ドキュメント情報+, その他?, ソフトメーカ用 TAG*)> <!ATTLIST SURV_DOC DTD_version CDATA #FIXED "01"> <!-- ********** --> <!-- 測量成果情報 --> <!-- ********** --> <!ELEMENT ドキュメント情報（ドキュメント名称, ドキュメントファイル形式,ドキュメントファイル名,ドキュメントファイル名副題?,ドキュメント作成ソフトウェア名?)> <!ELEMENT ドキュメント名称（#PCDATA)> <!ELEMENT ドキュメントファイル形式（#PCDATA)> <!ELEMENT ドキュメントファイル名（#PCDATA)> <!ELEMENT ドキュメントファイル名副題（#PCDATA)> <!ELEMENT ドキュメント作成ソフトウェア名（#PCDATA)> <!-- ********** --> <!-- その他 --> <!-- ********** --> <!ELEMENT その他（受注者説明文?, 予備*)> <!ELEMENT 受注者説明文（#PCDATA)> <!ELEMENT 予備（#PCDATA)> <!ELEMENT ソフトメーカ用 TAG（#PCDATA)>

改定（令和７年 12 月）		現行（令和６年３月）
付 1-7		付 1-7

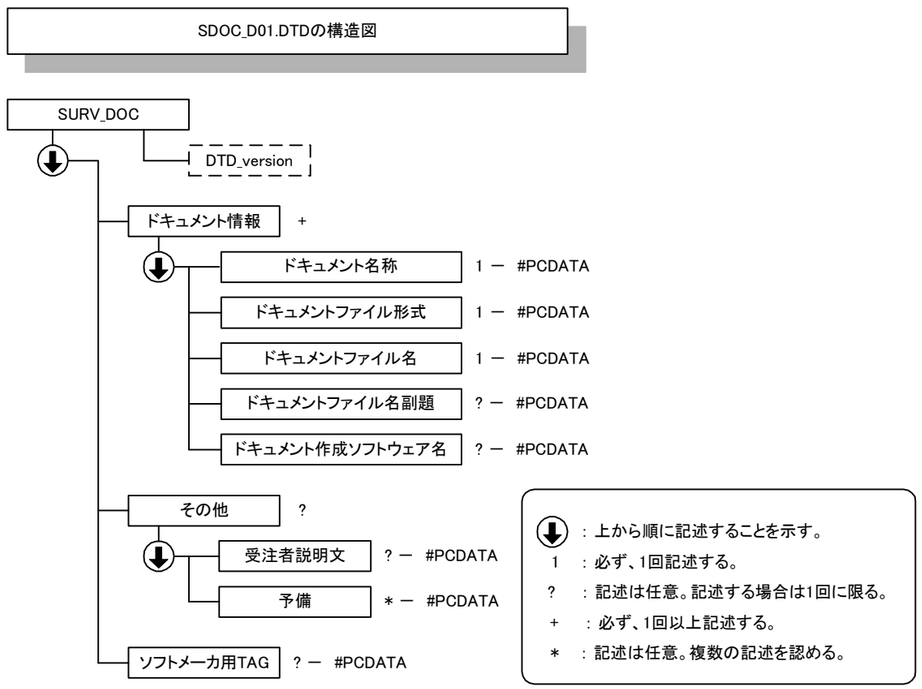

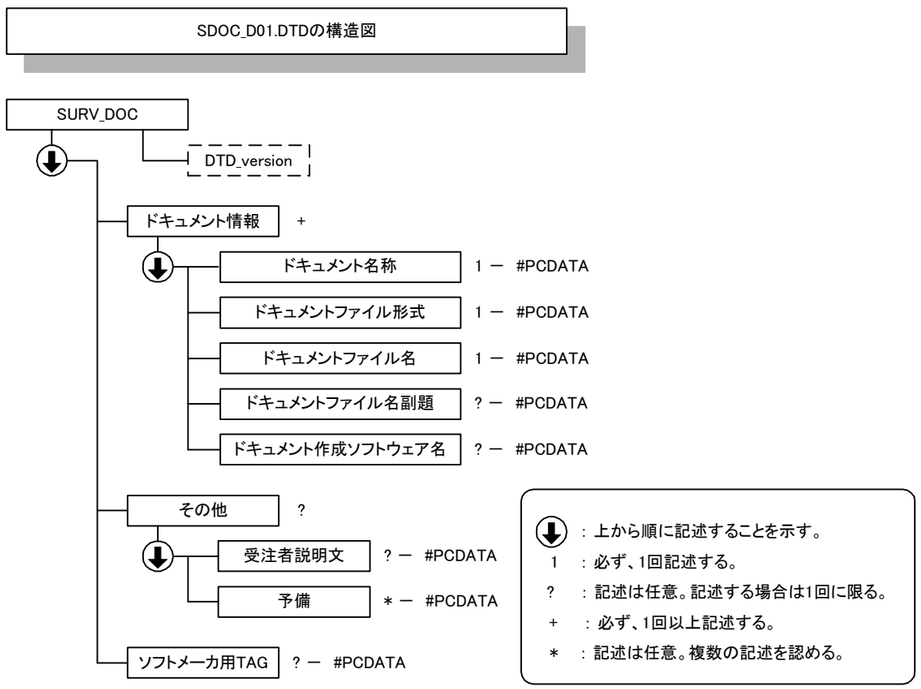

改定（令和７年 12 月）		現行（令和６年３月）
付属資料 2　管理ファイルの XML 記入例		**付属資料 2　管理ファイルの XML 記入例**
（1）　測量情報管理ファイルの XML 記入例		（1）　測量情報管理ファイルの XML 記入例
付 2-1 <?xml version="1.0" encoding="Shift_JIS"?> <!DOCTYPE SURVEY SYSTEM "SURVEY05.DTD"> <SURVEY DTD_version="05"> <基礎情報> <適用要領基準>土木 202503-01</適用要領基準> <助言番号>R02C0052</助言番号> <作業規程名>国土交通省公共測量作業規程（平成 20 年国土交通省告示版）</作業規程名> <製品仕様書> <製品仕様書名>地図情報レベル 2500 データ作成の製品仕様書(案)</製品仕様書名> <製品仕様書ファイル名>SPECP001.PDF</製品仕様書ファイル名> </製品仕様書> <製品仕様書> <製品仕様書名>空間データ作成のための製品仕様書作成の手引き(案)</製品仕様書名> <製品仕様書ファイル名> SPECP002.PDF </製品仕様書ファイル名> </製品仕様書> <第三者機関成果検定の有無>1</第三者機関成果検定の有無> <基準点測量成果格納用フォルダ名>KITEN</基準点測量成果格納用フォルダ名> <水準測量成果格納用フォルダ名>SUIJUN</水準測量成果格納用フォルダ名> <地形測量及び写真測量成果格納用フォルダ名>CHIKEI</地形測量及び写真測量成果格納用フォルダ名> <三次元点群測量成果格納用フォルダ名>SGTN</三次元点群測量成果格納用フォルダ名> <路線測量成果格納用フォルダ名>ROSEN</路線測量成果格納用フォルダ名> <河川測量成果格納用フォルダ名>KASEN</河川測量成果格納用フォルダ名> <用地測量成果格納用フォルダ名>YOUCHI</用地測量成果格納用フォルダ名> <その他の応用測量成果格納用フォルダ名>OTHRSOYO</その他の応用測量成果格納用フォルダ名> <ドキュメント格納用フォルダ名>DOC</ドキュメント格納用フォルダ名> </基礎情報> <場所情報> <測量区域番号>1</測量区域番号> <測量区域名>〇〇〇〇地区</測量区域名> <区域情報>	変更 変更 変更	付 2-1 <?xml version="1.0" encoding="Shift_JIS"?> <!DOCTYPE SURVEY SYSTEM "SURVEY04.DTD"> <SURVEY DTD_version="04"> <基礎情報> <適用要領基準>土木 202003-01</適用要領基準> <助言番号>R02C0052</助言番号> <作業規程名>国土交通省公共測量作業規程（平成 20 年国土交通省告示版）</作業規程名> <製品仕様書> <製品仕様書名>地図情報レベル 2500 データ作成の製品仕様書(案)</製品仕様書名> <製品仕様書ファイル名>SPECP001.PDF</製品仕様書ファイル名> </製品仕様書> <製品仕様書> <製品仕様書名>空間データ作成のための製品仕様書作成の手引き(案)</製品仕様書名> <製品仕様書ファイル名> SPECP002.PDF </製品仕様書ファイル名> </製品仕様書> <第三者機関成果検定の有無>1</第三者機関成果検定の有無> <基準点測量成果格納用フォルダ名>KITEN</基準点測量成果格納用フォルダ名> <水準測量成果格納用フォルダ名>SUIJUN</水準測量成果格納用フォルダ名> <地形測量及び写真測量成果格納用フォルダ名>CHIKEI</地形測量及び写真測量成果格納用フォルダ名> <三次元点群測量成果格納用フォルダ名>SGTN</三次元点群測量成果格納用フォルダ名> <路線測量成果格納用フォルダ名>ROSEN</路線測量成果格納用フォルダ名> <河川測量成果格納用フォルダ名>KASEN</河川測量成果格納用フォルダ名> <用地測量成果格納用フォルダ名>YOUCHI</用地測量成果格納用フォルダ名> <その他の応用測量成果格納用フォルダ名>OTHRSOYO</その他の応用測量成果格納用フォルダ名> <ドキュメント格納用フォルダ名>DOC</ドキュメント格納用フォルダ名> </基礎情報> <場所情報> <測量区域番号>1</測量区域番号> <測量区域名>〇〇〇〇地区</測量区域名> <区域情報>

改定（令和７年 12 月）		現行（令和６年３月）
<平面直角座標系>9</平面直角座標系>		<平面直角座標系>9</平面直角座標系>
<西側境界平面直角座標>-60000.00</西側境界平面直角座標>		<西側境界平面直角座標>-60000.00</西側境界平面直角座標>
<東側境界平面直角座標>-40000.00</東側境界平面直角座標>		<東側境界平面直角座標>-40000.00</東側境界平面直角座標>
<北側境界平面直角座標>-28500.00</北側境界平面直角座標>		<北側境界平面直角座標>-28500.00</北側境界平面直角座標>
<南側境界平面直角座標>-39000.00</南側境界平面直角座標>		<南側境界平面直角座標>-39000.00</南側境界平面直角座標>
</区域情報>		</区域情報>
</場所情報>		</場所情報>
<場所情報>		<場所情報>
<測量区域番号>2</測量区域番号>		<測量区域番号>2</測量区域番号>
<測量区域名>●●●●地区</測量区域名>		<測量区域名>●●●●地区</測量区域名>
<区域情報>		<区域情報>
<平面直角座標系>9</平面直角座標系>		<平面直角座標系>9</平面直角座標系>
<西側境界平面直角座標>-40000.00</西側境界平面直角座標>		<西側境界平面直角座標>-40000.00</西側境界平面直角座標>
<東側境界平面直角座標>-20000.00</東側境界平面直角座標>		<東側境界平面直角座標>-20000.00</東側境界平面直角座標>
<北側境界平面直角座標>-28500.00</北側境界平面直角座標>		<北側境界平面直角座標>-28500.00</北側境界平面直角座標>
<南側境界平面直角座標>-39000.00</南側境界平面直角座標>		<南側境界平面直角座標>-39000.00</南側境界平面直角座標>
</区域情報>		</区域情報>
</場所情報>		付 2-2
		</場所情報>
付 2-2		
<測量情報>		<測量情報>
<測量区分>基準点測量</測量区分>		<測量区分>基準点測量</測量区分>
<測量細区分>基準点測量 A</測量細区分>		<測量細区分>基準点測量 A</測量細区分>
<測量記録フォルダパス名>SURVEY/KITEN/WORK/KTN_A</測量記録フォルダパス名>		<測量記録フォルダパス名>SURVEY/KITEN/WORK/KTN_A</測量記録フォルダパス名>
<測量成果フォルダパス名>SURVEY/KITEN/DATA/KTN_A</測量成果フォルダパス名>		<測量成果フォルダパス名>SURVEY/KITEN/DATA/KTN_A</測量成果フォルダパス名>
<その他データフォルダパス名>SURVEY/KITEN/OTHRS</その他データフォルダパス名>		<その他データフォルダパス名>SURVEY/KITEN/OTHRS</その他データフォルダパス名>
<測量区域 No>1</測量区域 No>		<測量区域 No>1</測量区域 No>
<等級精度>		<等級精度>
<等級>22</等級>		<等級>22</等級>
<地図情報レベル/>	変更	<地図情報レベル></地図情報レベル>
</等級精度>		</等級精度>
<画像種別/>	変更	<画像種別></画像種別>
<解像度/>	変更	<解像度></解像度>
<新規修正区分>1</新規修正区分>		<新規修正区分>1</新規修正区分>
<面積>25.0</面積>		<面積>25.0</面積>
<距離/>	変更	<距離></距離>
<点数>12</点数>		<点数>12</点数>
<モデル数/>	変更	<モデル数></モデル数>

改定（令和７年 12 月）		現行（令和６年３月）
<点密度/>	追加	
</測量情報>		</測量情報>
<測量情報>		<測量情報>
<測量区分>基準点測量</測量区分>		<測量区分>基準点測量</測量区分>
<測量細区分>基準点測量 B</測量細区分>		<測量細区分>基準点測量 B</測量細区分>
<測量記録フォルダパス名>SURVEY/KITEN/WORK/KTN_B</測量記録フォルダパス名>		<測量記録フォルダパス名>SURVEY/KITEN/WORK/KTN_B</測量記録フォルダパス名>
<測量成果フォルダパス名>SURVEY/KITEN/DATA/KTN_B</測量成果フォルダパス名>		<測量成果フォルダパス名>SURVEY/KITEN/DATA/KTN_B</測量成果フォルダパス名>
<その他データフォルダパス名>SURVEY/KITEN/OTHRS</その他データフォルダパス名>		<その他データフォルダパス名>SURVEY/KITEN/OTHRS</その他データフォルダパス名>
<測量区域 No>2</測量区域 No>		<測量区域 No>2</測量区域 No>
<等級精度>		<等級精度>
<等級>23</等級>		<等級>23</等級>
<地図情報レベル/>	変更	<地図情報レベル></地図情報レベル>
</等級精度>		</等級精度>
<画像種別/>	変更	<画像種別></画像種別>
<解像度/>	変更	<解像度></解像度>
<新規修正区分>1</新規修正区分>		<新規修正区分>1</新規修正区分>
<面積>50.3</面積>		<面積>50.3</面積>
<距離/>	変更	<距離></距離>
<点数>24</点数>		<点数>24</点数>
<モデル数/>	変更	<モデル数></モデル数>
<点密度/>	追加	
</測量情報>		</測量情報>
<測量情報>		<測量情報>
<測量区分>水準測量</測量区分>		<測量区分>水準測量</測量区分>
<測量細区分>水準測量</測量細区分>		<測量細区分>水準測量</測量細区分>
<測量記録フォルダパス名>SURVEY/SUIJUN/WORK/SJN_A</測量記録フォルダパス名>		<測量記録フォルダパス名>SURVEY/SUIJUN/WORK/SJN_A</測量記録フォルダパス名>
<測量成果フォルダパス名>SURVEY/SUIJUN/DATA/SJN_A</測量成果フォルダパス名>		<測量成果フォルダパス名>SURVEY/SUIJUN/DATA/SJN_A</測量成果フォルダパス名>
<その他データフォルダパス名>SURVEY/SUIJUN/OTHRS</その他データフォルダパス名>		<その他データフォルダパス名>SURVEY/SUIJUN/OTHRS</その他データフォルダパス名>
<測量区域 No>1</測量区域 No>		<測量区域 No>1</測量区域 No>
<等級精度>		<等級精度>
<等級>22</等級>		<等級>22</等級>
<地図情報レベル/>	変更	<地図情報レベル></地図情報レベル>
</等級精度>		</等級精度>
<画像種別/>	変更	<画像種別></画像種別>
<解像度/>	変更	<解像度></解像度>
		付 2-3
<新規修正区分>1</新規修正区分>		<新規修正区分>1</新規修正区分>

改定（令和７年 12 月）		現行（令和６年３月）
<面積>25.0</面積>		<面積>25.0</面積>
<距離/>	変更	<距離></距離>
付 2-3		
<点数/>	変更	<点数></点数>
<モデル数/>	変更	<モデル数></モデル数>
<点密度/>	追加	
</測量情報>		</測量情報>
<測量情報>		<測量情報>
<測量区分>地形測量及び写真測量</測量区分>		<測量区分>地形測量及び写真測量</測量区分>
<測量細区分>撮影</測量細区分>		<測量細区分>撮影</測量細区分>
<測量記録フォルダパス名>SURVEY/CHIKEI/WORK/SATU_A</測量記録フォルダパス名>		<測量記録フォルダパス名>SURVEY/CHIKEI/WORK/SATU_A</測量記録フォルダパス名>
<その他データフォルダパス名>SURVEY/CHIKEI/OTHRS</その他データフォルダパス名>		<その他データフォルダパス名>SURVEY/CHIKEI/OTHRS</その他データフォルダパス名>
<測量区域 No>2</測量区域 No>		<測量区域 No>2</測量区域 No>
<等級精度>		<等級精度>
<等級/>	変更	<等級></等級>
<地図情報レベル>2500</地図情報レベル>		<地図情報レベル>2500</地図情報レベル>
</等級精度>		</等級精度>
<画像種別>1</画像種別>		<画像種別>1</画像種別>
<解像度/>	変更	<解像度></解像度>
<新規修正区分>1</新規修正区分>		<新規修正区分>1</新規修正区分>
<面積>50.3</面積>		<面積>50.3</面積>
<距離/>	変更	<距離></距離>
<点数/>	変更	<点数></点数>
<モデル数/>	変更	<モデル数></モデル数>
<点密度/>	追加	
</測量情報>		</測量情報>
<測量情報>		<測量情報>
<測量区分>地形測量及び写真測量</測量区分>		<測量区分>地形測量及び写真測量</測量区分>
<測量細区分>同時調整</測量細区分>		<測量細区分>同時調整</測量細区分>
<測量記録フォルダパス名>SURVEY/CHIKEI/WORK/KUSAN_A</測量記録フォルダパス名>		<測量記録フォルダパス名>SURVEY/CHIKEI/WORK/KUSAN_A</測量記録フォルダパス名>
<その他データフォルダパス名>SURVEY/CHIKEI/OTHRS</その他データフォルダパス名>		<その他データフォルダパス名>SURVEY/CHIKEI/OTHRS</その他データフォルダパス名>
<測量区域 No>2</測量区域 No>		<測量区域 No>2</測量区域 No>
<等級精度>		<等級精度>
<等級/>	変更	<等級></等級>
<地図情報レベル>2500</地図情報レベル>		<地図情報レベル>2500</地図情報レベル>
</等級精度>		</等級精度>
<画像種別>1</画像種別>		<画像種別>1</画像種別>

改定（令和７年 12 月）		現行（令和６年３月）
<解像度/>	変更	<解像度></解像度>
<新規修正区分>1</新規修正区分>		<新規修正区分>1</新規修正区分>
<面積>50.3</面積>		<面積>50.3</面積>
<距離/>	変更	<距離></距離>
<点数/>	変更	<点数></点数>
<モデル数>3</モデル数>		<モデル数>3</モデル数>
<点密度/>	追加	
</測量情報>		</測量情報>
<測量情報>		<測量情報>
<測量区分>地形測量及び写真測量</測量区分>		<測量区分>地形測量及び写真測量</測量区分>
<測量細区分>数値図化</測量細区分>		<測量細区分>数値図化</測量細区分>
<測量記録フォルダパス名>SURVEY/CHIKEI/WORK/ZUKA_A</測量記録フォルダパス名>		<測量記録フォルダパス名>SURVEY/CHIKEI/WORK/ZUKA_A</測量記録フォルダパス名>
<測量成果フォルダパス名>SURVEY/CHIKEI/DATA</測量成果フォルダパス名>		<測量成果フォルダパス名>SURVEY/CHIKEI/DATA</測量成果フォルダパス名>
<その他データフォルダパス名>SURVEY/CHIKEI/OTHRS</その他データフォルダパス名>		<その他データフォルダパス名>SURVEY/CHIKEI/OTHRS</その他データフォルダパス名>
<測量区域 No>2</測量区域 No>		<測量区域 No>2</測量区域 No>
<等級精度>		<等級精度>
<等級/>	変更	<等級></等級>
<地図情報レベル>2500</地図情報レベル>		<地図情報レベル>2500</地図情報レベル>
		付 2-4
</等級精度>		</等級精度>
<画像種別>1</画像種別>		<画像種別>1</画像種別>
<解像度/>	変更	<解像度></解像度>
付 2-4		
<新規修正区分>1</新規修正区分>		<新規修正区分>1</新規修正区分>
<面積>50.3</面積>		<面積>50.3</面積>
<距離/>	変更	<距離></距離>
<点数/>	変更	<点数></点数>
<モデル数/>	変更	<モデル数></モデル数>
<点密度/>	追加	
</測量情報>		</測量情報>
<測量情報>		<測量情報>
<測量区分>地形測量及び写真測量</測量区分>		<測量区分>地形測量及び写真測量</測量区分>
<測量細区分>地図編集</測量細区分>		<測量細区分>地図編集</測量細区分>
<測量記録フォルダパス名>SURVEY/CHIKEI/WORK/ZUHEN_A</測量記録フォルダパス名>		<測量記録フォルダパス名>SURVEY/CHIKEI/WORK/ZUHEN_A</測量記録フォルダパス名>
<測量成果フォルダパス名>SURVEY/CHIKEI/DATA</測量成果フォルダパス名>		<測量成果フォルダパス名>SURVEY/CHIKEI/DATA</測量成果フォルダパス名>
<その他データフォルダパス名>SURVEY/CHIKEI/OTHRS</その他データフォルダパス名>		<その他データフォルダパス名>SURVEY/CHIKEI/OTHRS</その他データフォルダパス名>
<測量区域 No>2</測量区域 No>		<測量区域 No>2</測量区域 No>

改定（令和７年 12 月）		現行（令和６年３月）
<等級精度>		<等級精度>
<等級/>	変更	<等級></等級>
<地図情報レベル>2500</地図情報レベル>		<地図情報レベル>2500</地図情報レベル>
</等級精度>		</等級精度>
<画像種別>1</画像種別>		<画像種別>1</画像種別>
<解像度/>	変更	<解像度></解像度>
<新規修正区分>1</新規修正区分>		<新規修正区分>1</新規修正区分>
<面積>50.3</面積>		<面積>50.3</面積>
<距離/>	変更	<距離></距離>
<点数/>	変更	<点数></点数>
<モデル数/>	変更	<モデル数></モデル数>
<点密度/>	追加	
</測量情報>		</測量情報>
<検定情報>		<検定情報>
<測量成果検定証明書等のファイル名>SURVEY/KITEN/OTHRS/KOTJ2001.PDF</測量成果検定証明書等のファイル名>		<測量成果検定証明書等のファイル名>SURVEY/KITEN/OTHRS/KOTJ2001.PDF</測量成果検定証明書等のファイル名>
<測量成果検定証明書等のファイル名>SURVEY/KITEN/OTHRS/KOTJ2002.PDF</測量成果検定証明書等のファイル名>		<測量成果検定証明書等のファイル名>SURVEY/KITEN/OTHRS/KOTJ2002.PDF</測量成果検定証明書等のファイル名>
<測量成果検定証明書等のファイル名>SURVEY/SUIJUN/OTHRS/SOTJ2001.PDF</測量成果検定証明書等のファイル名>		<測量成果検定証明書等のファイル名>SURVEY/SUIJUN/OTHRS/SOTJ2001.PDF</測量成果検定証明書等のファイル名>
<測量成果検定証明書等のファイル名>SURVEY/CHIKEI/OTHRS/ZOTJ2001.PDF</測量成果検定証明書等のファイル名>		<測量成果検定証明書等のファイル名>SURVEY/CHIKEI/OTHRS/ZOTJ2001.PDF</測量成果検定証明書等のファイル名>
</検定情報>		</検定情報>
<その他>		<その他>
<受注者説明文/>	変更	<受注者説明文></受注者説明文>
<予備/>	変更	<予備></予備>
</その他>		</その他>
<ソフトメーカ用 TAG/>	変更	<ソフトメーカ用 TAG></ソフトメーカ用 TAG>
</SURVEY>		</SURVEY>

改定（令和７年 12 月）		現行（令和６年３月）
(2)　測量成果管理ファイルの XML 記入例		(2)　測量成果管理ファイルの XML 記入例
付 2-5 <?xml version="1.0" encoding="Shift_JIS"?> <!DOCTYPE SURV_DATA SYSTEM "SURV_D03.DTD"> <SURV_DATA DTD_version="03"> <測量成果情報> <測量区分フォルダ名>KITEN</測量区分フォルダ名> <測量成果区分フォルダ名>WORK</測量成果区分フォルダ名> <測量細区分フォルダ名>KTN_A</測量細区分フォルダ名> <測量成果名称>観測手簿</測量成果名称> <測量成果ファイル形式>PDF</測量成果ファイル形式> <測量成果作成ソフトウェア名>ADOBE ACROBAT 7.0</測量成果作成ソフトウェア名> <成果ファイル情報> <測量成果ファイル名>KJAD1001.PDF</測量成果ファイル名> </成果ファイル情報> </測量成果情報> <測量成果情報> <測量区分フォルダ名>KITEN</測量区分フォルダ名> <測量成果区分フォルダ名>WORK</測量成果区分フォルダ名> <測量細区分フォルダ名>KTN_A</測量細区分フォルダ名> <測量成果名称>観測手簿(数値データ)</測量成果名称> <測量成果ファイル形式>TXT</測量成果ファイル形式> <測量成果レコードフォーマット>カンマ区切りの TXT 形式</測量成果レコードフォーマット> <測量成果作成ソフトウェア名>Microsoft ワードパット 1909</測量成果作成ソフトウェア名> <成果ファイル情報> <測量成果ファイル名>KJAD2001.TXT</測量成果ファイル名> <測量成果ファイル名副題>〇〇地区観測手簿数値データ.TXT</測量成果ファイル名副題> </成果ファイル情報> </測量成果情報> <測量成果情報> <測量区分フォルダ名>KITEN</測量区分フォルダ名> <測量成果区分フォルダ名>WORK</測量成果区分フォルダ名> <測量細区分フォルダ名>KTN_A</測量細区分フォルダ名> <測量成果名称>観測記簿</測量成果名称> <測量成果ファイル形式>PDF</測量成果ファイル形式>		付 2-5 <?xml version="1.0" encoding="Shift_JIS"?> <!DOCTYPE SURV_DATA SYSTEM "SURV_D03.DTD"> <SURV_DATA DTD_version="03"> <測量成果情報> <測量区分フォルダ名>KITEN</測量区分フォルダ名> <測量成果区分フォルダ名>WORK</測量成果区分フォルダ名> <測量細区分フォルダ名>KTN_A</測量細区分フォルダ名> <測量成果名称>観測手簿</測量成果名称> <測量成果ファイル形式>PDF</測量成果ファイル形式> <測量成果作成ソフトウェア名>ADOBE ACROBAT 7.0</測量成果作成ソフトウェア名> <成果ファイル情報> <測量成果ファイル名>KJAD1001.PDF</測量成果ファイル名> </成果ファイル情報> </測量成果情報> <測量成果情報> <測量区分フォルダ名>KITEN</測量区分フォルダ名> <測量成果区分フォルダ名>WORK</測量成果区分フォルダ名> <測量細区分フォルダ名>KTN_A</測量細区分フォルダ名> <測量成果名称>観測手簿(数値データ)</測量成果名称> <測量成果ファイル形式>TXT</測量成果ファイル形式> <測量成果レコードフォーマット>カンマ区切りの TXT 形式</測量成果レコードフォーマット> <測量成果作成ソフトウェア名>Microsoft ワードパット 1909</測量成果作成ソフトウェア名> <成果ファイル情報> <測量成果ファイル名>KJAD2001.TXT</測量成果ファイル名> <測量成果ファイル名副題>〇〇地区観測手簿数値データ.TXT</測量成果ファイル名副題> </成果ファイル情報> </測量成果情報> <測量成果情報> <測量区分フォルダ名>KITEN</測量区分フォルダ名> <測量成果区分フォルダ名>WORK</測量成果区分フォルダ名> <測量細区分フォルダ名>KTN_A</測量細区分フォルダ名> <測量成果名称>観測記簿</測量成果名称> <測量成果ファイル形式>PDF</測量成果ファイル形式>

改定（令和７年 12 月）		現行（令和６年３月）
<測量成果作成ソフトウェア名>ADOBE ACROBAT 7.0</測量成果作成ソフトウェア名> <成果ファイル情報> <測量成果ファイル名>KJAD3001.PDF</測量成果ファイル名> <測量成果ファイル名副題>〇〇地区観測記簿.PDF</測量成果ファイル名副題> </成果ファイル情報> </測量成果情報> <測量成果情報> <測量区分フォルダ名>KITEN</測量区分フォルダ名> <測量成果区分フォルダ名>WORK</測量成果区分フォルダ名> <測量細区分フォルダ名>KTN_A</測量細区分フォルダ名> <測量成果名称>精度管理表</測量成果名称> <測量成果ファイル形式>PDF</測量成果ファイル形式> <測量成果作成ソフトウェア名>ADOBE ACROBAT 7.0</測量成果作成ソフトウェア名> <成果ファイル情報> <測量成果ファイル名>KJAG1001.PDF</測量成果ファイル名> </成果ファイル情報> </測量成果情報> <測量成果情報> 付 2-6 <測量区分フォルダ名>KITEN</測量区分フォルダ名> <測量成果区分フォルダ名>DATA</測量成果区分フォルダ名> <測量細区分フォルダ名>KTN_A</測量細区分フォルダ名> <測量成果名称>成果表</測量成果名称> <測量成果ファイル形式>PDF</測量成果ファイル形式> <測量成果作成ソフトウェア名>ADOBE ACROBAT 7.0</測量成果作成ソフトウェア名> <成果ファイル情報> <測量成果ファイル名>KJAA1001.PDF</測量成果ファイル名> <測量成果ファイル名副題>1 級基準点 No.201.PDF</測量成果ファイル名副題> </成果ファイル情報> <成果ファイル情報> <測量成果ファイル名>KJAA1002.PDF</測量成果ファイル名> <測量成果ファイル名副題>1 級基準点 No.202.PDF </測量成果ファイル名副題> </成果ファイル情報> <成果ファイル情報> <測量成果ファイル名>KJAA1003.PDF</測量成果ファイル名> <測量成果ファイル名副題>1 級基準点 No.203.PDF </測量成果ファイル名副題>		<測量成果作成ソフトウェア名>ADOBE ACROBAT 7.0</測量成果作成ソフトウェア名> <成果ファイル情報> <測量成果ファイル名>KJAD3001.PDF</測量成果ファイル名> <測量成果ファイル名副題>〇〇地区観測記簿.PDF</測量成果ファイル名副題> </成果ファイル情報> </測量成果情報> <測量成果情報> <測量区分フォルダ名>KITEN</測量区分フォルダ名> <測量成果区分フォルダ名>WORK</測量成果区分フォルダ名> <測量細区分フォルダ名>KTN_A</測量細区分フォルダ名> <測量成果名称>精度管理表</測量成果名称> <測量成果ファイル形式>PDF</測量成果ファイル形式> <測量成果作成ソフトウェア名>ADOBE ACROBAT 7.0</測量成果作成ソフトウェア名> <成果ファイル情報> <測量成果ファイル名>KJAG1001.PDF</測量成果ファイル名> </成果ファイル情報> </測量成果情報> <測量成果情報> 付 2-6 <測量区分フォルダ名>KITEN</測量区分フォルダ名> <測量成果区分フォルダ名>DATA</測量成果区分フォルダ名> <測量細区分フォルダ名>KTN_A</測量細区分フォルダ名> <測量成果名称>成果表</測量成果名称> <測量成果ファイル形式>PDF</測量成果ファイル形式> <測量成果作成ソフトウェア名>ADOBE ACROBAT 7.0</測量成果作成ソフトウェア名> <成果ファイル情報> <測量成果ファイル名>KJAA1001.PDF</測量成果ファイル名> <測量成果ファイル名副題>1 級基準点 No.201.PDF</測量成果ファイル名副題> </成果ファイル情報> <成果ファイル情報> <測量成果ファイル名>KJAA1002.PDF</測量成果ファイル名> <測量成果ファイル名副題>1 級基準点 No.202.PDF </測量成果ファイル名副題> </成果ファイル情報> <成果ファイル情報> <測量成果ファイル名>KJAA1003.PDF</測量成果ファイル名> <測量成果ファイル名副題>1 級基準点 No.203.PDF </測量成果ファイル名副題>

改定（令和７年 12 月）		現行（令和６年３月）
</成果ファイル情報>		</成果ファイル情報>
<成果ファイル情報>		<成果ファイル情報>
<測量成果ファイル名>KJAA1004.PDF</測量成果ファイル名>		<測量成果ファイル名>KJAA1004.PDF</測量成果ファイル名>
<測量成果ファイル名副題>1 級基準点 No.204.PDF </測量成果ファイル名副題>		<測量成果ファイル名副題>1 級基準点 No.204.PDF </測量成果ファイル名副題>
</成果ファイル情報>		</成果ファイル情報>
</測量成果情報>		</測量成果情報>
<測量成果情報>		<測量成果情報>
<測量区分フォルダ名>KITEN</測量区分フォルダ名>		<測量区分フォルダ名>KITEN</測量区分フォルダ名>
<測量成果区分フォルダ名>DATA</測量成果区分フォルダ名>		<測量成果区分フォルダ名>DATA</測量成果区分フォルダ名>
<測量細区分フォルダ名>KTN_A</測量細区分フォルダ名>		<測量細区分フォルダ名>KTN_A</測量細区分フォルダ名>
<測量成果名称>成果表数値データ</測量成果名称>		<測量成果名称>成果表数値データ</測量成果名称>
<測量成果ファイル形式>XML</測量成果ファイル形式>		<測量成果ファイル形式>XML</測量成果ファイル形式>
<測量成果レコードフォーマット>JPGIS 準拠形式</測量成果レコードフォーマット>		<測量成果レコードフォーマット>JPGIS 準拠形式</測量成果レコードフォーマット>
<測量成果作成ソフトウェア名>〇〇測量計算ソフト 1.0</測量成果作成ソフトウェア名>		<測量成果作成ソフトウェア名>〇〇測量計算ソフト 1.0</測量成果作成ソフトウェア名>
<成果ファイル情報>		<成果ファイル情報>
<測量成果ファイル名>KJAA2001.XML</測量成果ファイル名>		<測量成果ファイル名>KJAA2001.XML</測量成果ファイル名>
<測量成果ファイル名副題>1 級基準点成果表数値データ.XML </測量成果ファイル名副題>		<測量成果ファイル名副題>1 級基準点成果表数値データ.XML </測量成果ファイル名副題>
<XML スキーマファイル名>SCHM001.XSD</XML スキーマファイル名>		<XML スキーマファイル名>SCHM001.XSD</XML スキーマファイル名>
<コードリストファイル名>CODE001.XML</コードリストファイル名>		<コードリストファイル名>CODE001.XML</コードリストファイル名>
<コードリストファイル名>CODE002.XML</コードリストファイル名>		<コードリストファイル名>CODE002.XML</コードリストファイル名>
<メタデータファイル名>KJAA4001.XML</メタデータファイル名>		<メタデータファイル名>KJAA4001.XML</メタデータファイル名>
</成果ファイル情報>		</成果ファイル情報>
</測量成果情報>		</測量成果情報>
<測量成果情報>		<測量成果情報>
<測量区分フォルダ名>KITEN</測量区分フォルダ名>		<測量区分フォルダ名>KITEN</測量区分フォルダ名>
<測量成果区分フォルダ名>DATA</測量成果区分フォルダ名>		<測量成果区分フォルダ名>DATA</測量成果区分フォルダ名>
<測量細区分フォルダ名>KTN_A</測量細区分フォルダ名>		<測量細区分フォルダ名>KTN_A</測量細区分フォルダ名>
<測量成果名称>品質評価表</測量成果名称>		<測量成果名称>品質評価表</測量成果名称>
<測量成果ファイル形式>PDF</測量成果ファイル形式>		<測量成果ファイル形式>PDF</測量成果ファイル形式>
<測量成果作成ソフトウェア名>ADOBE ACROBAT 7.0</測量成果作成ソフトウェア名>		<測量成果作成ソフトウェア名>ADOBE ACROBAT 7.0</測量成果作成ソフトウェア名>
<成果ファイル情報>		<成果ファイル情報>
<測量成果ファイル名>KJAA3001.PDF</測量成果ファイル名>		<測量成果ファイル名>KJAA3001.PDF</測量成果ファイル名>
</成果ファイル情報>		</成果ファイル情報>
</測量成果情報>		</測量成果情報>
<測量成果情報>		<測量成果情報>
<測量区分フォルダ名>KITEN</測量区分フォルダ名>		<測量区分フォルダ名>KITEN</測量区分フォルダ名>

改定（令和７年 12 月）		現行（令和６年３月）
<測量成果区分フォルダ名>DATA</測量成果区分フォルダ名> <測量細区分フォルダ名>KTN_A</測量細区分フォルダ名> 付 2-7 <測量成果名称>メタデータ</測量成果名称> <測量成果ファイル形式>XML</測量成果ファイル形式> <測量成果レコードフォーマット>JMP2.0 形式</測量成果レコードフォーマット> <測量成果作成ソフトウェア名>メタデータエディター1.0</測量成果作成ソフトウェア名> <成果ファイル情報> <測量成果ファイル名>KJAA4001.XML</測量成果ファイル名> <測量成果ファイル名副題>KS-META-N02-07.XML</測量成果ファイル名副題> </成果ファイル情報> </測量成果情報> <測量成果情報> <測量区分フォルダ名>KITEN</測量区分フォルダ名> <測量成果区分フォルダ名>DATA</測量成果区分フォルダ名> <測量細区分フォルダ名>KTN_A</測量細区分フォルダ名> <測量成果名称>XML スキーマ</測量成果名称> <測量成果ファイル形式>XSD</測量成果ファイル形式> <測量成果レコードフォーマット>XSD 形式</測量成果レコードフォーマット> <成果ファイル情報> <測量成果ファイル名>SCHM001.XSD</測量成果ファイル名> <測量成果ファイル名副題>KsjAppSchema-N02-v1_1.xsd</測量成果ファイル名副題> </成果ファイル情報> </測量成果情報> <測量成果情報> <測量区分フォルダ名>KITEN</測量区分フォルダ名> <測量成果区分フォルダ名>DATA</測量成果区分フォルダ名> <測量細区分フォルダ名>KTN_A</測量細区分フォルダ名> <測量成果名称>コードリスト</測量成果名称> <測量成果ファイル形式>XML</測量成果ファイル形式> <測量成果レコードフォーマット>JPGIS 準拠形式</測量成果レコードフォーマット> <成果ファイル情報> <測量成果ファイル名>CODE001.XML</測量成果ファイル名> <測量成果ファイル名副題>InstitutionTypeCd.xml</測量成果ファイル名副題> </成果ファイル情報> <成果ファイル情報>		<測量成果区分フォルダ名>DATA</測量成果区分フォルダ名> <測量細区分フォルダ名>KTN_A</測量細区分フォルダ名> 付 2-7 <測量成果名称>メタデータ</測量成果名称> <測量成果ファイル形式>XML</測量成果ファイル形式> <測量成果レコードフォーマット>JMP2.0 形式</測量成果レコードフォーマット> <測量成果作成ソフトウェア名>メタデータエディター1.0</測量成果作成ソフトウェア名> <成果ファイル情報> <測量成果ファイル名>KJAA4001.XML</測量成果ファイル名> <測量成果ファイル名副題>KS-META-N02-07.XML</測量成果ファイル名副題> </成果ファイル情報> </測量成果情報> <測量成果情報> <測量区分フォルダ名>KITEN</測量区分フォルダ名> <測量成果区分フォルダ名>DATA</測量成果区分フォルダ名> <測量細区分フォルダ名>KTN_A</測量細区分フォルダ名> <測量成果名称>XML スキーマ</測量成果名称> <測量成果ファイル形式>XSD</測量成果ファイル形式> <測量成果レコードフォーマット>XSD 形式</測量成果レコードフォーマット> <成果ファイル情報> <測量成果ファイル名>SCHM001.XSD</測量成果ファイル名> <測量成果ファイル名副題>KsjAppSchema-N02-v1_1.xsd</測量成果ファイル名副題> </成果ファイル情報> </測量成果情報> <測量成果情報> <測量区分フォルダ名>KITEN</測量区分フォルダ名> <測量成果区分フォルダ名>DATA</測量成果区分フォルダ名> <測量細区分フォルダ名>KTN_A</測量細区分フォルダ名> <測量成果名称>コードリスト</測量成果名称> <測量成果ファイル形式>XML</測量成果ファイル形式> <測量成果レコードフォーマット>JPGIS 準拠形式</測量成果レコードフォーマット> <成果ファイル情報> <測量成果ファイル名>CODE001.XML</測量成果ファイル名> <測量成果ファイル名副題>InstitutionTypeCd.xml</測量成果ファイル名副題> </成果ファイル情報> <成果ファイル情報>

改定（令和７年 12 月）		現行（令和６年３月）
<測量成果ファイル名>CODE002.XML</測量成果ファイル名>		<測量成果ファイル名>CODE002.XML</測量成果ファイル名>
<測量成果ファイル名副題>RailwayClassCd.xml</測量成果ファイル名副題>		<測量成果ファイル名副題>RailwayClassCd.xml</測量成果ファイル名副題>
</成果ファイル情報>		</成果ファイル情報>
</測量成果情報>		</測量成果情報>
<測量成果情報>		<測量成果情報>
<測量区分フォルダ名>KITEN</測量区分フォルダ名>		<測量区分フォルダ名>KITEN</測量区分フォルダ名>
<測量成果区分フォルダ名>OTHRS</測量成果区分フォルダ名>		<測量成果区分フォルダ名>OTHRS</測量成果区分フォルダ名>
<測量細区分フォルダ名> </測量細区分フォルダ名>		<測量細区分フォルダ名> </測量細区分フォルダ名>
<測量成果名称>測量成果検定証明書等</測量成果名称>		<測量成果名称>測量成果検定証明書等</測量成果名称>
<測量成果ファイル形式>PDF</測量成果ファイル形式>		<測量成果ファイル形式>PDF</測量成果ファイル形式>
<測量成果作成ソフトウェア名>ADOBE ACROBAT 7.0</測量成果作成ソフトウェア名>		<測量成果作成ソフトウェア名>ADOBE ACROBAT 7.0</測量成果作成ソフトウェア名>
<成果ファイル情報>		<成果ファイル情報>
<測量成果ファイル名>K0TJ2001.PDF</測量成果ファイル名>		<測量成果ファイル名>K0TJ2001.PDF</測量成果ファイル名>
</成果ファイル情報>		</成果ファイル情報>
<成果ファイル情報>		<成果ファイル情報>
<測量成果ファイル名>K0TJ2002.PDF</測量成果ファイル名>		<測量成果ファイル名>K0TJ2002.PDF</測量成果ファイル名>
</成果ファイル情報>		</成果ファイル情報>
</測量成果情報>		</測量成果情報>
<その他>		<その他>
<受注者説明文/>	変更	<受注者説明文></受注者説明文>
<予備/>	変更	<予備></予備>
付 2-8		付 2-8
</その他>		</その他>
<ソフトメーカ用 TAG/>	変更	<ソフトメーカ用 TAG></ソフトメーカ用 TAG>
</SURV_DATA>		</SURV_DATA>

改定（令和７年 12 月）		現行（令和６年３月）
(3)　ドキュメント管理ファイルの XML 記入例		(3)　ドキュメント管理ファイルの XML 記入例
付 2-9		付 2-9
<?xml version="1.0" encoding="Shift_JIS"?>		<?xml version="1.0" encoding="Shift_JIS"?>
<!DOCTYPE SURV_DOC SYSTEM "SDOC_D01.DTD">		<!DOCTYPE SURV_DOC SYSTEM "SDOC_D01.DTD">
<SURV_DOC DTD_version="01">		<SURV_DOC DTD_version="01">
<ドキュメント情報>		<ドキュメント情報>
<ドキュメント名称>地図情報レベル 2500 データ作成の製品仕様書(案)</ドキュメント名称>		<ドキュメント名称>地図情報レベル 2500 データ作成の製品仕様書(案)</ドキュメント名称>
<ドキュメントファイル形式>PDF</ドキュメントファイル形式>		<ドキュメントファイル形式>PDF</ドキュメントファイル形式>
<ドキュメントファイル名>SPECP001.PDF</ドキュメントファイル名>		<ドキュメントファイル名>SPECP001.PDF</ドキュメントファイル名>
<ドキュメントファイル名副題></ドキュメントファイル名副題>		<ドキュメントファイル名副題></ドキュメントファイル名副題>
<ドキュメント作成ソフトウェア名></ドキュメント作成ソフトウェア名>		<ドキュメント作成ソフトウェア名></ドキュメント作成ソフトウェア名>
</ドキュメント情報>		</ドキュメント情報>
<ドキュメント情報>		<ドキュメント情報>
<ドキュメント名称>空間データ作成のための製品仕様書作成の手引き(案)</ドキュメント名称>		<ドキュメント名称>空間データ作成のための製品仕様書作成の手引き(案)</ドキュメント名称>
<ドキュメントファイル形式>PDF</ドキュメントファイル形式>		<ドキュメントファイル形式>PDF</ドキュメントファイル形式>
<ドキュメントファイル名>SPECP002.PDF</ドキュメントファイル名>		<ドキュメントファイル名>SPECP002.PDF</ドキュメントファイル名>
<ドキュメントファイル名副題></ドキュメントファイル名副題>		<ドキュメントファイル名副題></ドキュメントファイル名副題>
<ドキュメント作成ソフトウェア名></ドキュメント作成ソフトウェア名>		<ドキュメント作成ソフトウェア名></ドキュメント作成ソフトウェア名>
</ドキュメント情報>		</ドキュメント情報>
<ドキュメント情報>		<ドキュメント情報>
<ドキュメント名称>協議書 2025-02-29</ドキュメント名称>	変更	<ドキュメント名称>協議書 2020-02-29</ドキュメント名称>
<ドキュメントファイル形式>PDF</ドキュメントファイル形式>		<ドキュメントファイル形式>PDF</ドキュメントファイル形式>
<ドキュメントファイル名>MEETS001.PDF</ドキュメントファイル名>		<ドキュメントファイル名>MEETS001.PDF</ドキュメントファイル名>
<ドキュメントファイル名副題>協議書 2025-02-29.PDF</ドキュメントファイル名副題>	変更	<ドキュメントファイル名副題>協議書 2020-02-29.PDF</ドキュメントファイル名副題>
<ドキュメント作成ソフトウェア名> Adobe Acrobat DC</ドキュメント作成ソフトウェア名>	変更	<ドキュメント作成ソフトウェア名> ADOBE ACROBAT 7.0</ドキュメント作成ソフトウェア名>
</ドキュメント情報>		</ドキュメント情報>
<ドキュメント情報>		<ドキュメント情報>
<ドキュメント名称>協議書 2025-03-12</ドキュメント名称>	変更	<ドキュメント名称>協議書 2020-03-12</ドキュメント名称>
<ドキュメントファイル形式>PDF</ドキュメントファイル形式>		<ドキュメントファイル形式>PDF</ドキュメントファイル形式>
<ドキュメントファイル名>MEETS002.PDF</ドキュメントファイル名>		<ドキュメントファイル名>MEETS002.PDF</ドキュメントファイル名>
<ドキュメントファイル名副題>協議書 2025-03-12.PDF</ドキュメントファイル名副題>	変更	<ドキュメントファイル名副題>協議書 2020-03-12.PDF</ドキュメントファイル名副題>
<ドキュメント作成ソフトウェア名> Adobe Acrobat DC</ドキュメント作成ソフトウェア名>	変更	<ドキュメント作成ソフトウェア名> ADOBE ACROBAT 7.0</ドキュメント作成ソフトウェア名>
</ドキュメント情報>		</ドキュメント情報>
<ドキュメント情報>		<ドキュメント情報>

改定（令和７年 12 月）		現行（令和６年３月）
<ドキュメント名称>実施報告書</ドキュメント名称> <ドキュメントファイル形式>DOC</ドキュメントファイル形式> <ドキュメントファイル名>SUVRP001.DOC</ドキュメントファイル名> <ドキュメントファイル名副題>実施報告書 001.DOC</ドキュメントファイル名副題> <ドキュメント作成ソフトウェア名>Microsoft Word 2021</ドキュメント作成ソフトウェア名> </ドキュメント情報> <その他> <受注者説明文/> <予備/> </その他> <ソフトメーカ用 TAG/> </SURV_DOC>	変更	<ドキュメント名称>実施報告書</ドキュメント名称> <ドキュメントファイル形式>DOC</ドキュメントファイル形式> <ドキュメントファイル名>SUVRP001.DOC</ドキュメントファイル名> <ドキュメントファイル名副題>実施報告書 001.DOC</ドキュメントファイル名副題> <ドキュメント作成ソフトウェア名>Microsoft Word 2016</ドキュメント作成ソフトウェア名> </ドキュメント情報> <その他> <受注者説明文/> <予備/> </その他> <ソフトメーカ用 TAG/> </SURV_DOC>

改定（令和７年 12 月）		現行（令和６年３月）
付属資料３　成果表数値フォーマット		**付属資料３　成果表数値フォーマット**
1.　基準点測量成果表数値フォーマット		1.　基準点測量成果表数値フォーマット
（1）　基本構造		（1）　基本構造
付 3-1 1）成果表出力フォーマットは、1 行 1 レコードのカンマ区切りのテキストファイルとする。 2）文字コードは UTF-8 を原則とする。 3）成果表出力フォーマットのファイルは、拡張子を“TXT”とする。 4）レコードの記述方法 データ区分 ｜ 区切り ｜ 項目１ ｜ 区切り ｜ ・・・・ ｜ 項目ｎ ｜ 区切り ｜ CRLF データ区分　・その行のデータの種類を表す記号。この情報は省略できない。 ・1 文字目が英字、2,3 文字目が数字の 3 文字とする。 区切り　・各データの項目は、“, ”(カンマ)によって区切るものとする。 ・項目を省略する場合は、“, , ”とする。（スペースは入れない。） 項目 1～項目 n　・データ区分に応じて項目数は変わり、次ページ以降の記載通りとする。 CRLF　・各行の終了コード（0D0Ah）で、各行の最大長は、CRLF を含まず、128 バイトとする。 **留意事項** 1)名称・コメントなど、文字として認識するデータには、“, ”（カンマ）を使用しない。 2)点名称、測器名称、標尺名称、水準点番号などの名称、コメントは全角文字(英数字については半角文字)とし、それ以外のデータは、半角文字とする。	変更	付 3-1 1）成果表出力フォーマットは、1 行 1 レコードのカンマ区切りのテキストファイルとする。 2）文字コードは ASCII コード、漢字コードはシフト JIS コードとする。 3）成果表出力フォーマットのファイルは、拡張子を“TXT”とする。 4）レコードの記述方法 データ区分 ｜ 区切り ｜ 項目１ ｜ 区切り ｜ ・・・・ ｜ 項目ｎ ｜ 区切り ｜ CRLF データ区分　・その行のデータの種類を表す記号。この情報は省略できない。 ・1 文字目が英字、2,3 文字目が数字の 3 文字とする。 区切り　・各データの項目は、“, ”(カンマ)によって区切るものとする。 ・項目を省略する場合は、“, , ”とする。（スペースは入れない。） 項目 1～項目 n　・データ区分に応じて項目数は変わり、次ページ以降の記載通りとする。 CRLF　・各行の終了コード（0D0Ah）で、各行の最大長は、CRLF を含まず、128 バイトとする。 **留意事項** 1)名称・コメントなど、文字として認識するデータには、“, ”（カンマ）を使用しない。 2)点名称、測器名称、標尺名称、水準点番号などの名称、コメントは全角文字(英数字については半角文字)とし、それ以外のデータは、半角文字とする。

改定（令和７年 12 月）

（2）　基準点測量成果表フォーマット

付 3-1

1）　コメントデータ（コメントを示すデータ）

Z00 ， コメント ， フォーマット識別子 ， バージョン ， CRLF

Z00	コメントを示すデータ区分。	省略不可
コメント	桁数の制限はしない。	省略可
フォーマット識別子	本フォーマットの種類を記載する。識別子の表記は下記のとおり。(整数１桁) 1: 基準点測量成果フォーマット 2: 簡易網基準点測量成果フォーマット 3: 水準成果表フォーマット 4: 水準測量観測成果表フォーマット	省略不可
バージョン	本フォーマットのバージョンを記述する。バージョン表記はマイナーチェンジを考慮して小数点形式とし、整数２桁、小数点以下２桁の５桁表記とする。(02.00 に固定)	省略不可

付 3-2

2）　タイトルデータ（業務のタイトル名を示すデータ）

Z01 ， タイトル ， CRLF

Z01	タイトルを示すデータ区分。	省略不可
タイトル	桁数の制限はしない。	省略可

3）　測地系データ（測地系を示すデータ）

Z02 ， 測地系，座標系，CRLF

Z02	測地系を示すデータ区分。	省略不可
測地系	0：世界測地系、1：日本測地系　(0：世界測地系に固定)	省略不可
座標系	平面直角座標系	省略可

日本測地系（測地系＝1）の場合は、Z03 レコード省略可。

4）種類データ（基準点成果の種類・元期を示すデータ）

Z03 ， 成果の種類・元期，CRLF

Z03	成果の種類・元期を示すデータ区分。	省略不可
成果の種類	201：測地成果 2011、202：測地成果 2024	省略不可

5）　座標出力開始データ（座標データの出力開始を示すデータ）

A00 ， CRLF

A00	座標データの出力開始を示すデータ区分。	省略不可

追加

新設

変更

現行（令和６年３月）

（2）　基準点測量成果表フォーマット

付 3-1

1）　コメントデータ（コメントを示すデータ）

Z00 ， コメント ， フォーマット識別子 ， バージョン ， CRLF

Z00	コメントを示すデータ区分。	省略不可
コメント	桁数の制限はしない。	省略可
フォーマット識別子	本フォーマットの種類を記載する。識別子の表記は下記のとおり。(整数１桁) 1: 基準点測量成果フォーマット 2: 簡易網基準点測量成果フォーマット 3: 水準成果表フォーマット 4: 水準測量観測成果表フォーマット	省略不可
バージョン	本フォーマットのバージョンを記述する。バージョン表記はマイナーチェンジを考慮して小数点形式とし、整数２桁、小数点以下２桁の５桁表記とする。(02.00 に固定)	省略不可

付 3-2

2）　タイトルデータ（業務のタイトル名を示すデータ）

Z01 ， タイトル ， CRLF

Z01	タイトルを示すデータ区分。	省略不可
タイトル	桁数の制限はしない。	省略可

3）　測地系データ（測地系を示すデータ）

Z02 ， 測地系，座標系，CRLF

Z02	測地系を示すデータ区分。	省略不可
測地系	0：世界測地系、1：日本測地系　(0：世界測地系に固定)	省略不可
座標系	平面直角座標系	省略可

4）　座標出力開始データ（座標データの出力開始を示すデータ）

A00 ， CRLF

A00	座標データの出力開始を示すデータ区分。	省略不可

改定（令和７年 12 月）

6） 座標データ（点の座標を示すデータ）

A01 ， 点番号 ， 点名称， 緯度， 経度， X 座標， Y 座標， 座標系， 標高， ジオイド高， CRLF

A01	座標データを示すデータ区分。	省略不可
点番号	5 桁以内の整数とする。	省略不可
点名称	40 バイト以下	省略不可
緯度，経度	緯度は、小数点形式（DD°．MM′SS″SSSS）とし、秒以下 4 桁までとする。 経度は、小数点形式（DDD°．MM′SS″SSSS）とし、秒以下 4 桁までとする。 X，Y 座標の記載がある場合は省略可。	省略可
X,Y	小数点形式、m 単位とし、m 以下 3 桁まで記載する。 緯度、経度の記載がある場合は省略可。	省略可
座標系	平面直角座標系（X,Y 座標の記載がある場合は省略不可。）	省略可
標高	小数点形式、m 単位とし、m 以下 3 桁まで記載する。 水平網のみの場合省略可。	省略可
ジオイド高	何も入力せず、空欄とする。	

7） 属性データ（点の属性を示すデータ）

A02 ， 等級， 縮尺係数， 真北方向角， 柱石長， 埋標形式， 標識， 標識番号， アンテナ高， CRLF

A02	属性データを示すデータ区分。	省略不可
等級	2 桁の整数とする。 10：電子基準点付属標 11～14：一等三角点～四等三角点 21～24：1 級基準点～4 級基準点	省略不可
縮尺係数	小数点形式、小数点以下 6 桁まで記載する。	省略不可
真北方向角	小数点形式（DD°．MM′SS″S）とし、秒以下 1 桁までとする。	省略不可
柱石長	小数点形式、m 単位とし、m 以下 2 桁まで記載する。	省略可
埋標形式	0：地上、1：地中、2：屋上	省略不可
標識	0：標石、1：金属標　2：その他	省略不可
標識番号	桁数の制限は行なわず、各社システムに取り込む際、有効桁数に調整する。1,2 級基準点の場合は省略不可。	省略可
アンテナ高		省略可

改算の場合は、「埋標形式」「標識」データ、A03 レコード及び A04 レコードを省略可。

付 3-3

8） 視準データ（視準成果の方向数を示すデータ）

A03 ， 方向数， CRLF

変更

変更
変更
変更

変更
削除
追加

変更

現行（令和６年３月）

5） 座標データ（点の座標を示すデータ）

A01 ， 点番号 ， 点名称， 緯度， 経度， X 座標， Y 座標， 座標系， 標高， ジオイド高， CRLF

A01	座標データを示すデータ区分。	省略不可
点番号	5 桁以内の整数とする。	省略不可
点名称	40 バイト以下	省略不可
緯度，経度	緯度は、小数点形式（DD°．MM′SS″SSSS）とし、秒以下 4 桁までとする。 経度は、小数点形式（DDD°．MM′SS″SSSS）とし、秒以下 4 桁までとする。 X，Y 座標の記載がある場合は省略可。	省略可
X,Y	小数点形式、m 単位とし、m 以下 3 桁まで記載する。 緯度、経度の記載がある場合は省略可。	省略可
座標系	平面直角座標系（X,Y 座標の記載がある場合は省略不可。）	省略可
標高	小数点形式、m 単位とし、m 以下 3 桁まで記載する。 水平網のみの場合省略可。	省略可
ジオイド高	何も入力せず、空欄とする。	

6） 属性データ（点の属性を示すデータ）

A02 ， 等級， 縮尺係数， 真北方向角， 柱石長， 埋標形式， 標識， 標識番号， アンテナ高， CRLF

A02	属性データを示すデータ区分。	省略不可
等級	2 桁の整数とする。 10：電子基準点 11～14：1 等～4 等 21～24：1 級～4 級	省略不可
縮尺係数	小数点形式、小数点以下 6 桁まで記載する。	省略不可
真北方向角	小数点形式（DD°．MM′SS″S）とし、秒以下 1 桁までとする。	省略不可
柱石長	小数点形式、m 単位とし、m 以下 2 桁まで記載する。	省略可
埋標形式	0：地上、1：地中、2：屋上	省略不可
標識	0：標石、1：金属標　2：その他	省略不可
標識番号	桁数の制限は行なわず、各社システムに取り込む際、有効桁数に調整する。1,2 級の場合は省略不可。	省略可
アンテナ高	等級 10：電子基準点の時省略不可。	省略可

付 3-3

7） 視準データ（視準成果の方向数を示すデータ）

A03 ， 方向数， CRLF

改定（令和７年 12 月）

A03	視準成果データを示すデータ区分。	省略不可
方向数	2 桁以内の整数とする。	省略不可

視準成果が無い（方向数=0）場合は、A04 レコードを省略可。

9） 視準データ（点の視準成果を示すデータ）

A04 ， 点番号， 点名称， 等級， 平均方向角， 距離， 備考， 観測日， CRLF

A04	視準成果データを示すデータ区分。	省略不可
点番号	5 桁以内の整数とする。	省略不可
点名称	40 バイト以下	省略不可
等級	2 桁の整数とする。 10：電子基準点付属標 11～14：一等三角点～四等三角点 21～24：1 級基準点～4 級基準点	省略不可
平均方向角	平均方向角は、小数点形式（DD°．MM′SS″S）とし、秒以下 1 桁までとする。	省略不可
距離	小数点形式、m 単位とし、m 以下 3 桁まで記載する。	省略不可
備考	桁数の制限はしない。	省略可
観測日	形式（YYYY-MM-DD：年月日） 観測が複数日にわたる場合は、観測初日を記載する。	省略可

9） 座標出力終了データ（座標データの出力終了を示すデータ）

A99 ， CRLF

A99	座標データの出力終了を示すデータ区分。	省略不可

出力例 1

Z00,SEIKA,1,03.00,
Z01,令和 7 年度 1 級基準点測量（範例集データ）,
Z02,0,9,
Z03,202,
A00,
A01,1,広尾,36.02416679,140.09147463,5029.510,28898.460,9,37.150,,
A02,21,0.999910,-0.11195,0.79,0,0,1,,
A03,1,
A04,4,1,21,192.13210,747.348,,,
A99,

付 3-4

変更
変更
変更
変更
変更
変更
変更
新設
変更

現行（令和６年３月）

A03	視準成果データを示すデータ区分。	省略不可
方向数	2 桁以内の整数とする。	省略不可

視準成果が無い（方向数=0）場合は、A04 レコードを省略可。

8） 視準データ（点の視準成果を示すデータ）

A04 ， 点番号， 点名称， 等級， 平均方向角， 距離， 備考， 観測日， CRLF

A04	視準成果データを示すデータ区分。	省略不可
点番号	5 桁以内の整数とする。	省略不可
点名称	40 バイト以下	省略不可
等級	2 桁の整数とする。 10：電子基準点 11～14：1 等～4 等 21～24：1 級～4 級	省略不可
平均方向角	平均方向角は、小数点形式（DD°．MM′SS″S）とし、秒以下 1 桁までとする。	省略不可
距離	小数点形式、m 単位とし、m 以下 3 桁まで記載する。	省略不可
備考	桁数の制限は行なわず、各社システムに取り込む際、有効桁数に調整する。	省略可
観測日	形式（YYYYMMDD：年月日）：GNSS 測量時省略不可。 観測が複数日にわたる場合は、観測初日を記載する。	省略可

9） 座標出力終了データ（座標データの出力終了を示すデータ）

A99 ， CRLF

A99	座標データの出力終了を示すデータ区分。	省略不可

出力例 1

Z00,SEIKA,1,02.00,
Z01,令和 2 年度 1 級基準点測量（範例集データ）,
Z02,0,9,

A00,
A01,1,広尾,36.02416679,140.09147463,5029.510,28898.460,9,37.150,,
A02,13,0.999910,-0.11195,0.79,0,0,1,,
A03,1,
A04,4,1,21,192.13210,747.348,,,
A99,

改定（令和７年 12 月）		現行（令和６年３月）
出力例 2 Z00,SEIKA,1,03.00, Z01,令和 7 年度 1 級基準点測量（範例集データ）, Z02,0,9, Z03,202, A00, A01,4,1,36.02179849,140.09083291,4299.168,28740.254,9,23.180,, A02,21,0.999910,-0.11156,0.60,0,1,1,, A03,2, A04,1,広尾,13,12.13211,747.348,,, A04,5,2,21,183.59117,1329.395,,, A01,5,2,36.01349635,140.09044637,2973.109,28647.839,9,33.946,, A02,21,0.999910,-0.11131,0.09,2,1,2,, A03,3, A04,4,1,21,3.59119,1329.395,,, A04,2,浅川,13,85.14023,1091.503,,, A04,3,上野山,13,262.39258,987.435,,, A99,	変更 変更 新設	出力例 2 Z00,SEIKA,1,02.00, Z01,令和 2 年度 1 級基準点測量（範例集データ）, Z02,0,9, A00, A01,4,1,36.02179849,140.09083291,4299.168,28740.254,9,23.180,, 付 3-4 A02,21,0.999910,-0.11156,0.60,0,1,1,, A03,2, A04,1,広尾,13,12.13211,747.348,,, A04,5,2,21,183.59117,1329.395,,, A01,5,2,36.01349635,140.09044637,2973.109,28647.839,9,33.946,, A02,21,0.999910,-0.11131,0.09,2,1,2,, A03,3, A04,4,1,21,3.59119,1329.395,,, A04,2,浅川,13,85.14023,1091.503,,, A04,3,上野山,13,262.39258,987.435,,, A99,
出力例 3 Z00,SEIKA,1,03.00, Z01,令和 7 年度 3 級基準点測量（PatchJGD（標高版）を用いた改算）, Z02,0,9, Z03,202, A00, A01,4,1,36.02179849,140.09083291,4299.168,28740.254,9,23.180,, A02,23,0.999910,-0.11156,,,,,, A01,5,2,36.01349635,140.09044637,2973.109,28647.839,9,33.946,, A02,23,0.999910,-0.11131,,,,,, A99,	追加	

改定（令和７年 12 月）

(3)　簡易網基準点測量成果表フォーマット

付 3-4

1)　コメントデータ（コメントを示すデータ）

Z00 ， コメント ， フォーマット識別子 ， バージョン ， CRLF

Z00	コメントを示すデータ区分。	省略不可
コメント	桁数の制限はしない。	省略可
フォーマット識別子	本フォーマットの種類を記載する。識別子の表記は下記のとおり。(整数１桁) 1: 基準点測量成果フォーマット 2: 簡易網基準点測量成果フォーマット 3: 水準成果表フォーマット 4: 水準測量観測成果表フォーマット	省略不可
バージョン	本フォーマットのバージョンを記述する。バージョン表記はマイナーチェンジを考慮して小数点形式とし、整数２桁、小数点以下２桁の５桁表記とする。(02.00 に固定)	省略不可

付 3-5

2)　タイトルデータ（業務のタイトル名を示すデータ）

Z01 ， タイトル ， CRLF

Z01	タイトルを示すデータ区分。	省略不可
タイトル	桁数の制限はしない。	省略可

3)　測地系データ（測地系を示すデータ）

Z02 ， 測地系，座標系，CRLF

Z02	測地系を示すデータ区分。	省略不可
測地系	0：世界測地系、1：日本測地系　(0：世界測地系に固定)	省略不可
座標系	平面直角座標系	省略可

日本測地系（測地系＝1）の場合は、Z03 レコード省略可。

4）種類データ（基準点成果の種類・元期を示すデータ）

Z03 ， 成果の種類・元期，CRLF

Z03	成果の種類・元期を示すデータ区分。	省略不可
成果の種類	201：測地成果 2011、202：測地成果 2024	省略不可

5)　座標出力開始データ（座標データの出力開始を示すデータ）

A00 ， CRLF

A00	座標データの出力開始を示すデータ区分。	省略不可

現行（令和６年３月）

(3)　簡易網基準点測量成果表フォーマット

付 3-4

1)　コメントデータ（コメントを示すデータ）

Z00 ， コメント ， フォーマット識別子 ， バージョン ， CRLF

Z00	コメントを示すデータ区分。	省略不可
コメント	桁数の制限はしない。	省略可
フォーマット識別子	本フォーマットの種類を記載する。識別子の表記は下記のとおり。(整数１桁) 1: 基準点測量成果フォーマット 2: 簡易網基準点測量成果フォーマット 3: 水準成果表フォーマット 4: 水準測量観測成果表フォーマット	省略不可
バージョン	本フォーマットのバージョンを記述する。バージョン表記はマイナーチェンジを考慮して小数点形式とし、整数２桁、小数点以下２桁の５桁表記とする。(02.00 に固定)	省略不可

2)　タイトルデータ（業務のタイトル名を示すデータ）

Z01 ， タイトル ， CRLF

Z01	タイトルを示すデータ区分。	省略不可
タイトル	桁数の制限はしない。	省略可

3)　測地系データ（測地系を示すデータ）

Z02 ， 測地系，座標系，CRLF

Z02	測地系を示すデータ区分。	省略不可
測地系	0：世界測地系、1：日本測地系　(0：世界測地系に固定)	省略不可
座標系	平面直角座標系	省略可

4)　座標出力開始データ（座標データの出力開始を示すデータ）

A00 ， CRLF

A00	座標データの出力開始を示すデータ区分。	省略不可

追加

新設

変更

改定（令和７年 12 月）

6） 座標データ（点の座標を示すデータ）

A01 ， 点番号 ， 点名称， 緯度， 経度， X 座標， Y 座標， 座標系， 標高， ジオイド高， CRLF

A01	座標データを示すデータ区分。	省略不可
点番号	5 桁以内の整数とする。	省略不可
点名称	40 バイト以下	省略不可
緯度，経度	緯度は、小数点形式（DD°．MM′SS″SSSS）とし、秒以下 4 桁までとする。 経度は、小数点形式（DDD°．MM′SS″SSSS）とし、秒以下 4 桁までとする。 X，Y 座標の記載がある場合は省略可。	省略可
X,Y	小数点形式、m 単位とし、m 以下 3 桁まで記載する。 緯度、経度の記載がある場合は省略可。	省略不可
座標系	平面直角座標系	省略不可
標高	小数点形式、m 単位とし、m 以下 3 桁まで記載する。 水平網のみの場合省略可。	省略可
ジオイド高	何も入力せず、空欄とする。	

7） 属性データ（点の属性を示すデータ）

A02 ， 等級， 縮尺係数， 真北方向角， 柱石長， 埋標形式， 標識， 標識番号， アンテナ高， CRLF

A02	属性データを示すデータ区分。	省略不可
等級	2 桁の整数とする。 10：電子基準点付属標 11～14：一等三角点～四等三角点 21～24：1 級基準点～4 級基準点	省略不可
縮尺係数	小数点形式、小数点以下 6 桁まで記載する。	省略可
真北方向角	小数点形式（DD°．MM′SS″S）とし、秒以下 1 桁までとする。	省略可
柱石長	小数点形式、m 単位とし、m 以下 2 桁まで記載する。	省略可
埋標形式	0：地上、1：地中、2：屋上	省略可
標識	0：標石、1：金属標　2：その他	省略可
標識番号	桁数の制限はしない。	省略可
アンテナ高		省略可

付 3-6

8） 視準データ（視準成果の方向数を示すデータ）

A03 ， 方向数， CRLF

A03	視準成果データを示すデータ区分。	省略不可

現行（令和６年３月）

5） 座標データ（点の座標を示すデータ）

A01 ， 点番号 ， 点名称， 緯度， 経度， X 座標， Y 座標， 座標系， 標高， ジオイド高， CRLF

A01	座標データを示すデータ区分。	省略不可
点番号	5 桁以内の整数とする。	省略不可
点名称	40 バイト以下	省略不可
緯度，経度	緯度は、小数点形式（DD°．MM′SS″SSSS）とし、秒以下 4 桁までとする。 経度は、小数点形式（DDD°．MM′SS″SSSS）とし、秒以下 4 桁までとする。 X，Y 座標の記載がある場合は省略可。	省略可
X,Y	小数点形式、m 単位とし、m 以下 3 桁まで記載する。 緯度、経度の記載がある場合は省略可。	省略不可
座標系	平面直角座標系	省略不可
標高	小数点形式、m 単位とし、m 以下 3 桁まで記載する。 水平網のみの場合省略可。	省略可
ジオイド高	何も入力せず、空欄とする。	

付 3-5

6） 属性データ（点の属性を示すデータ）

A02 ， 等級， 縮尺係数， 真北方向角， 柱石長， 埋標形式， 標識， 標識番号， アンテナ高， CRLF

A02	属性データを示すデータ区分。	省略不可
等級	2 桁の整数とする。 10：電子基準点 11～14：1 等～4 等 21～24：1 級～4 級	省略不可
縮尺係数	小数点形式、小数点以下 6 桁まで記載する。	省略可
真北方向角	小数点形式（DD°．MM′SS″S）とし、秒以下 1 桁までとする。	省略可
柱石長	小数点形式、m 単位とし、m 以下 2 桁まで記載する。	省略可
埋標形式	0：地上、1：地中、2：屋上	省略可
標識	0：標石、1：金属標　2：その他	省略可
標識番号	桁数の制限は行なわず、各社システムに取り込む際、有効桁数に調整する。	省略可
アンテナ高	等級 10：電子基準点の時省略不可。	省略可

7） 視準データ（視準成果の方向数を示すデータ）

A03 ， 方向数， CRLF

A03	視準成果データを示すデータ区分。	省略不可

変更

変更

変更

変更

変更

変更

削除

変更

改定（令和７年 12 月）

方向数	2 桁以内の整数とする。（方向が無い場合は 0 を入れる。）	省略不可

視準成果が無い（方向数=0）場合は、A04 レコードを省略可。

9） 視準データ（点の視準成果を示すデータ）

A04 ， 点番号， 点名称， 等級， 平均方向角， 距離， 備考， 観測日， CRLF

A04	視準成果データを示すデータ区分。	省略不可
点番号	5 桁以内の整数とする。	省略可
点名称	40 バイト以下	省略可
等級	2 桁の整数とする。 10：電子基準点付属標 11～14：一等三角点～四等三角点 21～24：1 級基準点～4 級基準点	省略可
平均方向角	平均方向角は、小数点形式（DD°．MM′SS″S）とし、秒以下 1 桁までとする。	省略可
距離	小数点形式、m 単位とし、m 以下 3 桁まで記載する。	省略可
備考	桁数の制限はしない。	省略可
観測日	形式（YYYY-MM-DD：年月日） 観測が複数日にわたる場合は、観測初日を記載する。	省略可

10） 座標出力終了データ（座標データの出力終了を示すデータ）

A99 ， CRLF

A99	座標データの出力終了を示すデータ区分。	省略不可

出力例 1

Z00,SEIKA,2,02.00,
Z01, 令和 7 年度 3 級基準点新点設置業務,
Z02,1,9,
Z03,202,
A00,
A01,1,301,,,-58831.120,29318.870,9,132.230,,
A02,22,,,,0,1,H15-20-1,,
A03,2,
A04,2,305,22,15.31211,423.068,,,
A04,3,1,23,169.53258,159.276,,,

現行（令和６年３月）

方向数	2 桁以内の整数とする。（方向が無い場合は 0 を入れる。）	省略不可

視準成果が無い（方向数=0）場合は、A04 レコードを省略可。

8） 視準データ（点の視準成果を示すデータ）

A04 ， 点番号， 点名称， 等級， 平均方向角， 距離， 備考， 観測日， CRLF

A04	視準成果データを示すデータ区分。	省略不可
点番号	5 桁以内の整数とする。	省略可
点名称	40 バイト以下	省略可
等級	2 桁の整数とする。 10：電子基準点 11～14：1 等～4 等 21～24：1 級～4 級	省略可
平均方向角	平均方向角は、小数点形式（DD°．MM′SS″S）とし、秒以下 1 桁までとする。	省略可
距離	小数点形式、m 単位とし、m 以下 3 桁まで記載する。	省略可
備考	桁数の制限は行なわず、各社システムに取り込む際、有効桁数に調整する。	省略可
観測日	形式（YYYYMMDD：年月日） 観測が複数日にわたる場合は、観測初日を記載する。	省略可

付 3-6

9） 座標出力終了データ（座標データの出力終了を示すデータ）

A99 ， CRLF

A99	座標データの出力終了を示すデータ区分。	省略不可

出力例 1

Z00,SEIKA,2,02.00,
Z01, 令和 2 年度 3 級基準点新点設置業務,
Z02,1,9,

A00,
A01,1,301,,,-58831.120,29318.870,9,132.230,,
A02,22,,,,0,1,H15-20-1,,
A03,2,
A04,2,305,22,15.31211,423.068,,,
A04,3,1,23,169.53258,159.276,,,

変更
変更
変更
変更
変更
変更
変更
変更
新設

改定（令和７年 12 月）		現行（令和６年３月）
付 3-7 A01,3,1,,,-58987.909,29346.825,9,124.602,, A02,23,,,,0,2,,, A03,2, A04,4,2,23,181.36454,153.252,,, A04,1,301,22,349.53259,159.276,,, A01,4,2,,,-59141.086,29342.513,9,123.098,, A02,23,,,,0,2,,, A03,3, A04,3,1,23,1.36454,153.252,,, A04,5,9,23,52.16209,147.709,,, A04,6,3,23,169.18515,160.714,,, A01,6,3,,,-59299.000,29372.310,9,121.026,, A02,23,,,,0,2,,, A03,2, A04,7,4,23,191.03221,161.453,,, A04,4,2,23,349.18515,160.714,,, A01,7,4,,,-59457.442,29341.351,9,121.774, A02,23,,,,0,2,,, A03,3, A04,6,3,23,11.03221,161.453,,, A04,8,10,23,53.45583,139.967,,, A04,9,501,23,159.17026,72.385,,, A01,10,302,,,-59713.720,29291.070,9,132.180,, A02,22,,,,0,1,H15-20-3,, A03,2, A04,9,501,23,21.55108,203.293,,, A04,11,306,22,176.42512,394.864,,, A99,		A01,3,1,,,-58987.909,29346.825,9,124.602,, A02,23,,,,0,2,,, A03,2, A04,4,2,23,181.36454,153.252,,, A04,1,301,22,349.53259,159.276,,, A01,4,2,,,-59141.086,29342.513,9,123.098,, A02,23,,,,0,2,,, A03,3, A04,3,1,23,1.36454,153.252,,, A04,5,9,23,52.16209,147.709,,, A04,6,3,23,169.18515,160.714,,, A01,6,3,,,-59299.000,29372.310,9,121.026,, A02,23,,,,0,2,,, A03,2, A04,7,4,23,191.03221,161.453,,, A04,4,2,23,349.18515,160.714,,, A01,7,4,,,-59457.442,29341.351,9,121.774, A02,23,,,,0,2,,, A03,3, A04,6,3,23,11.03221,161.453,,, A04,8,10,23,53.45583,139.967,,, A04,9,501,23,159.17026,72.385,,, A01,10,302,,,-59713.720,29291.070,9,132.180,, A02,22,,,,0,1,H15-20-3,, A03,2, A04,9,501,23,21.55108,203.293,,, A04,11,306,22,176.42512,394.864,,, A99,

改定（令和７年 12 月）

（4） 水準測量成果表フォーマット

付 3-8

1） コメントデータ（コメントを示すデータ）

Z00 ， コメント ， バージョン ， フォーマット識別子 ， CRLF

Z00	コメントを示すデータ区分。	省略不可
コメント	桁数の制限はしない。	省略可
フォーマット識別子	本フォーマットの種類を記載する。識別子の表記は下記のとおり。(整数１桁) 1: 基準点測量成果フォーマット 2: 簡易網基準点測量成果フォーマット 3: 水準成果表フォーマット(注 1) 4: 水準測量観測成果表フォーマット	省略不可
バージョン	本フォーマットのバージョンを記述する。バージョン表記は、マイナーチェンジを考慮して小数点形式とし、整数 2 桁、小数点以下 2 桁の 5 桁表記とする。(02.00 に固定)	省略不可

（注 1）レベル等による水準測量及び GNSS 標高測量に適用

2） タイトルデータ（業務のタイトル名を示すデータ）

Z01 ， タイトル ， CRLF

Z01	タイトルを示すデータ区分。	省略不可
タイトル	桁数の制限はしない。	省略不可

3）測地系データ（測地系を示すデータ）

Z02 ， 測地系，座標系，CRLF

Z02	測地系を示すデータ区分。	省略可
測地系	0：世界測地系、1：日本測地系 （0：世界測地系に固定）	省略可
座標系	平面直角座標系	省略可

4） 種類データ（水準成果の種類・元期を示すデータ）

Z03 ， 成果の種類，CRLF

Z03	成果の種類を示すデータ区分。	省略不可
成果の種類	201：測地成果 2011、202：測地成果 2024、999：その他	省略可

5） 座標出力開始データ（座標データの出力開始を示すデータ）

S00 ， CRLF

S00	座標データの出力開始を示すデータ区分。	省略不可

6） 座標データ（点の座標を示すデータ）

S01 ， 点番号 ， 点名称，緯度，経度，Ｘ座標，Ｙ座標，座標系，標高，等級，CRLF

現行（令和６年３月）

（4） 水準測量成果表フォーマット

付 3-7

1） コメントデータ（コメントを示すデータ）

Z00 ， コメント ， バージョン ， フォーマット識別子 ， CRLF

Z00	コメントを示すデータ区分。	省略不可
コメント	桁数の制限はしない。	省略可
フォーマット識別子	本フォーマットの種類を記載する。識別子の表記は下記のとおり。(整数１桁) 1: 基準点測量成果フォーマット 2: 簡易網基準点測量成果フォーマット 3: 水準成果表フォーマット(注 1) 4: 水準測量観測成果表フォーマット	省略不可
バージョン	本フォーマットのバージョンを記述する。バージョン表記は、マイナーチェンジを考慮して小数点形式とし、整数 2 桁、小数点以下 2 桁の 5 桁表記とする。(02.00 に固定)	省略不可

（注 1）レベル等による水準測量及び GNSS 測量機による水準測量に適用

2） タイトルデータ（業務のタイトル名を示すデータ）

Z01 ， タイトル ， CRLF

Z01	タイトルを示すデータ区分。	省略不可
タイトル	桁数の制限はしない。	省略不可

3） 種類データ（水準成果の種類を示すデータ）

Z03 ， 成果の種類，CRLF

Z03	成果の種類を示すデータ区分。	省略不可
成果の種類	桁数の制限はしない。	省略可

4） 座標出力開始データ（座標データの出力開始を示すデータ）

S00 ， CRLF

S00	座標データの出力開始を示すデータ区分。	省略可

5） 座標データ（点の座標を示すデータ）

S01 ， 点番号 ， 点名称，緯度，経度，Ｘ座標，Ｙ座標，座標系，標高，等級，CRLF

変更

変更

新設

変更

変更

変更

変更

変更

改定（令和７年 12 月）

S01	座標データを示すデータ区分。	省略不可
点番号	11 桁の整数を標準とする。	省略不可
点名称	40 バイト以下	省略可

付 3-9

6）座標データ（点の座標を示すデータ）の表　のつづき

緯度，経度	緯度は、小数点形式（DD°．MM′SS″SSSS）とし、秒以下 4 桁までとする。 経度は、小数点形式（DDD°．MM′SS″SSSS）とし、秒以下 4 桁までとする。	省略可
X,Y	小数点形式、m 単位とし、m 以下 1 桁まで記載する。	省略可
座標系	平面直角座標系（X、Y がある時は省略不可）	省略可
標高	小数点形式、m 単位とし、m 以下 4 桁まで記載する。 成果が m 以下 3 桁までの場合は最後に 0 を付ける。	省略不可
等級	2 桁の整数とする。 10：電子基準点付属標 11～13：一等水準点～三等水準点 21～24：1 級水準点～4 級水準点 25：簡易水準点	省略不可

7）座標出力終了データ（座標データの出力終了を示すデータ）

S99，CRLF

S99	座標データの出力終了を示すデータ区分。	省略不可

出力例

Z00, SEIKA,3,02.00,
Z01,令和 7 年度 1 級水準測量,
Z02,0,9
Z03,202,
S00,
S01,00000000001,,,,11802.5,22856.5,9,144.6150,21,
S01,00000000002,,,,11527.9,22777.1,9,109.7710,21,
S99,

現行（令和６年３月）

S01	座標データを示すデータ区分。	省略不可
点番号	11 桁の整数を標準とする。	省略不可
点名称	40 バイト以下	省略可
緯度，経度	緯度は、小数点形式（DD°．MM′SS″SSSS）とし、秒以下 4 桁までとする。 経度は、小数点形式（DDD°．MM′SS″SSSS）とし、秒以下 4 桁までとする。	省略可
X,Y	小数点形式、m 単位とし、m 以下 1 桁まで記載する。	省略可
座標系	平面直角座標系（X、Y がある時は省略不可）	省略可
標高	小数点形式、m 単位とし、m 以下 4 桁まで記載する。 成果が m 以下 3 桁までの場合は最後に 0 を付ける。	省略不可
等級	2 桁の整数とする。 11～14：1 等～4 等 21～24：1 級～4 級 25：簡易	省略不可

付 3-8

6）座標出力終了データ（座標データの出力終了を示すデータ）

S99，CRLF

S99	座標データの出力終了を示すデータ区分。	省略不可

出力例

Z00, SEIKA,3,02.00,
Z01,令和 2 年度 1 級水準測量,
Z03,測地成果 2011,
S00,
S01,00000000001,,36.02179849,140.09083291,,,9,144.6150,21,
S01,00000000002,,36.02181949,140.09329108,,,,9,109.7710,21,
S99,

変更	S01
変更	点番号
変更	点名称
変更	緯度，経度
	X,Y
	座標系
	標高
	等級
変更	Z01
新設	Z02
変更	Z03
	S00
変更	S01
変更	S01
	S99

改定（令和７年 12 月）

（5）　水準測量観測成果表フォーマット

付 3-10

（5）　水準測量観測成果表フォーマット

1）　コメントデータ（コメントを示すデータ）

Z00 ， コメント ， フォーマット識別子，バージョン ， CRLF

Z00	コメントを示すデータ区分。	省略不可
コメント	桁数の制限はしない。	省略可
フォーマット識別子	本フォーマットの種類を記載する。識別子の表記は下記のとおり。(整数 1 桁) 1: 基準点測量成果フォーマット 2: 簡易網基準点測量成果フォーマット 3: 水準成果表フォーマット 4: 水準測量観測成果表フォーマット(注 1)	省略不可
バージョン	本フォーマットのバージョンを記述する。バージョン表記はマイナーチェンジを考慮して小数点形式とし、整数 2 桁、小数点以下 2 桁の 5 桁表記とする。(02.00 に固定)	省略不可

（注 1）レベル等による水準測量のみに適用

2）　タイトルデータ（業務のタイトル名を示すデータ）

Z01 ， タイトル ， CRLF

Z01	タイトルを示すデータ区分。	省略不可
タイトル	桁数の制限はしない。	省略可

3）　種類データ（水準成果の種類を示すデータ）

Z03 ， 成果の種類，CRLF

Z03	成果の種類を示すデータ区分。	省略不可
成果の種類	201：測地成果 2011、202：測地成果 2024、999：その他	省略不可

4）　出力開始データ（データの出力開始を示すデータ）

P00 ， CRLF

P00	水準測量観測成果表の出力開始を示すデータ区分。	省略不可

5）　路線開始データ（路線開始を示すデータ）

P01 ， 路線番号，CRLF

P01	路線開始を示すデータ区分。	省略不可
路線番号	桁数の制限はしない。	省略不可

変更

現行（令和６年３月）

（5）　水準測量観測成果表フォーマット

付 3-9

（5）　水準測量観測成果表フォーマット

1）　コメントデータ（コメントを示すデータ）

Z00 ， コメント ， フォーマット識別子，バージョン ， CRLF

Z00	コメントを示すデータ区分。	省略不可
コメント	桁数の制限はしない。	省略可
フォーマット識別子	本フォーマットの種類を記載する。識別子の表記は下記のとおり。(整数 1 桁) 1: 基準点測量成果フォーマット 2: 簡易網基準点測量成果フォーマット 3: 水準成果表フォーマット 4: 水準測量観測成果表フォーマット(注 1)	省略不可
バージョン	本フォーマットのバージョンを記述する。バージョン表記はマイナーチェンジを考慮して小数点形式とし、整数 2 桁、小数点以下 2 桁の 5 桁表記とする。(02.00 に固定)	省略不可

（注 1）レベル等による水準測量のみに適用

2）　タイトルデータ（業務のタイトル名を示すデータ）

Z01 ， タイトル ， CRLF

Z01	タイトルを示すデータ区分。	省略不可
タイトル	桁数の制限はしない。	省略可

3）　種類データ（水準成果の種類を示すデータ）

Z03 ， 成果の種類，CRLF

Z03	成果の種類を示すデータ区分。	省略不可
成果の種類	桁数の制限はしない。	省略不可

4）　出力開始データ（データの出力開始を示すデータ）

P00 ， CRLF

P00	水準測量観測成果表の出力開始を示すデータ区分。	省略不可

5）　路線開始データ（路線開始を示すデータ）

P01 ， 路線番号，CRLF

P01	路線開始を示すデータ区分。	省略不可
路線番号	桁数の制限はしない。	省略不可

改定（令和７年 12 月）

6） 地区情報データ（測量地区を示すデータ）

P02 ， 自水準点番号， 至水準点番号， 自地区名,至地区名， CRLF

P02	地区情報を示すデータ区分。	省略不可
自水準点番号	先頭の自水準点番号を入力する。	省略不可
至水準点番号	最後の至水準点番号を入力する。	省略不可
自地区名	桁数の制限はしない。	省略不可
至地区名	桁数の制限はしない。	省略不可

付 3-11

7） 観測情報データ（観測情報を示すデータ）

P03 ， 観測者， 測器名称， 測器番号， 標尺名称， 標尺番号， 膨張係数， 標尺係数， CRLF

P03	観測情報を示すデータ区分。	省略不可
観測者	桁数の制限はしない。	省略不可
測器名称	桁数の制限はしない。	省略不可
測器番号	桁数の制限はしない。	省略不可
標尺名称	桁数の制限はしない。	省略不可
標尺番号	桁数の制限はしない。	省略不可
膨張係数	小数点形式、小数点以下 2 桁まで記載する。	省略不可
標尺係数	小数点形式、小数点以下 2 桁まで記載する。	省略不可

8） 路線終了データ（路線終了を示すデータ）

P04 ， CRLF

P04	路線終了を示すデータ区分。	省略不可

9） 観測比高データ

P05 ， 水準点番号 1， 水準点番号 2， 距離， 往復測点数， 水準差 1， 水準差 2， 温度， 標尺補正数， 観測高低差， 観測月日， 正標高補正数， 変動補正数， 観測高低差結果， 備考， CRLF

P05	観測比高を示すデータ区分。	省略不可
水準点番号 1	桁数の制限は行なわず、有効桁数に調整する。	省略不可
水準点番号 2	桁数の制限は行なわず、有効桁数に調整する。	省略不可
距離	小数点形式、km 単位とし、km 以下 3 桁まで記載する。	省略不可
往復観測数	整数値とする。	省略不可
水準差 1	小数点形式、m 単位とし、m 以下 4 桁まで記載する。	省略不可
水準差 2	小数点形式、m 単位とし、m 以下 4 桁まで記載する。	省略不可
温度	単位は摂氏とし、整数値とする。	省略不可
標尺補正数	小数点形式、mm 単位とし、mm 以下 1 桁まで記載する。	省略不可
観測高低差	小数点形式、m 単位とし、m 以下 4 桁まで記載する。	省略不可
観測年月日	形式（YYYY-MM-DD：年月日）	省略不可

変更

現行（令和６年３月）

6） 地区情報データ（測量地区を示すデータ）

P02 ， 自水準点番号， 至水準点番号， 自地区名,至地区名， CRLF

P02	地区情報を示すデータ区分。	省略不可
自水準点番号	先頭の自水準点番号を入力する。	省略不可
至水準点番号	最後の至水準点番号を入力する。	省略不可
自地区名	桁数の制限はしない。	省略不可
至地区名	桁数の制限はしない。	省略不可

付 3-10

7） 観測情報データ（観測情報を示すデータ）

P03 ， 観測者， 測器名称， 測器番号， 標尺名称， 標尺番号， 膨張係数， 標尺係数， CRLF

P03	観測情報を示すデータ区分。	省略不可
観測者	桁数の制限はしない。	省略不可
測器名称	桁数の制限はしない。	省略不可
測器番号	桁数の制限はしない。	省略不可
標尺名称	桁数の制限はしない。	省略不可
標尺番号	桁数の制限はしない。	省略不可
膨張係数	小数点形式、小数点以下 2 桁まで記載する。	省略不可
標尺係数	小数点形式、小数点以下 2 桁まで記載する。	省略不可

8） 路線終了データ（路線終了を示すデータ）

P04 ， CRLF

P04	路線終了を示すデータ区分。	省略不可

9） 観測比高データ

P05 ， 水準点番号 1， 水準点番号 2， 距離， 往復測点数， 水準差 1， 水準差 2， 温度， 標尺補正数， 観測高低差， 観測月日， 正標高補正数， 変動補正数， 観測高低差結果， 備考， CRLF

P05	観測比高を示すデータ区分。	省略不可
水準点番号 1	桁数の制限は行なわず、有効桁数に調整する。	省略不可
水準点番号 2	桁数の制限は行なわず、有効桁数に調整する。	省略不可
距離	小数点形式、km 単位とし、km 以下 3 桁まで記載する。	省略不可
往復観測数	整数値とする。	省略不可
水準差 1	小数点形式、m 単位とし、m 以下 4 桁まで記載する。	省略不可
水準差 2	小数点形式、m 単位とし、m 以下 4 桁まで記載する。	省略不可
温度	単位は摂氏とし、整数値とする。	省略不可
標尺補正数	小数点形式、mm 単位とし、mm 以下 1 桁まで記載する。	省略不可
観測高低差	小数点形式、m 単位とし、m 以下 4 桁まで記載する。	省略不可
観測月日	月と日を“/”で区切ることとする。（例　1/31）	省略不可

改定（令和７年 12 月）

正標高補正数	小数点形式、mm 単位とし、mm 以下 1 桁まで記載する。 楕円補正と同時に使用することは不可。	省略可
変動補正数	小数点形式、mm 単位とし、mm 以下 1 桁まで記載する。 地盤沈下調査は省略不可。	省略可
観測高低差結果	小数点形式、m 単位とし、m 以下 4 桁まで記載する。地盤沈下調査は省略不可。	省略可
備考	桁数の制限はしない。	省略可

10）観測点データ

P06 ， 水準点番号，観測標高，楕円補正，単路線閉合差補正，結果，与点・求点の別，備考，CRLF

P06	共通情報を示すデータ区分。	省略不可
水準点番号	P05 で使用されている名称を使用する。	省略不可
観測標高	小数点形式、m 単位とし、m 以下 4 桁まで記載する。	省略不可
楕円補正	小数点形式、mm 単位とし、mm 以下 1 桁まで記載する。 正標高補正数と同時に使用することは不可。	省略可
単路線閉合差	小数点形式、mm 単位とし、mm 以下 1 桁まで記載する。	省略可

付 3-12　***P06*** の表の　つづき

補正		
結果	小数点形式、m 単位とし、m 以下 4 桁まで記載する。	省略不可
与点・求点の別	0：求点、1：与点	省略不可
備考	桁数の制限はしない。	省略可

11）距離合計データ（距離合計を示すデータ）

P07 ， 距離合計，CRLF

P07	路線距離合計を示すデータ区分。	省略不可
距離合計	小数点形式、km 単位とし、km 以下 3 桁まで記載する。	省略不可

12）距離累計データ（距離累計を示すデータ）

P08 ， 距離累計，CRLF

P08	路線距離累計を示すデータ区分。	省略不可
距離累計	小数点形式、km 単位とし、km 以下 3 桁まで記載する。	省略不可

13）出力終了データ（終了を示すデータ）

P99 ， CRLF

削除

現行（令和６年３月）

正標高補正数	小数点形式、mm 単位とし、mm 以下 1 桁まで記載する。 楕円補正と同時に使用することは不可。	省略可
変動補正数	小数点形式、mm 単位とし、mm 以下 1 桁まで記載する。 地盤沈下調査は省略不可。	省略可
観測高低差結果	小数点形式、m 単位とし、m 以下 4 桁まで記載する。地盤沈下調査は省略不可。	省略可
備考	桁数の制限はしない。	省略可

10）観測点データ

P06 ， 水準点番号，観測標高，楕円補正，単路線閉合差補正，結果，与点・求点の別，備考，CRLF

P06	共通情報を示すデータ区分。	省略不可
水準点番号	P05 で使用されている名称を使用する。	省略不可
観測標高	小数点形式、m 単位とし、m 以下 4 桁まで記載する。	省略不可
楕円補正	小数点形式、mm 単位とし、mm 以下 1 桁まで記載する。 正標高補正数と同時に使用することは不可。	省略可
単路線閉合差補正	小数点形式、mm 単位とし、mm 以下 1 桁まで記載する。	省略可
結果	小数点形式、m 単位とし、m 以下 4 桁まで記載する。	省略不可
与点・求点の別	0：求点、1：与点	省略不可
備考	桁数の制限はしない。	省略可

P06 の重力補正は P05 に正標高補正数が追加されたので削除。

付 3-11

11）距離合計データ（距離合計を示すデータ）

P07 ， 距離合計，CRLF

P07	路線距離合計を示すデータ区分。	省略不可
距離合計	小数点形式、km 単位とし、km 以下 3 桁まで記載する。	省略不可

12）距離累計データ（距離累計を示すデータ）

P08 ， 距離累計，CRLF

P08	路線距離累計を示すデータ区分。	省略不可
距離累計	小数点形式、km 単位とし、km 以下 3 桁まで記載する。	省略不可

13）出力終了データ（終了を示すデータ）

P99 ， CRLF

改定（令和７年 12 月）		現行（令和６年３月）
P99　観測成果表データの出力終了を示すデータ区分。　省略不可		P99　観測成果表データの出力終了を示すデータ区分。　省略不可
※データ構造について P01～P07 のデータは下の構造体を一組とし、必要な路線数分だけ出力される。 Z00 Z01 Z03 P00 P01 P02 P03 P05(測線数分) P06(測点数分) P07 P04 P01 P02 P03 P05(測線数分) P06(測点数分) P07 P04 P01 P02 P03 P05(測線数分) P06(測点数分) P07 P04 P08 P99		※データ構造について P01～P07 のデータは下の構造体を一組とし、必要な路線数分だけ出力される。 Z00 Z01 Z03 P00 P01 P02 P03 P05(測線数分) P06(測点数分) P07 P04 P01 P02 P03 P05(測線数分) P06(測点数分) P07 P04 P01 P02 P03 P05(測線数分) P06(測点数分) P07 P04 P08 P99
付 3-13 出力例 Z00,SEIKA,4,02.00, Z01,令和 7 年度 1 級水準測量, Z03,202, P00,	変更 変更	付 3-12 出力例 Z00,SEIKA,4,02.00, Z01,令和 2 年度 1 級水準測量, Z03,2020 年度観測成果, P00,

改定（令和７年 12 月）		現行（令和６年３月）
P01,1,		P01,1,
P02,BM.1,BM.2,○○県○○郡○○町，○○県○○郡○○町,		P02,BM.1,BM.2,○○県○○郡○○町，○○県○○郡○○町,
P03,観測者,測器○○,NO.12345,標尺○○,NO.1234A･B,0.89,1.7,		P03,観測者,測器○○,NO.12345,標尺○○,NO.1234A･B,0.89,1.7,
P05,BM.1,41,1.300,34,4.5476,-4.5464,8,0.0,4.5470,2026-01-28,,,,,	変更	P05,BM.1,41,1.300,34,4.5476,-4.5464,8,0.0,4.5470,1/28,,,,,
P05,41,BM.2,1.206,32,-8.5199,8.5189,6,0.0,-8.5194, 2026-01-28,,,,,	変更	P05,41,BM.2,1.206,32,-8.5199,8.5189,6,0.0,-8.5194,1/28,,,,,
P06,BM.1,5.1245,,,5.1245,1,,	削除	P06,BM.1,5.1245,,,5.1245,1,測地成果 2011,
P06,41,9.6715,0.0,,9.6715,0,,		P06,41,9.6715,0.0,,9.6715,0,,
P06,BM.2,1.1521,0.0,,1.1521,1,,		P06,BM.2,1.1521,0.0,,1.1521,1,,
P07,2.506,		P07,2.506,
P04,		P04,
P01,2,		P01,2,
P02,BM.2,42,○○県○○郡○○町，○○県○○郡○○町,		P02,BM.2,42,○○県○○郡○○町，○○県○○郡○○町,
P03,観測者,測器○○,NO.12345,標尺○○,NO.1234A･B,0.89,1.7,		P03,観測者,測器○○,NO.12345,標尺○○,NO.1234A･B,0.89,1.7,
P05,BM.2,43,1.365,34,3.1216,-3.1206,9,0.0,3.1211, 2026-01-29,,,,,	変更	P05,BM.2,43,1.365,34,3.1216,-3.1206,9,0.0,3.1211,1/29,,,,,
P05,43,42,1.005,28,-2.2469,2.2453,11,0.0,-2.2461, 2026-01-28,,,,,	変更	P05,43,42,1.005,28,-2.2469,2.2453,11,0.0,-2.2461,1/28,,,,,
P06,BM.2,1.1515,,,1.1515,1,,	削除	P06,BM.2,1.1515,,,1.1515,1,測地成果 2011,
P06,43,4.2726,0.0,,,4.2726,0,,		P06,43,4.2726,0.0,,,4.2726,0,,
P06,42,2.0265,0.0,,,2.0265,0,,		P06,42,2.0265,0.0,,,2.0265,0,,
P07,2.370,		P07,2.370,
P04,		P04,
P01,3,		P01,3,
P02,42,BM.1,○○県○○郡○○町，○○県○○郡○○町,		P02,42,BM.1,○○県○○郡○○町，○○県○○郡○○町,
P03,観測者,測器○○,NO.12345,標尺○○,NO.1234A･B,0.89,1.7,		P03,観測者,測器○○,NO.12345,標尺○○,NO.1234A･B,0.89,1.7,
P05,42,BM.1,1.405,36,3.0973,-3.0967,8,0.0,3.0970, 2026-01-30,,,,,	変更	P05,42,BM.1,1.405,36,3.0973,-3.0967,8,0.0,3.0970,1/30,,,,,
P06,42,2.0265,,,2.0265,0,,		P06,42,2.0265,,,2.0265,0,,
P06,BM.1,5.1235,0.0,,,5.1235,0,1,,		P06,BM.1,5.1235,0.0,,,5.1235,0,1,,
P07,1.405,		P07,1.405,
P04,		P04,
P01,4,		P01,4,
P02,BM.2, BM.3,○○県○○郡○○町，○○県○○郡○○町,		P02,BM.2, BM.3,○○県○○郡○○町，○○県○○郡○○町,
P03,観測者,測器○○,NO.12345,標尺○○,NO.1234A･B,0.89,1.7,		P03,観測者,測器○○,NO.12345,標尺○○,NO.1234A･B,0.89,1.7,
P05,BM.2,44,1.023,28,6.4706,-6.4716,8,0.0,6.4711, 2026-01-30,,,,,	変更	P05,BM.2,44,1.023,28,6.4706,-6.4716,8,0.0,6.4711,1/30,,,,,
P05,44,45,1.102,26,-3.0899,3.0891,7,0.0,-3.0895, 2026-01-31,,,,,	変更	P05,44,45,1.102,26,-3.0899,3.0891,7,0.0,-3.0895,1/31,,,,,
P05,45,BM.3,1.082,26,-2.5430,2.5434,5,0.0,-2.5432, 2026-01-31,,,,,	変更	P05,45,BM.3,1.082,26,-2.5430,2.5434,5,0.0,-2.5432,1/31,,,,,
P06,BM.2,1.1515,,,1.1515,1,,	削除	P06,BM.2,1.1515,,,1.1515,1,測地成果 2011,
P06,44,7.6226,0.0,,7.6226,0,,		P06,44,7.6226,0.0,,7.6226,0,,
P06,45,4.5331,0.0,,4.5331,0,,		P06,45,4.5331,0.0,,4.5331,0,,
P06,BM.3,1.9899,0.0,,1.9899,1,,		P06,BM.3,1.9899,0.0,,1.9899,1,,
P07,3.207,		P07,3.207,

改定（令和７年 12 月）		現行（令和６年３月）
P04, P01,5, P02,BM.3, 42,○○県○○郡○○町, ○○県○○郡○○町, P03,観測者,測器○○,NO.12345,標尺○○,NO.1234A･B,0.89,1.7, P05,BM.3,42,1.395,40,0.0375,-0.0387,4,0.0,0.0381, 2026-01-31,,,,, P06,BM.3,1.9890,,,1.9890,1,, P065,42,2.0271,0.0,,2.0271,0,, P07,1.395, P04, P08,10.883, P99,	変更 削除	P04, P01,5, P02,BM.3, 42,○○県○○郡○○町, ○○県○○郡○○町, P03,観測者,測器○○,NO.12345,標尺○○,NO.1234A･B,0.89,1.7, P05,BM.3,42,1.395,40,0.0375,-0.0387,4,0.0,0.0381,1/31,,,,, P06,BM.3,1.9890,,,1.9890,1, 測地成果 2011, P065,42,2.0271,0.0,,2.0271,0,, P07,1.395, P04, P08,10.883, P99,

改定（令和７年 12 月）		現行（令和６年３月）
2.　地形測量及び写真測量成果表数値フォーマット		2.　地形測量及び写真測量成果表数値フォーマット
（1）　標定点成果表フォーマット		（1）　標定点成果表フォーマット
付 3-14 ● 出力する座標系は、数学座標系を標準とする。 ● 標定点成果表／簡易水準成果のファイル仕様は、1 行 1 レコードのテキストファイルとする。 ● 文字コードは UTF-8（BOM 付）を原則とする。 ● 各データの項目は、スペース又はタブによって区切るものとする。 ● レコード記述方法は、次のとおりである。 情報の順番　：点名、分類、X、Y、H、対標高 点名　：日本語(UTF-8 を原則とする) 分類　：本点のみ(0)、本点対標(1)、対標点(2)、刺針点(3～5)、簡易水準点(6) X　：実数（m 単位）、平面直角座標系 Y　：実数（m 単位）、平面直角座標系 H　：実数（m 単位）、平面直角座標系 対標高 ：実数（m 単位）、本点のみの場合は空白 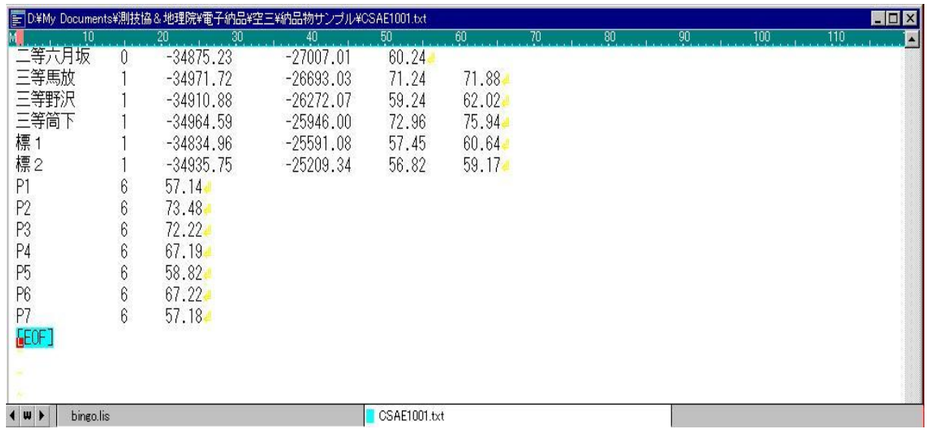 D:¥My Documents¥測技協＆地理院¥電子納品¥空三¥納品物サンプル¥CSAE1001.txt 二等六月坂　0　-34875.23　-27007.01　60.24 三等馬放　1　-34971.72　-26693.03　71.24　71.88 三等野沢　1　-34910.88　-26272.07　59.24　62.02 三等筒下　1　-34964.59　-25946.00　72.96　75.94 標１　1　-34834.96　-25591.08　57.45　60.64 標２　1　-34935.75　-25209.34　56.82　59.17 P1　6　57.14 P2　6　73.48 P3　6　72.22 P4　6　67.19 P5　6　58.82 P6　6　67.22 P7　6　57.18 [EOF] bingo.lis　CSAE1001.txt	変更 変更	付 3-13 ● 出力する座標系は、数学座標系を標準とする。 ● 標定点成果表／簡易水準成果のファイル仕様は、1 行 1 レコードのテキストファイルとする。 ● 文字コードは ASCII コード、漢字コードはシフト JIS コードとする。 ● 各データの項目は、スペース又はタブによって区切るものとする。 ● レコード記述方法は、次のとおりである。 情報の順番　：点名、分類、X、Y、H、対標高 点名　：日本語(Shift JIS) 分類　：本点のみ(0)、本点対標(1)、対標点(2)、刺針点(3～5)、簡易水準点(6) X　：実数（m 単位）、平面直角座標系 Y　：実数（m 単位）、平面直角座標系 H　：実数（m 単位）、平面直角座標系 対標高 ：実数（m 単位）、本点のみの場合は空白 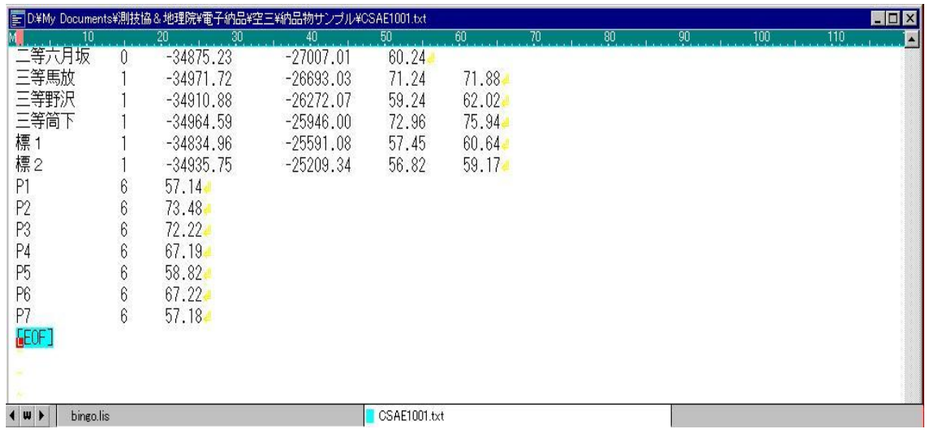 D:¥My Documents¥測技協＆地理院¥電子納品¥空三¥納品物サンプル¥CSAE1001.txt 二等六月坂　0　-34875.23　-27007.01　60.24 三等馬放　1　-34971.72　-26693.03　71.24　71.88 三等野沢　1　-34910.88　-26272.07　59.24　62.02 三等筒下　1　-34964.59　-25946.00　72.96　75.94 標１　1　-34834.96　-25591.08　57.45　60.64 標２　1　-34935.75　-25209.34　56.82　59.17 P1　6　57.14 P2　6　73.48 P3　6　72.22 P4　6　67.19 P5　6　58.82 P6　6　67.22 P7　6　57.18 [EOF] bingo.lis　CSAE1001.txt

改定（令和７年 12 月）		現行（令和６年３月）
（2）　外部標定要素成果表(GNSS/IMU 解析結果)		（2）　外部標定要素成果表(GNSS/IMU 解析結果)
付 3-14 ● 外部標定要素成果表(GNSS/IMU 解析結果)フォーマットは、1 行 1 レコードのテキストファイルとする。 ● 文字コードは、ASCII コードとする。 ● データの項目は、スペース又はタブによって区切るものとする。 ● 外部標定要素成果表(GNSS/IMU 解析結果）は、必須項目を含む関連データをフリーフォーマットで記述する。必須項目は、次のとおりである。 PHOTO ：写真番号、GNSS 時間、主点位置 X0、Y0、Z0、ω、φ、κ ● 位置の単位は m を標準とする。 ● 出力する座標系は数学座標系を標準とする。 付 3-15 ● 角度（ω,φ,κ）は、「(3)外部標定要素成果表フォーマット」に示す座標軸の回転順で、単位は度として、小数点以下 5 桁とする。		付 3-13 ● 外部標定要素成果表(GNSS/IMU 解析結果)フォーマットは、1 行 1 レコードのテキストファイルとする。 ● 文字コードは、ASCII コードとする。 ● データの項目は、スペース又はタブによって区切るものとする。 ● 外部標定要素成果表(GNSS/IMU 解析結果）は、必須項目を含む関連データをフリーフォーマットで記述する。必須項目は、次のとおりである。 PHOTO ：写真番号、GNSS 時間、主点位置 X0、Y0、Z0、ω、φ、κ ● 位置の単位は m を標準とする。 ● 出力する座標系は数学座標系を標準とする。 付 3-14 ● 角度（ω,φ,κ）は、「(3)外部標定要素成果表フォーマット」に示す座標軸の回転順で、単位は度として、小数点以下 5 桁とする。
（3）　外部標定要素成果表フォーマット		（3）　外部標定要素成果表フォーマット
付 3-15 ● 外部標定要素成果表フォーマットは、1 行 1 レコードのテキストファイルとする。 ● 文字コードは、ASCII コードとする。 ● データの項目は、スペース又はタブによって区切るものとする。 ● レコード記述方法は、データ区分を用いて、地上座標(POINT)と外部標定要素(PHOTO)をひとつのファイルに記述する。データの範囲は、別のデータ区分が出現するか、ファイルが終了するまでとする。 ● 外部標定要素成果表は、必須項目を含む関連データをフリーフォーマットで記述する。必須項目は、次のとおりである。 POINT　：点番号、調整後の座標 X,Y,Z PHOTO ：写真番号、主点位置 X0、Y0、Z0、ω、φ、κ ● 位置の単位は m を標準とする。 ● 出力する座標系は数学座標系を標準とする。 ● 角度（ω,φ,κ）は次に示す座標軸の回転順で、単位は度として、小数点以下 5 桁とする。 a)　回転順番と座標系との関係式 $\begin{pmatrix} x \\ y \\ z \end{pmatrix} = \begin{pmatrix} \cos\kappa & \sin\kappa & 0 \\ -\sin\kappa & \cos\kappa & 0 \\ 0 & 0 & 1 \end{pmatrix} \begin{pmatrix} \cos\varphi & 0 & -\sin\varphi \\ 0 & 1 & 0 \\ \sin\varphi & 0 & \cos\varphi \end{pmatrix} \begin{pmatrix} 1 & 0 & 0 \\ 0 & \cos\omega & \sin\omega \\ 0 & -\sin\omega & \cos\omega \end{pmatrix} \begin{pmatrix} X - Xo \\ Y - Yo \\ Z - Zo \end{pmatrix}$		付 3-14 ● 外部標定要素成果表フォーマットは、1 行 1 レコードのテキストファイルとする。 ● 文字コードは、ASCII コードとする。 ● データの項目は、スペース又はタブによって区切るものとする。 ● レコード記述方法は、データ区分を用いて、地上座標(POINT)と外部標定要素(PHOTO)をひとつのファイルに記述する。データの範囲は、別のデータ区分が出現するか、ファイルが終了するまでとする。 ● 外部標定要素成果表は、必須項目を含む関連データをフリーフォーマットで記述する。必須項目は、次のとおりである。 POINT　：点番号、調整後の座標 X,Y,Z PHOTO ：写真番号、主点位置 X0、Y0、Z0、ω、φ、κ ● 位置の単位は m を標準とする。 ● 出力する座標系は数学座標系を標準とする。 ● 角度（ω,φ,κ）は次に示す座標軸の回転順で、単位は度として、小数点以下 5 桁とする。 a)　回転順番と座標系との関係式 $\begin{pmatrix} x \\ y \\ z \end{pmatrix} = \begin{pmatrix} \cos\kappa & \sin\kappa & 0 \\ -\sin\kappa & \cos\kappa & 0 \\ 0 & 0 & 1 \end{pmatrix} \begin{pmatrix} \cos\varphi & 0 & -\sin\varphi \\ 0 & 1 & 0 \\ \sin\varphi & 0 & \cos\varphi \end{pmatrix} \begin{pmatrix} 1 & 0 & 0 \\ 0 & \cos\omega & \sin\omega \\ 0 & -\sin\omega & \cos\omega \end{pmatrix} \begin{pmatrix} X - Xo \\ Y - Yo \\ Z - Zo \end{pmatrix}$

改定（令和７年 12 月）

b)　カメラ座標系と地上座標系の関係図

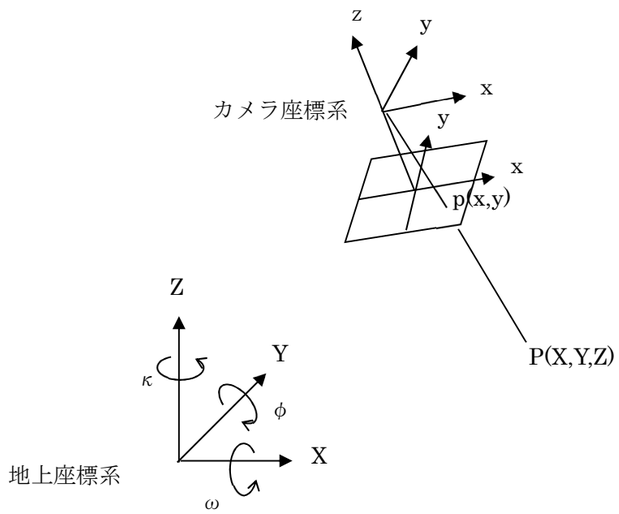

付 3-16

POINT 必須項目

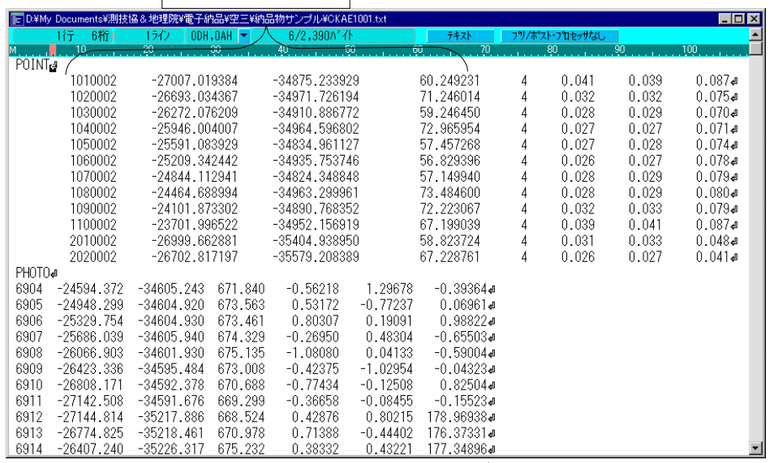

```
D:¥My Documents¥測技協＆地理院¥電子納品¥空三¥納品物サンプル¥CKAE1001.txt
1行　6桁　1ライン　0DH,0AH　6/2,390ﾊﾞｲﾄ　ﾃｷｽﾄ　ﾌﾘｰﾎﾟｽﾄ･ﾌﾟﾛｾｯｻなし
POINT
1010002   -27007.019384   -34875.233929   60.249231   4   0.041   0.039   0.087
1020002   -26693.034367   -34971.726194   71.246014   4   0.032   0.032   0.075
1030002   -26272.076209   -34910.886772   59.246450   4   0.028   0.029   0.070
1040002   -25946.004007   -34964.596802   72.965954   4   0.027   0.027   0.071
1050002   -25591.083929   -34834.961127   57.457268   4   0.027   0.028   0.074
1060002   -25209.342442   -34935.753746   56.829396   4   0.026   0.027   0.078
1070002   -24844.112941   -34824.348848   57.149940   4   0.028   0.029   0.079
1080002   -24464.688994   -34963.299961   73.484600   4   0.028   0.029   0.080
1090002   -24101.873302   -34890.768352   72.223067   4   0.032   0.033   0.079
1100002   -23701.996522   -34952.156919   67.199039   4   0.039   0.041   0.087
2010002   -26999.662881   -35404.938950   58.823724   4   0.031   0.033   0.048
2020002   -26702.817197   -35579.208389   67.228761   4   0.026   0.027   0.041
PHOTO
6904  -24594.372  -34605.243  671.840  -0.56218   1.29678  -0.39364
6905  -24948.299  -34604.920  673.563   0.53172  -0.77237   0.06961
6906  -25329.754  -34604.930  673.461   0.80307   0.19091   0.98822
6907  -25686.039  -34605.940  674.329  -0.26950   0.48304  -0.65503
6908  -26066.903  -34601.930  675.135  -1.08080   0.04133  -0.59004
6909  -26423.336  -34595.484  673.008  -0.42375  -1.02954  -0.04323
6910  -26808.171  -34592.378  670.688  -0.77434  -0.12508   0.82504
6911  -27142.508  -34591.676  669.299  -0.36658  -0.08455  -0.15523
6912  -27144.814  -35217.886  668.524   0.42876   0.80215 178.96938
6913  -26774.825  -35218.461  670.978   0.71388  -0.44402 176.37331
6914  -26407.240  -35226.317  675.232   0.38332   0.43221 177.34896
```

PHOTO 必須項目

現行（令和６年３月）

b)　カメラ座標系と地上座標系の関係図

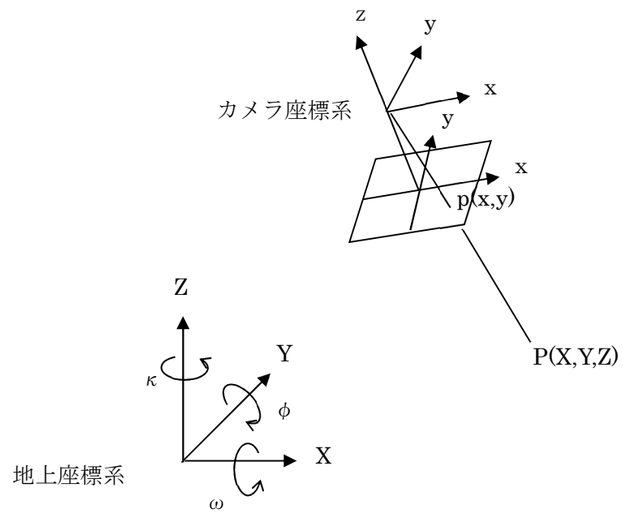

付 3-15

POINT 必須項目

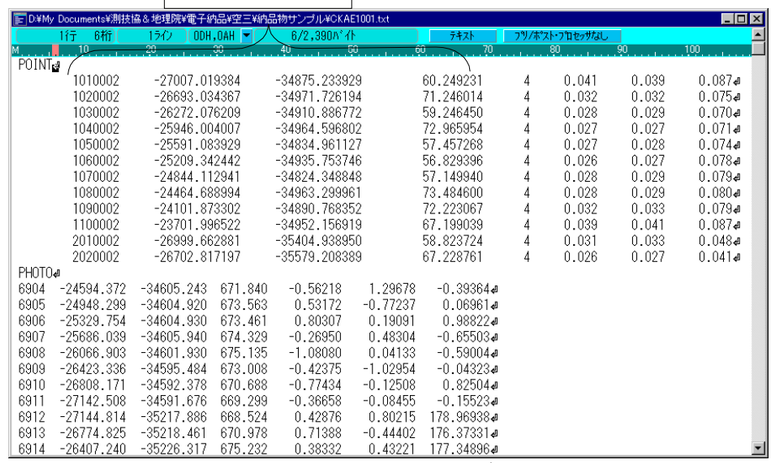

```
D:¥My Documents¥測技協＆地理院¥電子納品¥空三¥納品物サンプル¥CKAE1001.txt
1行　6桁　1ライン　0DH,0AH　6/2,390ﾊﾞｲﾄ　ﾃｷｽﾄ　ﾌﾘｰﾎﾟｽﾄ･ﾌﾟﾛｾｯｻなし
POINT
1010002   -27007.019384   -34875.233929   60.249231   4   0.041   0.039   0.087
1020002   -26693.034367   -34971.726194   71.246014   4   0.032   0.032   0.075
1030002   -26272.076209   -34910.886772   59.246450   4   0.028   0.029   0.070
1040002   -25946.004007   -34964.596802   72.965954   4   0.027   0.027   0.071
1050002   -25591.083929   -34834.961127   57.457268   4   0.027   0.028   0.074
1060002   -25209.342442   -34935.753746   56.829396   4   0.026   0.027   0.078
1070002   -24844.112941   -34824.348848   57.149940   4   0.028   0.029   0.079
1080002   -24464.688994   -34963.299961   73.484600   4   0.028   0.029   0.080
1090002   -24101.873302   -34890.768352   72.223067   4   0.032   0.033   0.079
1100002   -23701.996522   -34952.156919   67.199039   4   0.039   0.041   0.087
2010002   -26999.662881   -35404.938950   58.823724   4   0.031   0.033   0.048
2020002   -26702.817197   -35579.208389   67.228761   4   0.026   0.027   0.041
PHOTO
6904  -24594.372  -34605.243  671.840  -0.56218   1.29678  -0.39364
6905  -24948.299  -34604.920  673.563   0.53172  -0.77237   0.06961
6906  -25329.754  -34604.930  673.461   0.80307   0.19091   0.98822
6907  -25686.039  -34605.940  674.329  -0.26950   0.48304  -0.65503
6908  -26066.903  -34601.930  675.135  -1.08080   0.04133  -0.59004
6909  -26423.336  -34595.484  673.008  -0.42375  -1.02954  -0.04323
6910  -26808.171  -34592.378  670.688  -0.77434  -0.12508   0.82504
6911  -27142.508  -34591.676  669.299  -0.36658  -0.08455  -0.15523
6912  -27144.814  -35217.886  668.524   0.42876   0.80215 178.96938
6913  -26774.825  -35218.461  670.978   0.71388  -0.44402 176.37331
6914  -26407.240  -35226.317  675.232   0.38332   0.43221 177.34896
```

PHOTO 必須項目

改定（令和７年 12 月）		現行（令和６年３月）
（4）　写真座標測定簿フォーマット		（4）　写真座標測定簿フォーマット
付 3-17 ● 写真座標測定簿フォーマットは、1 行 1 レコードのテキストファイルとする。 ● 文字コードは、ASCII コードとする。 ● データの項目は、スペース又はタブによって区切るものとする。 ● レコード記述方法は、基本情報、指標観測座標、観測座標、終了番号を写真枚数分、繰り返し記載する。 ● 焦点距離及び座標の単位は、mm もしくは μm とし、同一とする。 ● 出力する座標系は、数学座標系を標準とする。 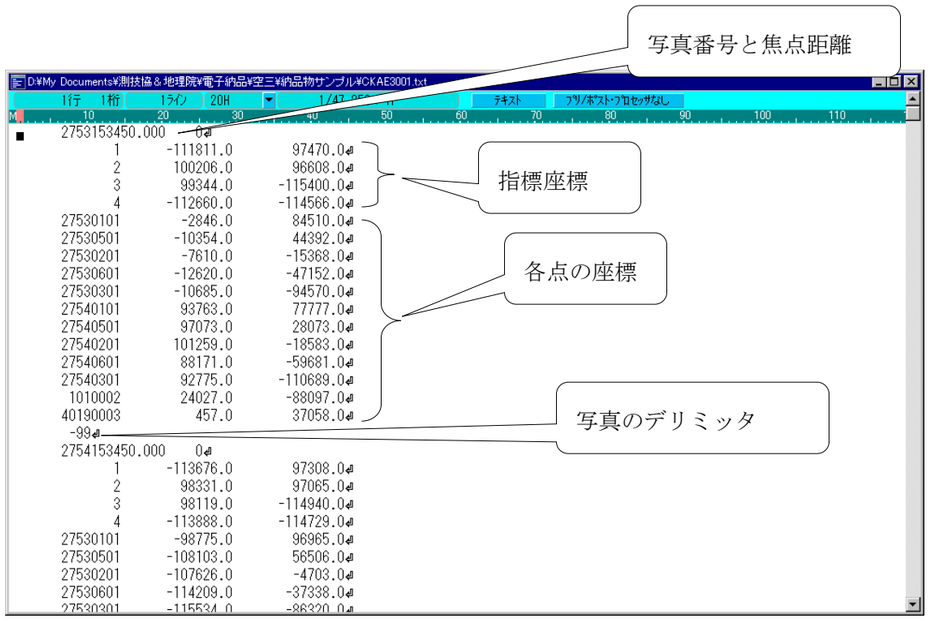 	付 3-16 ● 写真座標測定簿フォーマットは、1 行 1 レコードのテキストファイルとする。 ● 文字コードは、ASCII コードとする。 ● データの項目は、スペース又はタブによって区切るものとする。 ● レコード記述方法は、基本情報、指標観測座標、観測座標、終了番号を写真枚数分、繰り返し記載する。 ● 焦点距離及び座標の単位は、mm もしくは μm とし、同一とする。 ● 出力する座標系は、数学座標系を標準とする。 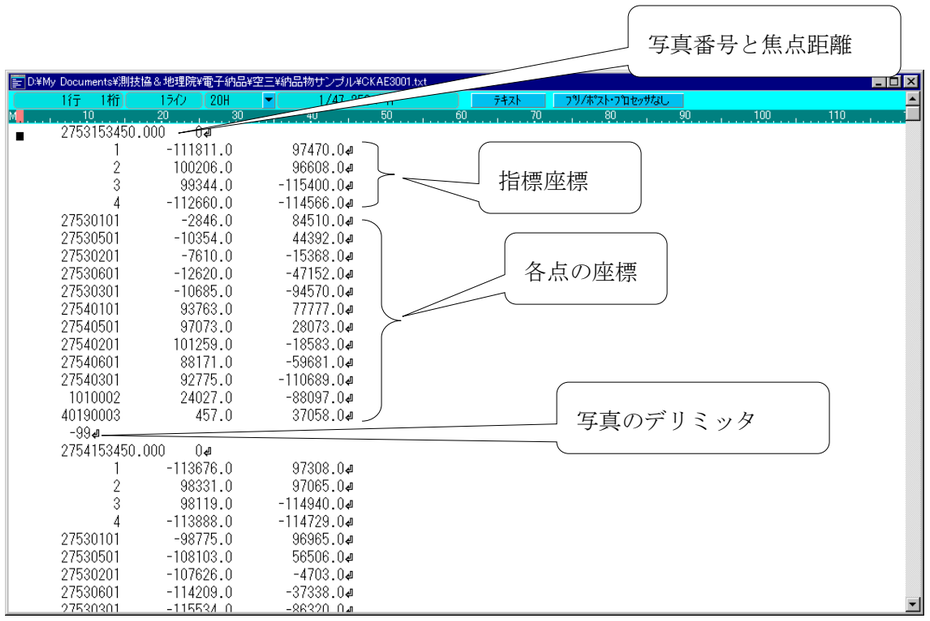
（5）　調整計算簿フォーマット		（5）　調整計算簿フォーマット
付 3-17 ● 調整計算簿フォーマットは、1 行 1 レコードのテキストファイルとする。 ● 文字コードは、ASCII コードとする。 ● レコード記述方法は、フリーフォーマットとし、使用した同時調整プログラムの出力形式でよい。 ● 計算後の内容は、採用した調整法、同時調整タイポイント較差表、パスポイント及びタイポイント残差一覧表（独立モデル法）、交会残差一覧表（バンドル法、セルフキャリブレーション付きバンドル法）によって異なる。 ● 座標の単位は、使用したソフトウェアの仕様に準じる。 ● 出力する座標系は、数学座標系を標準とする。		付 3-16 ● 調整計算簿フォーマットは、1 行 1 レコードのテキストファイルとする。 ● 文字コードは、ASCII コードとする。 ● レコード記述方法は、フリーフォーマットとし、使用した同時調整プログラムの出力形式でよい。 ● 計算後の内容は、採用した調整法、同時調整タイポイント較差表、パスポイント及びタイポイント残差一覧表（独立モデル法）、交会残差一覧表（バンドル法、セルフキャリブレーション付きバンドル法）によって異なる。 ● 座標の単位は、使用したソフトウェアの仕様に準じる。 ● 出力する座標系は、数学座標系を標準とする。

改定（令和７年 12 月）		現行（令和６年３月）
付 3-18		付 3-17

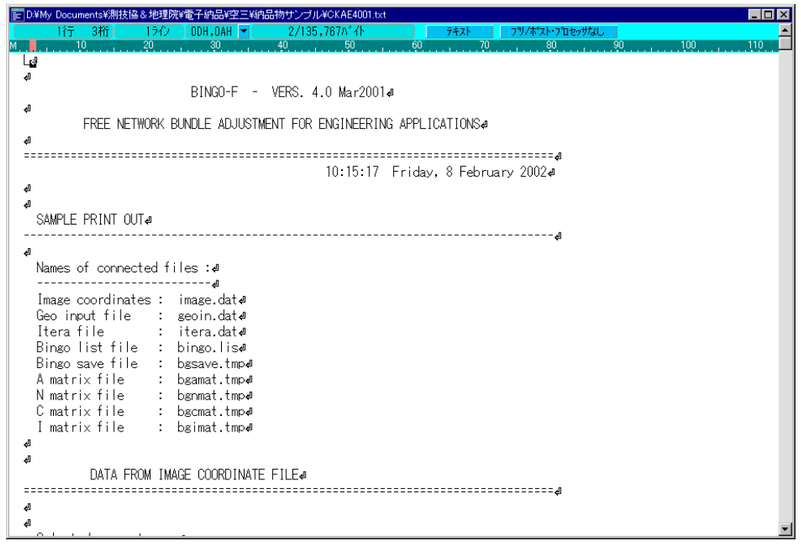

```
D:¥My Documents¥測技協＆地理院¥電子納品¥空三¥納品物サンプル¥CKAE4001.txt
1行  3桁  1ライン  ODH.OAH  2/135,767ﾊﾞｲﾄ  テキスト  フリ/ポスト-プロセッサなし

                    BINGO-F  -  VERS. 4.0 Mar2001

        FREE NETWORK BUNDLE ADJUSTMENT FOR ENGINEERING APPLICATIONS
==================================================================================
                                        10:15:17  Friday, 8 February 2002

 SAMPLE PRINT OUT
----------------------------------------------------------------------------------

  Names of connected files :
  -------------------------
  Image coordinates :  image.dat
  Geo input file    :  geoin.dat
  Itera file        :  itera.dat
  Bingo list file   :  bingo.lis
  Bingo save file   :  bgsave.tmp
  A matrix file     :  bgamat.tmp
  N matrix file     :  bgnmat.tmp
  C matrix file     :  bgcmat.tmp
  I matrix file     :  bgimat.tmp

          DATA FROM IMAGE COORDINATE FILE
==================================================================================
```

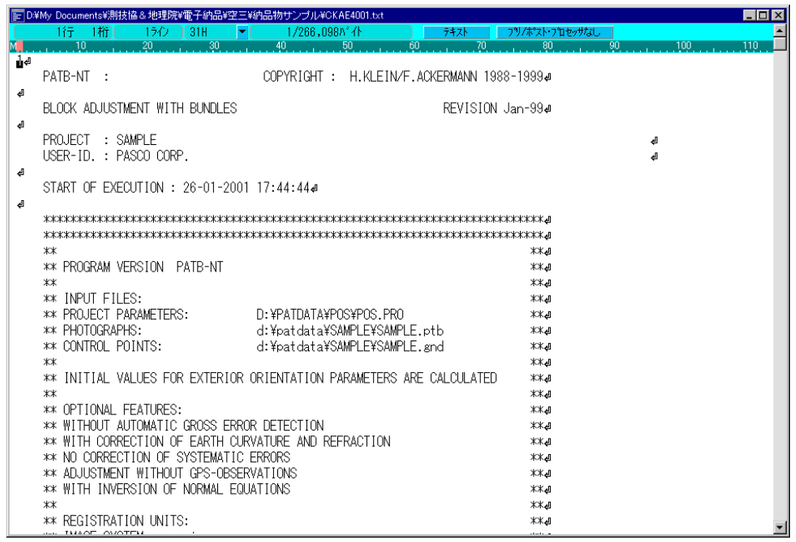

```
D:¥My Documents¥測技協＆地理院¥電子納品¥空三¥納品物サンプル¥CKAE4001.txt
1行  1桁  1ライン  31H  1/266,098ﾊﾞｲﾄ  テキスト  フリ/ポスト-プロセッサなし

   PATB-NT  :                    COPYRIGHT :  H.KLEIN/F.ACKERMANN 1988-1999

   BLOCK ADJUSTMENT WITH BUNDLES                          REVISION Jan-99

   PROJECT  : SAMPLE
   USER-ID. : PASCO CORP.

   START OF EXECUTION : 26-01-2001 17:44:44

   ************************************************************************
   ************************************************************************
   **                                                                    **
   ** PROGRAM VERSION  PATB-NT                                           **
   **                                                                    **
   ** INPUT FILES:                                                       **
   ** PROJECT PARAMETERS:          D:¥PATDATA¥POS¥POS.PRO                **
   ** PHOTOGRAPHS:                 d:¥patdata¥SAMPLE¥SAMPLE.ptb          **
   ** CONTROL POINTS:              d:¥patdata¥SAMPLE¥SAMPLE.gnd          **
   **                                                                    **
   ** INITIAL VALUES FOR EXTERIOR ORIENTATION PARAMETERS ARE CALCULATED  **
   **                                                                    **
   ** OPTIONAL FEATURES:                                                 **
   ** WITHOUT AUTOMATIC GROSS ERROR DETECTION                            **
   ** WITH CORRECTION OF EARTH CURVATURE AND REFRACTION                  **
   ** NO CORRECTION OF SYSTEMATIC ERRORS                                 **
   ** ADJUSTMENT WITHOUT GPS-OBSERVATIONS                                **
   ** WITH INVERSION OF NORMAL EQUATIONS                                 **
   **                                                                    **
   ** REGISTRATION UNITS:                                                **
```

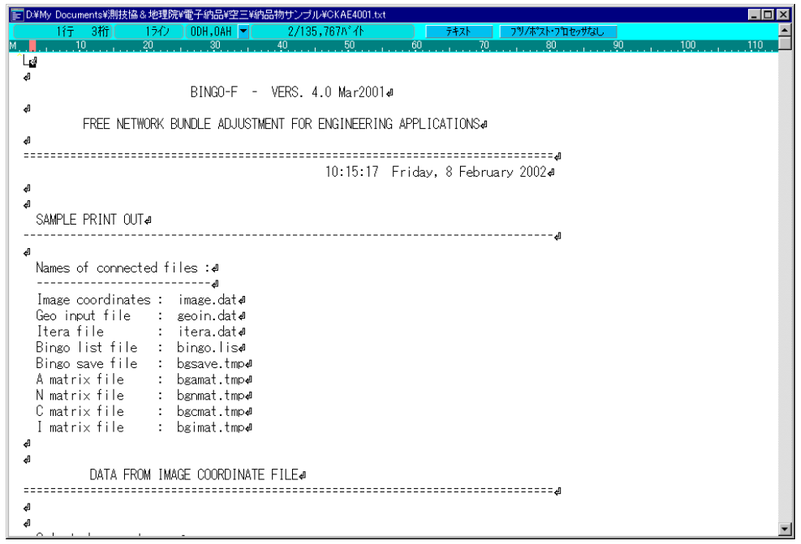

```
D:¥My Documents¥測技協＆地理院¥電子納品¥空三¥納品物サンプル¥CKAE4001.txt
1行  3桁  1ライン  ODH.OAH  2/135,767ﾊﾞｲﾄ  テキスト  フリ/ポスト-プロセッサなし

                    BINGO-F  -  VERS. 4.0 Mar2001

        FREE NETWORK BUNDLE ADJUSTMENT FOR ENGINEERING APPLICATIONS
==================================================================================
                                        10:15:17  Friday, 8 February 2002

 SAMPLE PRINT OUT
----------------------------------------------------------------------------------

  Names of connected files :
  -------------------------
  Image coordinates :  image.dat
  Geo input file    :  geoin.dat
  Itera file        :  itera.dat
  Bingo list file   :  bingo.lis
  Bingo save file   :  bgsave.tmp
  A matrix file     :  bgamat.tmp
  N matrix file     :  bgnmat.tmp
  C matrix file     :  bgcmat.tmp
  I matrix file     :  bgimat.tmp

          DATA FROM IMAGE COORDINATE FILE
==================================================================================
```

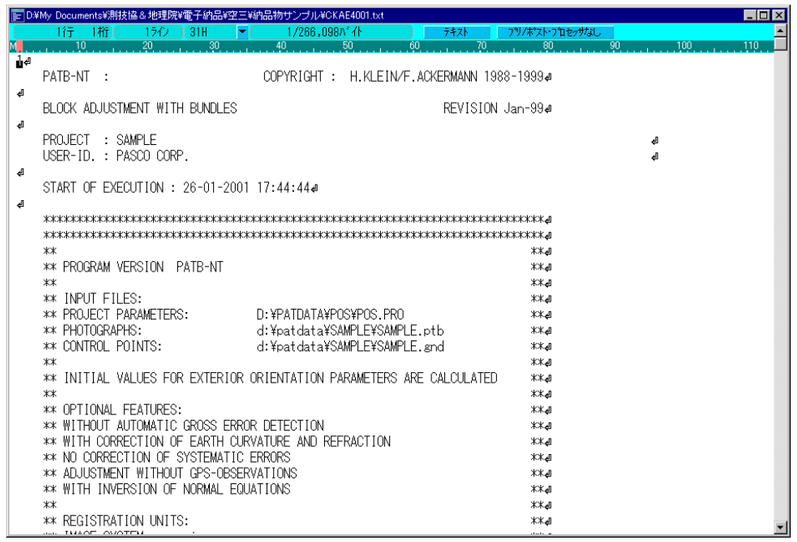

```
D:¥My Documents¥測技協＆地理院¥電子納品¥空三¥納品物サンプル¥CKAE4001.txt
1行  1桁  1ライン  31H  1/266,098ﾊﾞｲﾄ  テキスト  フリ/ポスト-プロセッサなし

   PATB-NT  :                    COPYRIGHT :  H.KLEIN/F.ACKERMANN 1988-1999

   BLOCK ADJUSTMENT WITH BUNDLES                          REVISION Jan-99

   PROJECT  : SAMPLE
   USER-ID. : PASCO CORP.

   START OF EXECUTION : 26-01-2001 17:44:44

   ************************************************************************
   ************************************************************************
   **                                                                    **
   ** PROGRAM VERSION  PATB-NT                                           **
   **                                                                    **
   ** INPUT FILES:                                                       **
   ** PROJECT PARAMETERS:          D:¥PATDATA¥POS¥POS.PRO                **
   ** PHOTOGRAPHS:                 d:¥patdata¥SAMPLE¥SAMPLE.ptb          **
   ** CONTROL POINTS:              d:¥patdata¥SAMPLE¥SAMPLE.gnd          **
   **                                                                    **
   ** INITIAL VALUES FOR EXTERIOR ORIENTATION PARAMETERS ARE CALCULATED  **
   **                                                                    **
   ** OPTIONAL FEATURES:                                                 **
   ** WITHOUT AUTOMATIC GROSS ERROR DETECTION                            **
   ** WITH CORRECTION OF EARTH CURVATURE AND REFRACTION                  **
   ** NO CORRECTION OF SYSTEMATIC ERRORS                                 **
   ** ADJUSTMENT WITHOUT GPS-OBSERVATIONS                                **
   ** WITH INVERSION OF NORMAL EQUATIONS                                 **
   **                                                                    **
   ** REGISTRATION UNITS:                                                **
```

改定（令和７年 12 月）		現行（令和６年３月）
3.　三次元点群測量成果表数値フォーマット		3.　三次元点群測量成果表数値フォーマット
（1）　標定点、調整点及び検証点成果表フォーマット		（1）　標定点、調整点及び検証点成果表フォーマット
付 3-19 ● 地形測量及び写真測量成果表数値フォーマットの「標定点成果表フォーマット」に準じる。		付 3-18 ● 地形測量及び写真測量成果表数値フォーマットの「標定点成果表フォーマット」に準じる。
（2）　オリジナルデータ		（2）　オリジナルデータ
付 3-19 ● 計測点の Id、x、y、z 座標及びパルス番号（ファースト、アザー及びラストパルス等に区分した番号）を１行に記述したカンマ区切り若しくは半角スペース区切りの TXT 形式、若しくは TXT 形式に変換可能な形式とする。 ● TXT 形式に変換可能な形式の場合の項目（アイテム）名は、x、y、z 座標及びパルス番号の各項目とする。 ● ファイル内に区域外が存在する場合、その位置のデータはデータ無しとして取り扱い、データを記録しない。 ● 出力する座標系は、数学座標系を標準とする。 ● テキストは半角英数字（英字は小文字）とする。 ● ファイル構造 Id1,x1,y1,z1,p1　Id：　ファイル内でユニークな一連番号 Id2,x2,y2,z2,p2　x1,y1：　計測点座標値（m 単位で、規定の位まで） ：　：　：　：　z1：　標高値（m 単位で、規定の位まで） ：　：　：　：　p1：　パルス番号 Idn,xn,yn,zn,pn		付 3-18 ● 計測点の Id、x、y、z 座標及びパルス番号（ファースト、アザー及びラストパルス等に区分した番号）を１行に記述したカンマ区切り若しくは半角スペース区切りの TXT 形式、若しくは TXT 形式に変換可能な形式とする。 ● TXT 形式に変換可能な形式の場合の項目（アイテム）名は、x、y、z 座標及びパルス番号の各項目とする。 ● ファイル内に区域外が存在する場合、その位置のデータはデータ無しとして取り扱い、データを記録しない。 ● 出力する座標系は、数学座標系を標準とする。 ● テキストは半角英数字（英字は小文字）とする。 ● ファイル構造 Id1,x1,y1,z1,p1　Id：　ファイル内でユニークな一連番号 Id2,x2,y2,z2,p2　x1,y1：　計測点座標値（m 単位で、規定の位まで） ：　：　：　：　z1：　標高値（m 単位で、規定の位まで） ：　：　：　：　p1：　パルス番号 Idn,xn,yn,zn,pn
（3）　グラウンドデータ		（3）　グラウンドデータ
付 3-19 ● 計測点の Id、x、y、z 座標を１行に記述したカンマ区切り又は半角スペース区切りの TXT 形式、若しくは TXT 形式に変換可能な形式とする。 ● TXT 形式に変換可能な形式の場合の項目（アイテム）名は、x、y、z 座標の各項目とする。 ● ファイル内に区域外が存在する場合、その場合のデータはデータ無しとして取り扱い、データを記録しない。 ● 出力する座標系は、数学座標系を標準とする。 ● テキストは半角英数字（英字は小文字）とする。 ● ファイル構造 Id1,x1,y1,z1　Id：　オリジナルファイルとグラウンドファイル同一番号 Id2,x2,y2,z2　x1,y1：　計測点座標値（m 単位で、規定の位まで） ：　：　：　：　z1：　標高値（m 単位で、規定の位まで）		付 3-18 ● 計測点の Id、x、y、z 座標を１行に記述したカンマ区切り又は半角スペース区切りの TXT 形式、若しくは TXT 形式に変換可能な形式とする。 ● TXT 形式に変換可能な形式の場合の項目（アイテム）名は、x、y、z 座標の各項目とする。 ● ファイル内に区域外が存在する場合、その場合のデータはデータ無しとして取り扱い、データを記録しない。 ● 出力する座標系は、数学座標系を標準とする。 ● テキストは半角英数字（英字は小文字）とする。 ● ファイル構造 Id1,x1,y1,z1　Id：　オリジナルファイルとグラウンドファイル同一番号 Id2,x2,y2,z2　x1,y1：　計測点座標値（m 単位で、規定の位まで） ：　：　：　：　z1：　標高値（m 単位で、規定の位まで）

改定（令和７年 12 月）		現行（令和６年３月）
：　：　：　： Idn,xn,yn,zn		：　：　：　： Idn,xn,yn,zn
（4）　グリッドデータ		（4）　グリッドデータ
付 3-20 ● 計測点の Id、x、y、z 座標及び地表面属性コードを１行に記述したカンマ区切り又は半角スペース区切りの TXT 形式、若しくは TXT 形式に変換可能な形式とする。 ● TXT 形式に変換可能な形式の場合の項目（アイテム）名は、x、y、z 座標及び地表面属性コードの各項目とする。 ● ファイル内に区域外が存在する場合、その場合のデータはデータ無しとして取り扱い、データを記録しない。 ● 出力する座標系は、数学座標系を標準とする。 ● テキストは半角英数字（英字は小文字）とする。 ● ファイル構造 Id1,x1,y1,z1,A1　　Id：　ファイル内でユニークな一連番号を左上で始点、右下を終点とし、行、列の順に昇順になるようにソートした。 Id2,x2,y2,z2,A2 ：　：　：　：　　x1,y1：　計測点座標値（m 単位で、規定の位まで） ：　：　：　：　　z1：　標高値（m 単位で、規定の位まで） ：　：　：　：　　A1：　航空レーザ測量の場合 ：　：　：　：　　地表面属性値、真=1、偽=0、水部=-9999 ：　：　：　：　　航空レーザ測深測量の場合 ：　：　：　：　　地表面属性値、真=1、偽=0 Idn,xn,yn,zn	追加 追加 追加	付 3-19 ● 計測点の Id、x、y、z 座標及び地表面属性コードを１行に記述したカンマ区切り又は半角スペース区切りの TXT 形式、若しくは TXT 形式に変換可能な形式とする。 ● TXT 形式に変換可能な形式の場合の項目（アイテム）名は、x、y、z 座標及び地表面属性コードの各項目とする。 ● ファイル内に区域外が存在する場合、その場合のデータはデータ無しとして取り扱い、データを記録しない。 ● 出力する座標系は、数学座標系を標準とする。 ● テキストは半角英数字（英字は小文字）とする。 ● ファイル構造 Id1,x1,y1,z1,A1　　Id：　ファイル内でユニークな一連番号を左上で始点、右下を終点とし、行、列の順に昇順になるようにソートした。 Id2,x2,y2,z2,A2 ：　：　：　：　　x1,y1：　計測点座標値（m 単位で、規定の位まで） ：　：　：　：　　z1：　標高値（m 単位で、規定の位まで） ：　：　：　：　　A1：　地表面属性値、真=1、偽=0、水部=-9999 Idn,xn,yn,zn

改定（令和７年 12 月）		現行（令和６年３月）
（5）　水部ポリゴンデータ、低密度ポリゴンデータ		（5）　水部ポリゴンデータ、低密度ポリゴンデータ
付 3-20 ● ポリゴンデータの座標を列記したカンマ区切り又は半角スペース区切りの TXT 形式、若しくは TXT 形式に変換可能な形式とする。 ● 出力する座標系は、数学座標系を標準とする。 ● テキストは半角英数字（英字は小文字）とする。 ● ファイル構造 Id1,x1,y1　Id,x1,y1：Id はユニークな一連番号とし、ラベル位置はポリゴン内の任意の場所 x1,y1　x1,y1：ポリゴンの始終点座標値（m 単位で小数点以下第 2 位まで） x2,y2 ：　： xn,yn x1,y1　x1,y1：ポリゴンの始終点座標値 end　：ポリゴン終了フラグ Id2,x1,y1　x1,y1：Id のラベル位置はポリゴン内の任意の場所 x1,y2 ：　： xn,yn x1,y1　x1,y1：ポリゴンの始終点座標値 end　：ポリゴン終了フラグ end　：ファイル終了フラグ 付 3-21 ● 島（穴）ポリゴンがあるポリゴンでは、当該ポリゴンのラベル位置は、当該ポリゴン内の島（穴）ポリゴン内を除いた任意の場所とし、島（穴）ポリゴンのラベル位置は島（穴）ポリゴン内の任意の場所とする。 ● ポリゴンデータと島（穴）ポリゴンのデータの順番は、連続しなくても良い。		付 3-19 ● ポリゴンデータの座標を列記したカンマ区切り又は半角スペース区切りの TXT 形式、若しくは TXT 形式に変換可能な形式とする。 ● 出力する座標系は、数学座標系を標準とする。 ● テキストは半角英数字（英字は小文字）とする。 ● ファイル構造 Id1,x1,y1　Id,x1,y1：Id はユニークな一連番号とし、ラベル位置はポリゴン内の任意の場所 x1,y1　x1,y1：ポリゴンの始終点座標値（m 単位で小数点以下第 2 位まで） x2,y2 ：　： xn,yn x1,y1　x1,y1：ポリゴンの始終点座標値 end　：ポリゴン終了フラグ Id2,x1,y1　x1,y1：Id のラベル位置はポリゴン内の任意の場所 x1,y2 ：　： xn,yn x1,y1　x1,y1：ポリゴンの始終点座標値 end　：ポリゴン終了フラグ end　：ファイル終了フラグ 付 3-20 ● 島（穴）ポリゴンがあるポリゴンでは、当該ポリゴンのラベル位置は、当該ポリゴン内の島（穴）ポリゴン内を除いた任意の場所とし、島（穴）ポリゴンのラベル位置は島（穴）ポリゴン内の任意の場所とする。 ● ポリゴンデータと島（穴）ポリゴンのデータの順番は、連続しなくても良い。

改定（令和７年 12 月）		現行（令和６年３月）
付属資料 4　CAD データ作成に当たっての留意点		**付属資料 4　CAD データ作成に当たっての留意点**
1.　ファイルフォーマット		1.　ファイルフォーマット
付 4-1 電子納品する CAD データファイルは、SXF(P21)形式もしくは SXF(P2Z)形式とする。また、SXF のバージョンとレベルは、SXF Ver.3.0 レベル 2 以上とする。 【解説】 SXF（Scadec data eXchange Format）は、STEP AP202（製品モデルとの関連を持つ図面）規格を実装した CAD データ交換標準である。これは、「CAD データ交換標準開発コンソーシアム（SCADEC）（平成 11 年 3 月～平成 12 年 8 月）」、「建設情報標準化委員会　CAD データ交換標準小委員会（平成 12 年 10 月～平成 19 年 6 月）」、「建設情報標準化委員会　図面/モデル情報交換小委員会（平成 19 年 7 月～平成 22 年 6 月）」（いずれも事務局は一般財団法人日本建設情報総合センター）にて策定されたもので、ISO TC184/SC4（STEP 規格を審議する国際会議）にて、STEP 規格を実装したものであることが認知されている。 SXF の物理ファイルには国際標準に則った「P21 形式」と国内 CAD データ交換のための簡易形式である「SFC 形式」の 2 種類がある。CAD 製図基準では、SXF(P21)形式のバージョンとレベルは、SXF Ver.2.0 レベル 2 以上を対象としている。 本要領では、属性ファイル用属性付加機構を利用して取得分類コード、精度、取得年月など標準図式データファイルに記述される情報を保持するため、SXF Ver.3.0 レベル 2 以上を採用する。 SXF(P2Z)形式については CAD 製図基準を参照。		付 4-1 電子納品する CAD データファイルは、SXF(P21)形式もしくは SXF(P2Z)形式とする。また、SXF のバージョンとレベルは、SXF Ver.3.0 レベル 2 以上とする。 【解説】 SXF（Scadec data eXchange Format）は、STEP AP202（製品モデルとの関連を持つ図面）規格を実装した CAD データ交換標準である。これは、「CAD データ交換標準開発コンソーシアム（SCADEC）（平成 11 年 3 月～平成 12 年 8 月）」、「建設情報標準化委員会　CAD データ交換標準小委員会（平成 12 年 10 月～平成 19 年 6 月）」、「建設情報標準化委員会　図面/モデル情報交換小委員会（平成 19 年 7 月～平成 22 年 6 月）」（いずれも事務局は一般財団法人日本建設情報総合センター）にて策定されたもので、ISO TC184/SC4（STEP 規格を審議する国際会議）にて、STEP 規格を実装したものであることが認知されている。 SXF の物理ファイルには国際標準に則った「P21 形式」と国内 CAD データ交換のための簡易形式である「SFC 形式」の 2 種類がある。CAD 製図基準では、SXF(P21)形式のバージョンとレベルは、SXF Ver.2.0 レベル 2 以上を対象としている。 本要領では、属性ファイル用属性付加機構を利用して取得分類コード、精度、取得年月など標準図式データファイルに記述される情報を保持するため、SXF Ver.3.0 レベル 2 以上を採用する。 SXF(P2Z)形式については CAD 製図基準を参照。
2.　格納フォルダ		2.　格納フォルダ
付 4-1 電子納品する CAD データファイルは、本要領「2 フォルダ構成」に従い、SURVEY フォルダ以下に格納する。 【解説】 CAD 製図基準では、CAD データは DRAWING フォルダに格納することを定めているが、測量作業では本要領「2 フォルダ構成」に従い、SURVEY フォルダ以下の測量区分、測量細区分フォルダに成果等を格納する。		付 4-1 電子納品する CAD データファイルは、本要領「2 フォルダ構成」に従い、SURVEY フォルダ以下に格納する。 【解説】 CAD 製図基準では、CAD データは DRAWING フォルダに格納することを定めているが、測量作業では本要領「2 フォルダ構成」に従い、SURVEY フォルダ以下の測量区分、測量細区分フォルダに成果等を格納する。

改定（令和７年 12 月）

3.　ファイル命名

付 4-1

電子納品する CAD データのファイル名は、本要領「5 ファイル命名規則」による。

【解説】

CAD 製図基準では、CAD データは、ライフサイクル、整理番号、図面種類、図面番号、改訂履歴の組合せで、ファイル命名を行うが、測量作業では本要領「5 ファイル命名規則」に従い、ファイル命名を行う。

付 4-2

CAD データは、SXF(P21)、SAF(SXF Ver.3.0 レベル 2 以上の機能を利用した場合に生成される属性ファイル)、ラスタファイルのデータセットから構成されるが、各ファイルの命名規則は、図 1、図 2、図 3 による。

対応する SXF(P21)、SAF ファイルは、拡張子を除き、同一のファイル名称とする。また、ラスタファイルについては、測量細区分の設定記号、成果種類の設定記号を対応する SXF(P21)ファイルと一致させる。

SXF(P21)のファイル中に記述されるラスタファイルの名称は、格納したラスタファイルの名称と必ず一致するように留意する。

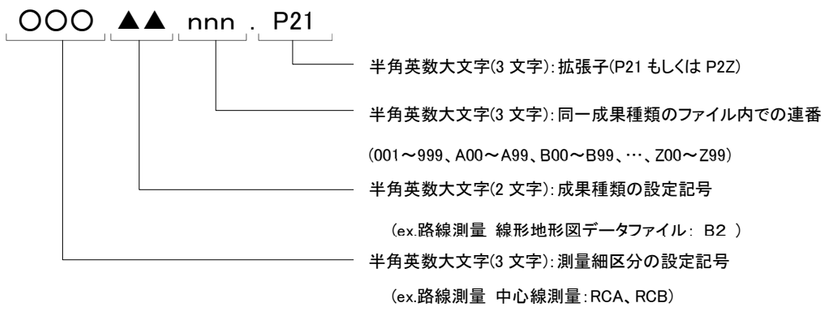

図 1　SXF(P21)ファイルの命名規則

現行（令和６年３月）

3.　ファイル命名

付 4-1

電子納品する CAD データのファイル名は、本要領「5 ファイル命名規則」による。

【解説】

CAD 製図基準では、CAD データは、ライフサイクル、整理番号、図面種類、図面番号、改訂履歴の組合せで、ファイル命名を行うが、測量作業では本要領「5 ファイル命名規則」に従い、ファイル命名を行う。

付 4-2

CAD データは、SXF(P21)、SAF(SXF Ver.3.0 レベル 2 以上の機能を利用した場合に生成される属性ファイル)、ラスタファイルのデータセットから構成されるが、各ファイルの命名規則は、図 1、図 2、図 3 による。

対応する SXF(P21)、SAF ファイルは、拡張子を除き、同一のファイル名称とする。また、ラスタファイルについては、測量細区分の設定記号、成果種類の設定記号を対応する SXF(P21)ファイルと一致させる。

SXF(P21)のファイル中に記述されるラスタファイルの名称は、格納したラスタファイルの名称と必ず一致するように留意する。

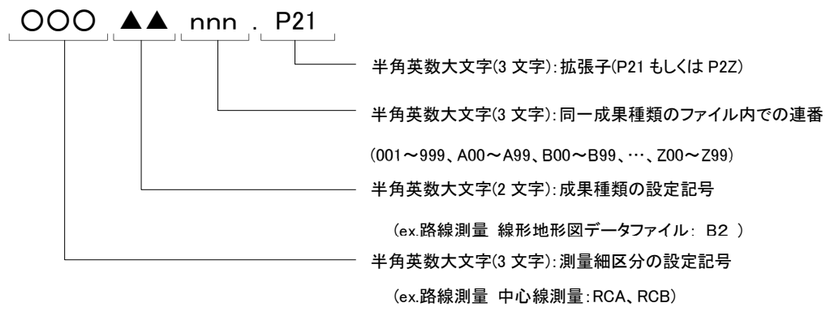

図 1　SXF(P21)ファイルの命名規則

改定（令和７年 12 月）

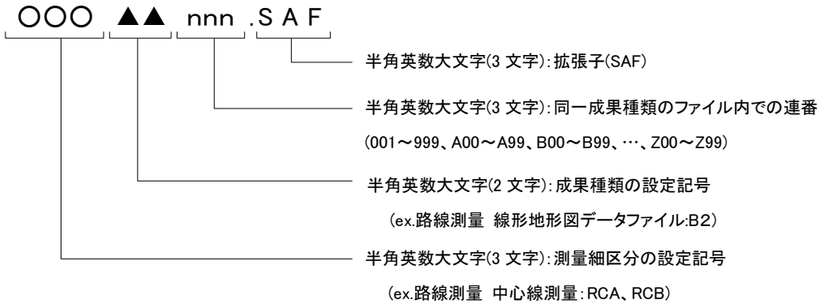

図 2　SAF ファイルの命名規則

付 4-3

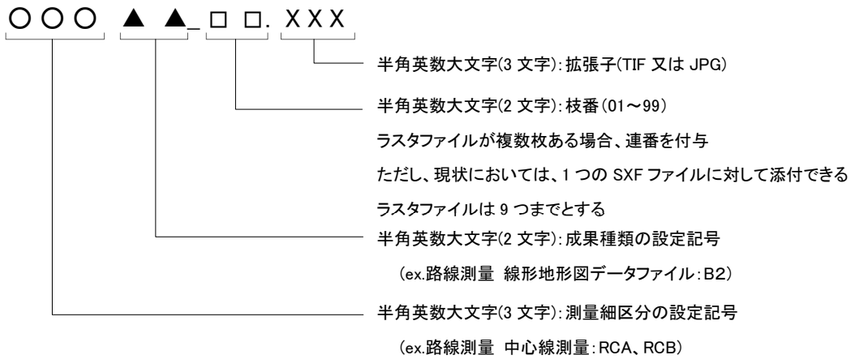

図 3　ラスタファイルの命名規則

現行（令和６年３月）

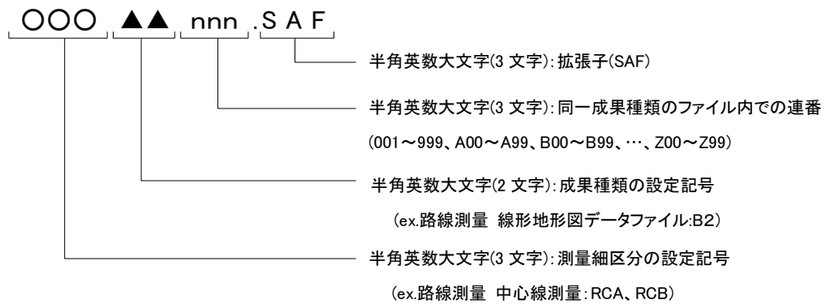

図 2　SAF ファイルの命名規則

付 4-3

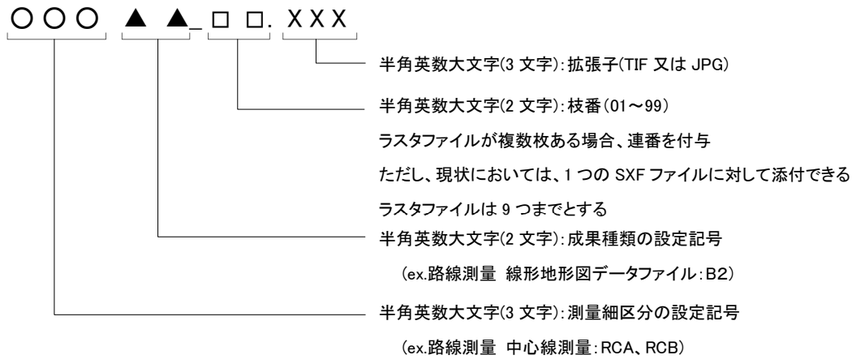

図 3　ラスタファイルの命名規則

改定（令和７年 12 月）

4.　　レイヤの名称

付 4-3

CAD データのレイヤ名は、表１による。

表 1　測量作業で作成する CAD データのレイヤ名

項目			取得分類		CAD データのレイヤ
			取得分類コード	名称	
基盤地図情報に該当するもの	座標の基準	測量の基準点	7301～7312	三角点 等	S-SUV-SRVR
	地表の高さの基準	標高点			
		等高線(計曲線)の屈曲点	7101、7105	等高線(計曲線)等	S-SUV-HICN
		等高線(主曲線) の屈曲点	7102～7104、7106～7108	等高線(主曲線)等	S-SUV-LWCN
	面的・線的に画する基礎的なもの	海岸線	5106	海岸線	S-SUV-COLN (COastLiNe)
		公共施設の境界線(道路区域界)	6522	公共施設の境界線(道路区域界)	S-SUV-SLOP (SLOPe)
		公共施設の境界線(河川区域界)	6523	公共施設の境界線(道路区域界)	S-SUV-BRWA (BreakWAter)
		行政区画の境界線及び代表点	1101～1111	都府県界 等	S-SUV-BORD (BORDer)
			6511～6518	大字の境界 等	S-SUV-ROW
		道路縁	2101、2106～2109、2203、2204、2206	真幅道路 等	S-SUV-ROAD
		河川堤防の表法肩の法線	6103	表法肩の法線	S-SUV-EMBA (EMBAnkment)
		軌道の中心線	2301～2315	普通鉄道 等	S-SUV-RAIL (RAILload)
		水涯線	5101、5103、5104、5105	河川 等	S-SUV-RIV (RIVer)
		建築物の外周線	3001～3004	普通建物 等	S-SUV-STR (STRucture)

現行（令和６年３月）

4.　　レイヤの名称

付 4-3

CAD データのレイヤ名は、表１による。

表 1　測量作業で作成する CAD データのレイヤ名

項目			取得分類		CAD データのレイヤ
			取得分類コード	名称	
基盤地図情報に該当するもの	座標の基準	測量の基準点	7301～7312	三角点 等	S-SUV-SRVR
	地表の高さの基準	標高点			
		等高線(計曲線)の屈曲点	7101、7105	等高線(計曲線)等	S-SUV-HICN
		等高線(主曲線) の屈曲点	7102～7104、7106～7108	等高線(主曲線)等	S-SUV-LWCN
	面的・線的に画する基礎的なもの	海岸線	5106	海岸線	S-SUV-COLN (COastLiNe)
		公共施設の境界線(道路区域界)	6522	公共施設の境界線(道路区域界)	S-SUV-SLOP (SLOPe)
		公共施設の境界線(河川区域界)	6523	公共施設の境界線(道路区域界)	S-SUV-BRWA (BreakWAter)
		行政区画の境界線及び代表点	1101～1111	都府県界 等	S-SUV-BORD (BORDer)
			6511～6518	大字の境界 等	S-SUV-ROW
		道路縁	2101、2106～2109、2203、2204、2206	真幅道路 等	S-SUV-ROAD
		河川堤防の表法肩の法線	6103	表法肩の法線	S-SUV-EMBA (EMBAnkment)
		軌道の中心線	2301～2315	普通鉄道 等	S-SUV-RAIL (RAILload)
		水涯線	5101、5103、5104、5105	河川 等	S-SUV-RIV (RIVer)
		建築物の外周線	3001～3004	普通建物 等	S-SUV-STR (STRucture)

改定（令和７年 12 月）

付 4-4

表 1　測量作業で作成する CAD データのレイヤ名　のつづき

項目			取得分類		CAD データのレイヤ
基盤地図情報に該当するもの	地理識別子	行政区画の境界線及び代表点（再掲）	8110～8119	市・東京都の区	S-SUV-HTXT
		市町村の町若しくは字の境界線及び代表点			
		街区の境界線及び代表点			
その他		中心線	2505	中心線	S-SUV-CELN (CEnterLiNe)
		中心杭、IP 点 等	2501、2503、2504、6501、6502	中心杭、IP 点等	S-SUV-BMK (BenchMarK)
		整飾	7903、7904	タイトル(外枠)等	S-SUV-FRAM
			7906、7908	凡例(罫線) 等	S-SUV-LINE
			7901、7902、7905、7907、7911～7916	図枠(外枠) 等	S-SUV-TTL
		注記	(注記データ)		S-SUV-HTXT
		上記以外のデータ	(上記以外)		S-SUV

【解説】

CAD 製図基準では、CAD データのレイヤ名は、図 4 の原則に従い、レイヤの文字数は全体で 256 文字以内と規定されている。また、図面オブジェクトには、測量成果を格納するための「SUV」が割り当てられている（表 2 参照）。

測量作業で作成する CAD データは、全て S-SUV 以下のレイヤに格納することを基本とし、具体のレイヤ構成は、表 1 による。

現行（令和６年３月）

付 4-4

表 1　測量作業で作成する CAD データのレイヤ名　のつづき

項目			取得分類		CAD データのレイヤ
基盤地図情報に該当するもの	地理識別子	行政区画の境界線及び代表点（再掲）	8110～8119	市・東京都の区	S-SUV-HTXT
		市町村の町若しくは字の境界線及び代表点			
		街区の境界線及び代表点			
その他		中心線	2505	中心線	S-SUV-CELN (CEnterLiNe)
		中心杭、IP 点 等	2501、2503、2504、6501、6502	中心杭、IP 点等	S-SUV-BMK (BenchMarK)
		整飾	7903、7904	タイトル(外枠)等	S-SUV-FRAM
			7906、7908	凡例(罫線) 等	S-SUV-LINE
			7901、7902、7905、7907、7911～7916	図枠(外枠) 等	S-SUV-TTL
		注記	(注記データ)		S-SUV-HTXT
		上記以外のデータ	(上記以外)		S-SUV

【解説】

CAD 製図基準では、CAD データのレイヤ名は、図 4 の原則に従い、レイヤの文字数は全体で 256 文字以内と規定されている。また、図面オブジェクトには、測量成果を格納するための「SUV」が割り当てられている（表 2 参照）。

測量作業で作成する CAD データは、全て S-SUV 以下のレイヤに格納することを基本とし、具体のレイヤ構成は、表 1 による。

改定（令和７年 12 月）

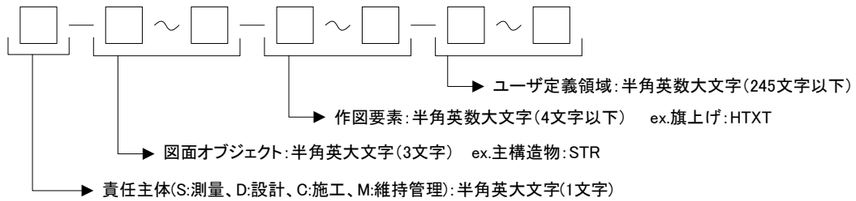

図 4　レイヤ名称の原則

付 4-5

表 2　レイヤの図面オブジェクトの分類

図面オブジェクト			記　載　内　容
1	図　　枠	TTL (TiTLe)	外枠、表題欄、罫線、文字、縦断図の帯枠
2	背　　景	BGD (BackGround Drawing)	主計曲線、現況地物、既設構造物　等
3	基　　準	BMK (BenchMarK)	基準点、測量ポイント、中心線、幅杭、　等
4	主構造物	STR (STRucture)	当該図面名称であらわす構造物
5	副構造物	BYP (BYProduct)	主構造図から派生する構造物
6	材 料 表	MTR (MaTeRial)	切盛土、コンクリート、鉄筋加工、 数量(購入品、規格　等)
7	説明､着色	DCR (DeCoRation)	ハッチ、シンボル、塗りつぶし、記号　等
8	文章	DOC (DOCument)	文章領域（説明事項、指示事項、参照事項、位置図）
9	測量	SUV (SUrVey)	地形図等の測量成果データであり改変しないデータ

現行（令和６年３月）

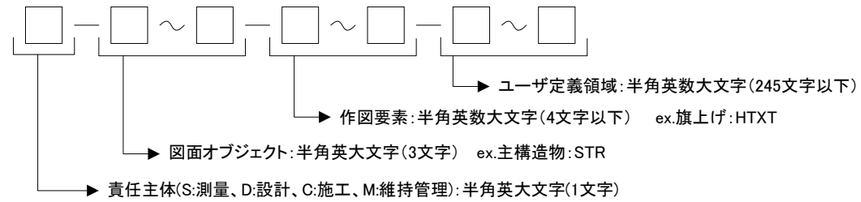

図 4　レイヤ名称の原則

付 4-5

表 2　レイヤの図面オブジェクトの分類

図面オブジェクト			記　載　内　容
1	図　　枠	TTL (TiTLe)	外枠、表題欄、罫線、文字、縦断図の帯枠
2	背　　景	BGD (BackGround Drawing)	主計曲線、現況地物、既設構造物　等
3	基　　準	BMK (BenchMarK)	基準点、測量ポイント、中心線、幅杭、　等
4	主構造物	STR (STRucture)	当該図面名称であらわす構造物
5	副構造物	BYP (BYProduct)	主構造図から派生する構造物
6	材 料 表	MTR (MaTeRial)	切盛土、コンクリート、鉄筋加工、 数量(購入品、規格　等)
7	説明､着色	DCR (DeCoRation)	ハッチ、シンボル、塗りつぶし、記号　等
8	文章	DOC (DOCument)	文章領域（説明事項、指示事項、参照事項、位置図）
9	測量	SUV (SUrVey)	地形図等の測量成果データであり改変しないデータ

改定（令和７年 12 月）

5.　CAD データの図式

付 4-5

CAD データの図式は、公共測量標準図式を適用する。

【解説】

公共測量標準図式は、大縮尺地形図図式（地図情報レベル 500 及び 1000）、国土基本図図式（地図情報レベル 2500 及び 5000）を包括した名称である。

CAD 製図基準では、CAD データで使用できる線種、線色、線幅、フォントなどの原則が定められているが、公共測量標準図式が、CAD 製図基準にすべて対応しているものではない。

測量作業で作成する CAD データの図式は、CAD 製図基準を適用せず、公共測量標準図式を適用する。

6.　属性情報

付 4-6

SAF ファイルに格納する属性情報は、表 3 による。

表 3　SAF ファイルに格納する属性情報

図面名称	図形名称	フィーチャー	属性名称	データ項目
―	―	既定義ハッチング	インデックスレコード	・座標系 ・計画機関名 ・使用した作業規程
			図郭レコード	・図郭識別番号 ・地図情報レベル ・左下図郭情報 ・右上図郭情報 ・左上図郭情報 ・右下図郭情報
		折線フィーチャー	要素レコード	・取得分類コード ・図形区分 ・精度区分 ・転位区分 ・間断区分 ・属性数値 ・取得年月 ・更新の取得年月
			三次元座標レコード	・Z 座標値

現行（令和６年３月）

5.　CAD データの図式

付 4-5

CAD データの図式は、公共測量標準図式を適用する。

【解説】

公共測量標準図式は、大縮尺地形図図式（地図情報レベル 500 及び 1000）、国土基本図図式（地図情報レベル 2500 及び 5000）を包括した名称である。

CAD 製図基準では、CAD データで使用できる線種、線色、線幅、フォントなどの原則が定められているが、公共測量標準図式が、CAD 製図基準にすべて対応しているものではない。

測量作業で作成する CAD データの図式は、CAD 製図基準を適用せず、公共測量標準図式を適用する。

6.　属性情報

付 4-6

SAF ファイルに格納する属性情報は、表 3 による。

表 3　SAF ファイルに格納する属性情報

図面名称	図形名称	フィーチャー	属性名称	データ項目
―	―	既定義ハッチング	インデックスレコード	・座標系 ・計画機関名 ・使用した作業規程
			図郭レコード	・図郭識別番号 ・地図情報レベル ・左下図郭情報 ・右上図郭情報 ・左上図郭情報 ・右下図郭情報
		折線フィーチャー	要素レコード	・取得分類コード ・図形区分 ・精度区分 ・転位区分 ・間断区分 ・属性数値 ・取得年月 ・更新の取得年月
			三次元座標レコード	・Z 座標値

改定（令和７年 12 月）

				属性レコード	・路線中心 ・撮影コース
			円フィーチャー 円弧フィーチャー	要素レコード	・取得分類コード ・図形区分 ・精度区分 ・転位区分 ・間断区分 ・属性数値 ・取得年月 ・更新の取得年月
				三次元座標レコード	・Z 座標値
				属性レコード	・路線中心
			点マーカフィーチャー	要素レコード	・取得分類コード ・図形区分 ・精度区分 ・転位区分 ・間断区分 ・属性数値 ・取得年月 ・更新の取得年月
				不整三角網ヘッダレコード	・取得分類コード

付 4-7

表 3　SAF ファイルに格納する属性情報　のつづき

図面名称	図形名称	フィーチャー	属性名称	データ項目
―	―		三次元座標レコード	・Z 座標値
			属性レコード	・路線測点
			グリッドコード	・数値(1)～(12)
			不整三角網レコード	・座標値
		文字要素フィーチャー	要素レコード	・取得分類コード ・図形区分 ・精度区分 ・転位区分 ・間断区分 ・属性数値 ・取得年月

現行（令和６年３月）

				属性レコード	・路線中心 ・撮影コース
			円フィーチャー 円弧フィーチャー	要素レコード	・取得分類コード ・図形区分 ・精度区分 ・転位区分 ・間断区分 ・属性数値 ・取得年月 ・更新の取得年月
				三次元座標レコード	・Z 座標値
				属性レコード	・路線中心
			点マーカフィーチャー	要素レコード	・取得分類コード ・図形区分 ・精度区分 ・転位区分 ・間断区分 ・属性数値 ・取得年月 ・更新の取得年月
				不整三角網ヘッダレコード	・取得分類コード

付 4-7

表 3　SAF ファイルに格納する属性情報　のつづき

図面名称	図形名称	フィーチャー	属性名称	データ項目
―	―		三次元座標レコード	・Z 座標値
			属性レコード	・路線測点
			グリッドコード	・数値(1)～(12)
			不整三角網レコード	・座標値
		文字要素フィーチャー	要素レコード	・取得分類コード ・図形区分 ・精度区分 ・転位区分 ・間断区分 ・属性数値 ・取得年月

改定（令和７年 12 月）

				・更新の取得年月
		既定義シンボル	要素レコード	・取得分類コード ・図形区分 ・精度区分 ・転位区分 ・間断区分 ・属性数値 ・取得年月 ・更新の取得年月

【解説】

標準図式データファイルが保有する属性情報には、取得分類コード、精度、取得年月など設計・施工などの後工程での利用時において有益な情報が含まれる。これまでは、標準図式データファイルを SXF(P21)ファイルに変換した場合、これらの属性情報が失われていたが、SXF Ver.3.0 レベル 2 以上の属性ファイル用属性付加機構を利用して、SAF ファイルに表 3 の情報を格納する。

現行（令和６年３月）

				・更新の取得年月
		既定義シンボル	要素レコード	・取得分類コード ・図形区分 ・精度区分 ・転位区分 ・間断区分 ・属性数値 ・取得年月 ・更新の取得年月

【解説】

標準図式データファイルが保有する属性情報には、取得分類コード、精度、取得年月など設計・施工などの後工程での利用時において有益な情報が含まれる。これまでは、標準図式データファイルを SXF(P21)ファイルに変換した場合、これらの属性情報が失われていたが、SXF Ver.3.0 レベル 2 以上の属性ファイル用属性付加機構を利用して、SAF ファイルに表 3 の情報を格納する。